Montag 06.04.2026

Aktualisiert am 06.04.2026 um 08:00

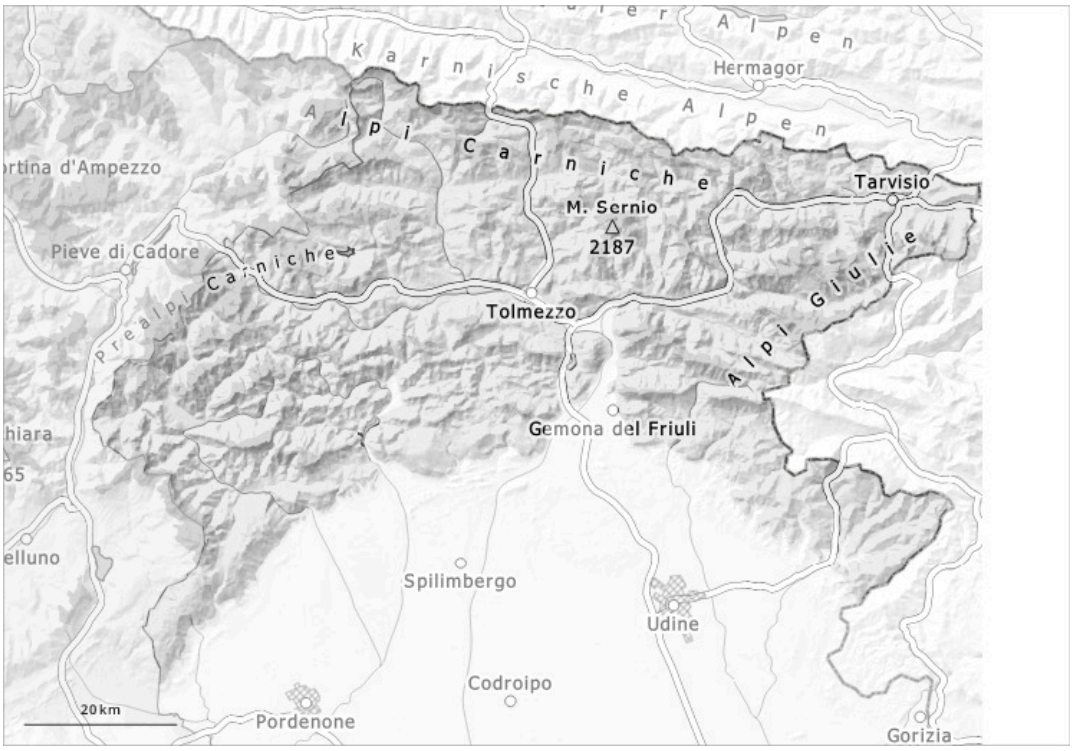

1	2	3	4	5
gering	mäßig	erheblich	groß	sehr groß

Gefahrenstufe 2 - Mäßig

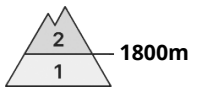

1800m

Tendenz: Lawinengefahr bleibt gleich
am Dienstag, den 07.04.2026

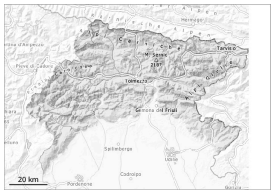

Triebschnee

1800m

Altschnee

1800m

Nassschnee

Waldgrenze

Die Gefahrenstellen nehmen im Tagesverlauf zu.

Die Triebschneeansammlungen müssen vorsichtig beurteilt werden. Die Gefahrenstellen liegen vor allem an Felswandfüßen, sowie in Kammlagen, Rinnen und Mulden. Die Triebschneeansammlungen können noch ausgelöst werden. Dies vor allem mit großer Belastung. Die Mitreiß- und Absturzgefahr sollte beachtet werden. Mit der Erwärmung sind im Tagesverlauf feuchte und nasse Lawinen möglich. Die Lawinen können in tiefen Schichten anreißen. Zudem sind Gleitschneelawinen möglich. Touren sollten früh gestartet und beendet werden.

Schneedecke

The snowpack's surface remains generally characterized by alternating eroded areas interspersed with deposited zones; in many areas, hard surface crusts are present, locally hidden. Near the crests, evident cornices remain in many places. In der Schneedecke sind vor allem an Schattenhängen Schwachschichten vorhanden. Die Wetterbedingungen führen im Tagesverlauf zu einer allmählichen Durchnässung der Schneedecke.

Tendenz

Es ist teils bewölkt. Kontinuierliche Erwärmung.
Die Wetterbedingungen führen zu einer allmählichen Durchnässung der Schneedecke.