Lunedì 06.04.2026

Aggiornato06.04.2026 alle ore 08:00

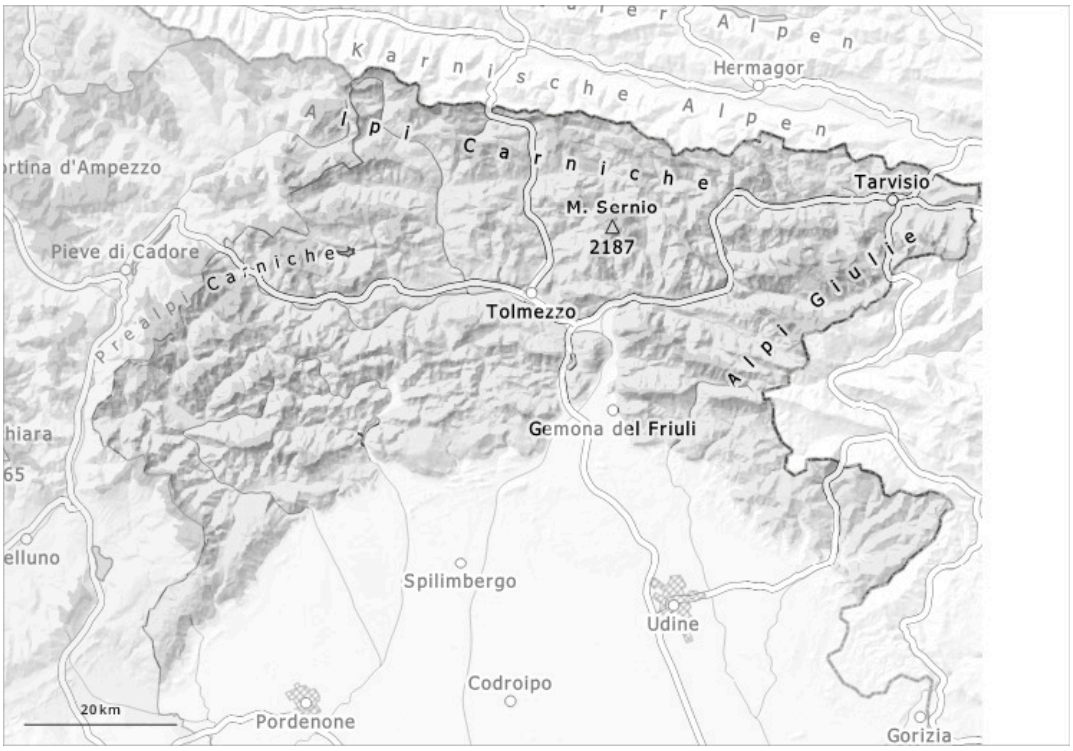

1	2	3	4	5
debole	moderato	marcato	forte	molto forte

Grado di pericolo 2 - Moderato

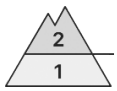

1800m

Tendenza: pericolo valanghe stabile
per Martedì il 07.04.2026

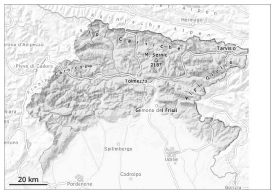

Lastrone da vento

1800m

Strati deboli persistenti

1800m

Neve bagnata

Limite del bosco

I punti pericolosi aumenteranno nel corso della giornata.

Gli accumuli di neve ventata devono essere valutati con attenzione. I punti pericolosi si trovano soprattutto nelle basi di pareti rocciose, come pure nelle zone in prossimità delle creste, nei canaloni e nelle conche. Gli accumuli di neve ventata possono ancora subire un distacco provocato. Ciò soprattutto in seguito a un forte sovraccarico. Attenzione al pericolo di trascinamento e di caduta. Con il rialzo termico, nel corso della giornata sono possibili valanghe umide e bagnate. Le valanghe possono coinvolgere gli strati più profondi del manto nevoso. Inoltre sono possibili valanghe per scivolamento di neve. Le escursioni dovrebbero iniziare e terminare presto.

Manto nevoso

La superficie del manto nevoso rimane caratterizzata, a livello generale, da un'alternanza di zone erose intervallate a zone di deposito; in molte aree sono presenti dure croste superficiali, localmente nascoste. In prossimità delle creste permangono in molti punti evidenti cornici. Soprattutto sui pendii ombreggiati, all'interno del manto nevoso si trovano strati fragili. Nel corso della giornata le condizioni meteo causeranno un graduale impregnamento del manto nevoso.

Tendenza

Il tempo sarà in parte nuvoloso. Continuo rialzo termico.
Le condizioni meteo causeranno un graduale impregnamento del manto nevoso.