BUTLLETÍ DEL PERILL D'ALLAUS DEL PRINCIPAT D'ANDORRA

Servei meteorològic nacional
Principat d'Andorra

Elaborat el 06/04/2026 07:34
Propera actualització 06/04/2026 a les 16h

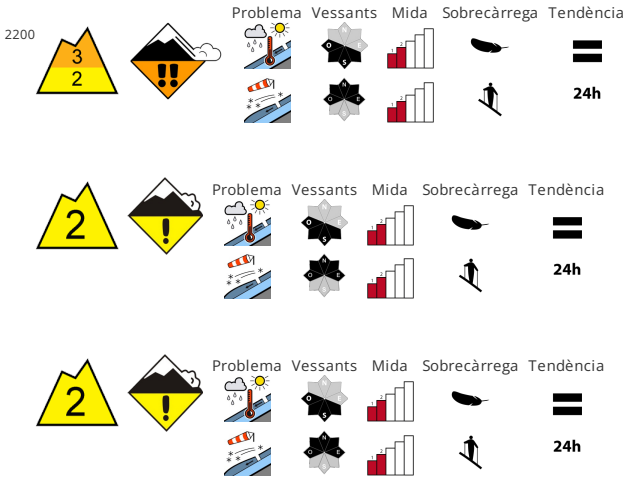

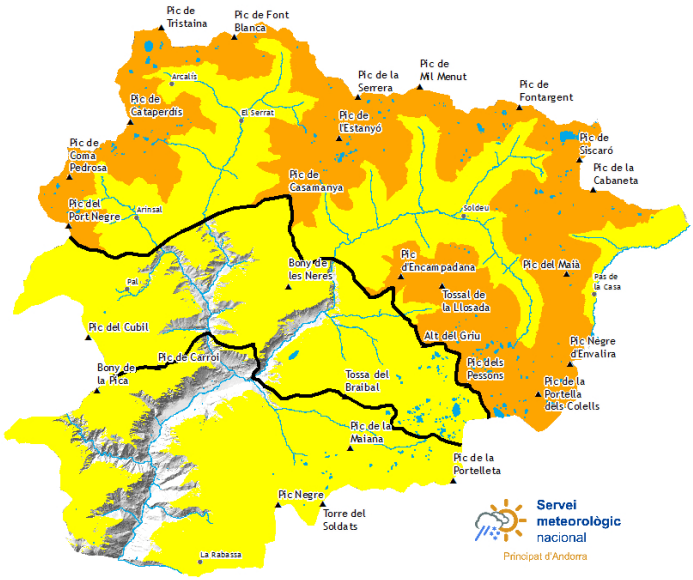

ESTABILITAT DEL MANTELL NIVAL

A conseqüència de l'augment de la temperatura diürna i la radiació solar, en el transcurs de la jornada són possibles allaus de neu seca i humida, fins i tot de mida mitjana. A més, són possibles allaus de lliscament basal. Això s'aplica principalment en vessants assolellats i per sota dels 2200 m aproximadament. Als vessants obacs , són encara possibles allaus de placa seca. Les allaus són sovint de mida mitjana i poden ser desencadenades per un sol muntanyenc. Les excursions de muntanya i les activitats forapista requereixen experiència en l'avaluació del perill d'allaus i precaució.

QUALITAT DE LA NEU

Les noves acumulacions de neu ventada descansen a sobre de capes toves. El mantell de neu roman extremadament variable en pocs metres de manera generalitzada. Prop de les carenes els gruixos de neu varien molt per la influència del vent. El temps serà assolellat. Amb la pujada de temperatures la radiació solar, durant els propers dies el mantell de neu s'assentarà.

GRUIXOS DEL MANTELL NIVAL FORA DE PISTA

Zona nord		Gruix neu		
Mantell Nival		1500m	2000m	2500m
N	1300 m	20 cm	180 cm	250 cm
S	1300 m	10 cm	150 cm	200 cm

Zona centre		Gruix neu		
Mantell Nival		1500m	2000m	2500m
N	1300 m	10 cm	150 cm	200 cm
S	1500 m	5 cm	100 cm	150 cm

Zona sud		Gruix neu		
Mantell Nival		1500m	2000m	2500m
N	1300 m	10 cm	120 cm	160 cm
S	1500 m	5 cm	60 cm	120 cm

Govern d'Andorra

EAWS EUROPEAN AVALANCHE WARNING SERVICES

Aquest butlletí ha estat elaborat seguint les normes i recomanacions de l'**European Avalanche Warning Services**, del qual el **Servei meteorològic Nacional** n'és membre

BUTLLETÍ DEL PERILL D'ALLAUS DEL PRINCIPAT D'ANDORRA

Servei meteorològic nacional
Principat d'Andorra

Informació detallada per espais naturals protegits

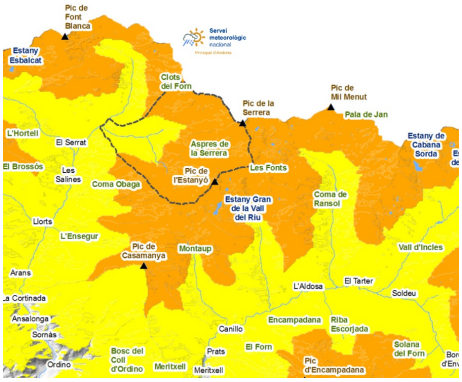

SORTENY

Les nevades successives que van afectar sobretot el nord d´Andorra van deixar condicions hivernals. Amb l´augment de les temperatures i la radiació solar trobarem una neu tova i amb condicions primaverals a mida que avanci la jornada. Als vessants obacs encara podem trobar neu ventada, lleugerament més dura.

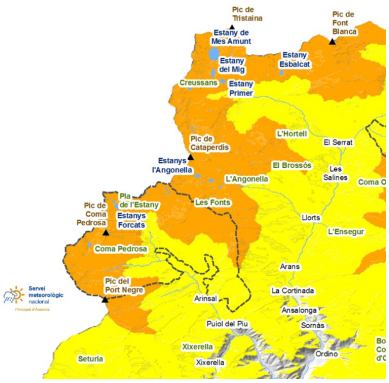

COMAPEDROSA

A la part superficial dem mantell trobem plaques de vent, ocultes sota la neu recent de mitja setmana i difícilment identificables. Atès que bona part del terreny del Parc és complex o exigent, les condicions són delicades per les excursions amb esquís i raquetes de neu.

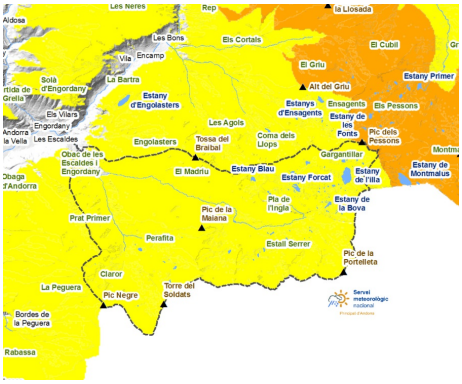

MADRIU-PERAFITA-CLAROR

La neu ha tornat a totes les cotes de la vall, però recularà ràpid de les cotes baixes. A cotes altes l´ambient encara és hivernal. Haurem de circular amb molta precaució, mantenint la distància de seguretat.

Govern d'Andorra

EAWS
EUROPEAN AVALANCHE WARNING SERVICES

Aquest butlletí ha estat elaborat seguint les normes i recomanacions de l'**European Avalanche Warning Services**, del qual el **Servei meteorològic Nacional** n'és membre

BUTLLETÍ DEL PERILL D'ALLAUS DEL PRINCIPAT D'ANDORRA

Servei meteorològic nacional
Principat d'Andorra

Gruixos de neu nova dels darrers dies (de les últimes 24h mesurat a les 06:00h UTC)

	02/04/2026	03/04/2026	04/04/2026	05/04/2026
FEDA (Central)	0 cm	0 cm	0 cm	0 cm
Engolasters - FEDA	0 cm	0 cm	0 cm	0 cm
Bony de les Neres	0 cm	0 cm	0 cm	0 cm
Les Fonts d'Arinsal	0 cm	0 cm	0 cm	0 cm
Perafita	30 cm	0 cm	0 cm	0 cm
Tossa Espiolets	27 cm	0 cm	0 cm	0 cm
Grau Roig - FEDA	0 cm	0 cm	0 cm	0 cm
Fontverd	0 cm	0 cm	0 cm	0 cm
Coll Ordino	0 cm	0 cm	0 cm	0 cm
Ransol - FEDA	3 cm	0 cm	0 cm	0 cm
Setúria	4 cm	0 cm	0 cm	0 cm
Caborreu	1 cm	0 cm	0 cm	0 cm
La Solana	4 cm	0 cm	0 cm	0 cm
Coll Pa	7 cm	0 cm	0 cm	0 cm
Vall del Riu FEDA	13 cm	0 cm	0 cm	0 cm