# BUTLLETÍ DEL PERILL D'ALLAUS DEL PRINCIPAT D'ANDORRA

Elaborado el 06/04/2026 07:34
Proxima actualización 06/04/2026 a las 16h

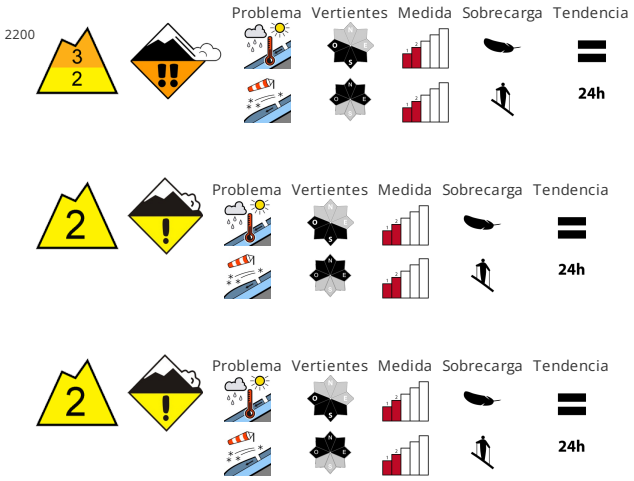


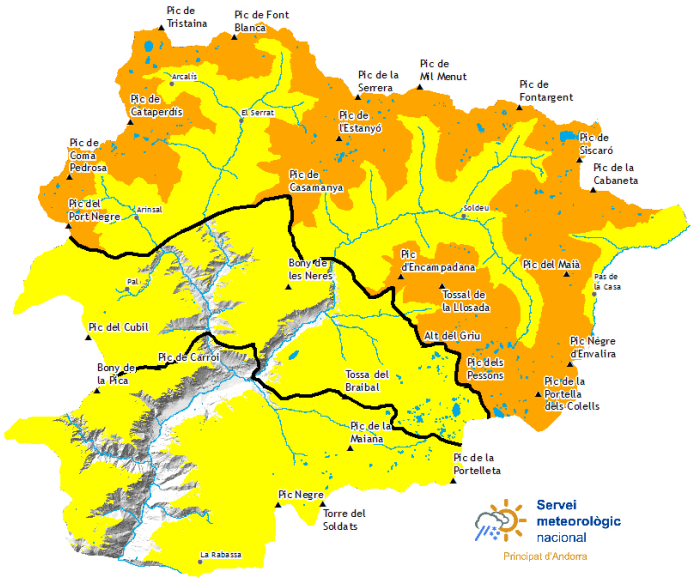


## CALIDAD DE LA NIEVE

A consecuencia del aumento de la temperatura diurna y la radiación solar, en el transcurso de la jornada son posibles avalanchas de nieve seca y húmeda, incluso de tamaño mediano. Además son posibles aludes de deslizamiento basal. Esto se da principalmente en las laderas solanas y por debajo de los 2200 m aproximadamente. En las laderas umbrías , son posibles avalanchas de placa seca. Los aludes son a menudo de tamaño mediano y pueden ser desencadenados por un solo montañero. Las excursiones de montaña y las actividades fuera pista requieren experiencia en la evaluación del peligro de aludes y precaución.

## ESTABILIDAD DEL MANTO NIVOSO

Las nuevas acumulaciones de nieve venteada descansan encima de capas blandas. El manto de nieve permanece extremadamente variable en pocos metros en general. Cerca de los cordales los espesores de nieve varían mucho por la influencia del viento. El tiempo será soleado. Con la subida de temperaturas la radiación solar, durante los próximos días el manto de nieve se asentará.

## ESPESORES DEL MANTO NIVOSO FUERA DE PISTA

| Zona norte | | Espesor nieve | | |
|---|---|---|---|---|
| **Manto Nival** | | 1500m | 2000m | 2500m |
| N | 1300 m | 20 cm | 180 cm | 250 cm |
| S | 1300 m | 10 cm | 150 cm | 200 cm |

| zona centro | | Espesor nieve | | |
|---|---|---|---|---|
| **Manto Nival** | | 1500m | 2000m | 2500m |
| N | 1300 m | 10 cm | 150 cm | 200 cm |
| S | 1500 m | 5 cm | 100 cm | 150 cm |

| Zona sur | | Espesor nieve | | |
|---|---|---|---|---|
| **Manto Nival** | | 1500m | 2000m | 2500m |
| N | 1300 m | 10 cm | 120 cm | 160 cm |
| S | 1500 m | 5 cm | 60 cm | 120 cm |

Govern d'Andorra

Aquest butlletí ha estat elaborat seguint les normes i recomanacions de l'**European Avalanche Warning Services**, del qual el **Servei meteorològic Nacional** n'és membre

## Información detallada por espacios naturales protegidos

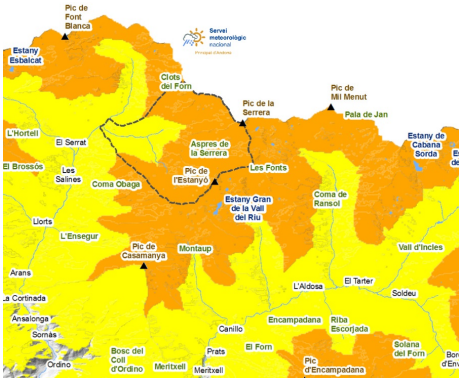


### SORTENY

Las sucesivas nevadas que afectaron sobre todo al norte de Andorra dejaron condiciones invernales. Con el aumento de las temperaturas y la radiación solar encontraremos una nieve blanda y con condiciones primaverales a medida que avance la jornada. En las vertientes umbrías todavía podemos encontrar nieve venteada, ligeramente más dura.

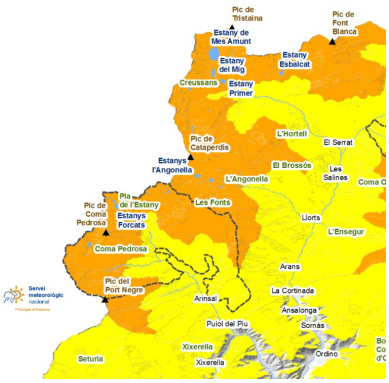


### COMAPEDROSA

En la parte superficial del manto encontramos placas de viento, ocultas bajo la nieve reciente de media semana y difícilmente identificables. Dado que buena parte del terreno del Parque es complejo o exigente, las condiciones son delicadas por las excursiones en esquís y raquetas de nieve.

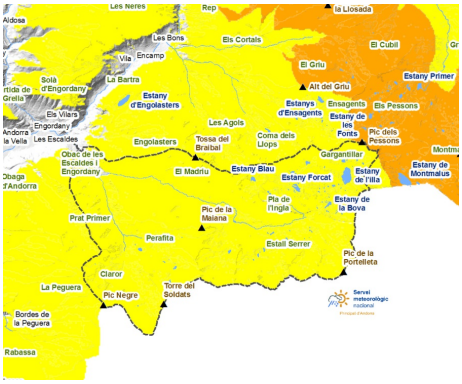


### MADRIU-PERAFITA-CLAROR

La nieve ha vuelto a todas las cotas del valle, pero retrocederá rápido de las cotas bajas. En cotas altas el ambiente es aún invernal. Deberemos circular con mucha precaución, manteniendo la distancia de seguridad.

# BUTLLETÍ DEL PERILL D'ALLAUS DEL PRINCIPAT D'ANDORRA

Servei meteorològic nacional
Principat d'Andorra

## Espesores de nieve nueva de los últimos días (de las ultimas 24h mesurado a las 06:00h UTC)

| | 02/04/2026 | 03/04/2026 | 04/04/2026 | 05/04/2026 |
|---|---|---|---|---|
| **FEDA (Central)** | 0 cm | 0 cm | 0 cm | 0 cm |
| **Engolasters - FEDA** | 0 cm | 0 cm | 0 cm | 0 cm |
| **Bony de les Neres** | 0 cm | 0 cm | 0 cm | 0 cm |
| **Les Fonts d'Arinsal** | 0 cm | 0 cm | 0 cm | 0 cm |
| **Perafita** | 30 cm | 0 cm | 0 cm | 0 cm |
| **Tossa Espiolets** | 27 cm | 0 cm | 0 cm | 0 cm |
| **Grau Roig - FEDA** | 0 cm | 0 cm | 0 cm | 0 cm |
| **Fontverd** | 0 cm | 0 cm | 0 cm | 0 cm |
| **Coll Ordino** | 0 cm | 0 cm | 0 cm | 0 cm |
| **Ransol - FEDA** | 3 cm | 0 cm | 0 cm | 0 cm |
| **Setúria** | 4 cm | 0 cm | 0 cm | 0 cm |
| **Caborreu** | 1 cm | 0 cm | 0 cm | 0 cm |
| **La Solana** | 4 cm | 0 cm | 0 cm | 0 cm |
| **Coll Pa** | 7 cm | 0 cm | 0 cm | 0 cm |
| **Vall del Riu FEDA** | 13 cm | 0 cm | 0 cm | 0 cm |