BUTLLETÍ DEL PERILL D'ALLAUS DEL PRINCIPAT D'ANDORRA

Préparé le 06/04/2026 07:34
Prochaine mise à jour le 06/04/2026 à 16h

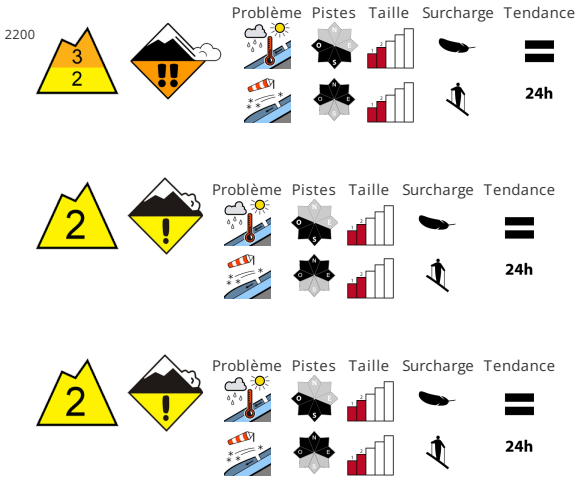

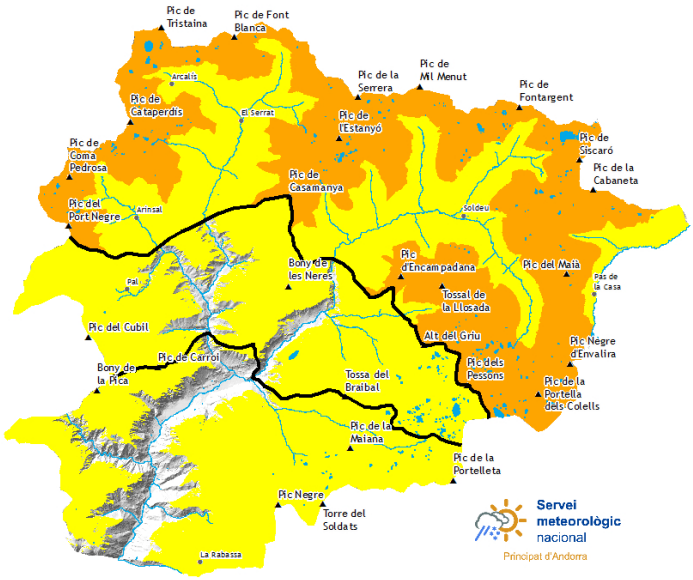

STABILITÉ DU MANTEAU NEIGEUX

Avec le réchauffement diurne et le rayonnement solaire en cours de journée des avalanches sèches et humides sont possibles ils sont , également de taille moyenne. En outre, des avalanches de glissement sont possibles.. Ceci particulièrement sur les pentes ensoleillées et en dessous d'environ 2200 m. Des avalanches de plaque de neige sèche sont ils sont possibles sur les pentes à l'ombre. Les avalanches sont souvent de taille moyenne et déclenchables par un seul amateur de sports d'hiver.. Les randonnées et descentes hors-piste demandent de l' expérience dans l'évaluation du danger d'avalanche et de la retenue.

QUALITÈ DE LA NEIGE

Les accumulations récentes de neige soufflée reposent sur des couches meubles. De manière généralisée le manteau neigeux reste très variable à petite échelle.. À proximité des crêtes on trouve suivant l'influence du vent des hauteurs de neiges très différentes. Il fait un temps ensoleillé. Avec le réchauffement le rayonnement solaire le manteau neigeux se tasse dans les prochains jours.

EPAISSEUR DE NEIGE HORS PISTE

Zone nord		Epaisseur de neige		
Nival manteau		1500m	2000m	2500m
N	1300 m	20 cm	180 cm	250 cm
S	1300 m	10 cm	150 cm	200 cm

Zone centre		Epaisseur de neige		
Nival manteau		1500m	2000m	2500m
N	1300 m	10 cm	150 cm	200 cm
S	1500 m	5 cm	100 cm	150 cm

Zone sud		Epaisseur de neige		
Nival manteau		1500m	2000m	2500m
N	1300 m	10 cm	120 cm	160 cm
S	1500 m	5 cm	60 cm	120 cm

Govern d'Andorra

Aquest butlletí ha estat elaborat seguint les normes i recomanacions de l'**European Avalanche Warning Services**, del qual el **Servei meteorològic Nacional** n'és membre

BUTLLETÍ DEL PERILL D'ALLAUS DEL PRINCIPAT D'ANDORRA

Servei meteorològic nacional
Principat d'Andorra

Des informations détaillées par espace naturel protégé

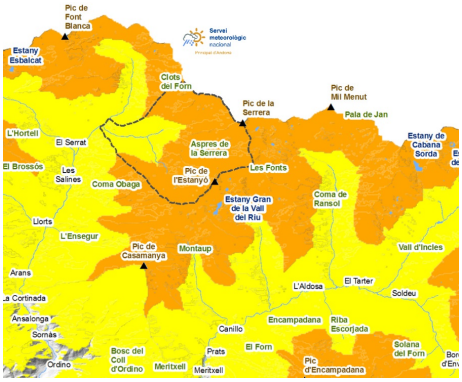

SORTENY

Les chutes de neige successives qui ont touché principalement le nord d'Andorre ont laissé des conditions hivernales. Avec l'augmentation des températures et du rayonnement solaire, nous retrouverons de la neige molle et des conditions printanières au fur et à mesure de la journée. Sur les pentes opaques on trouve encore de la neige venteuse, légèrement plus dure. , , , , ,

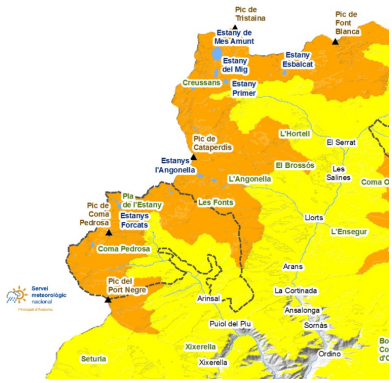

COMAPEDROSA

Dans la partie superficielle du manteau on trouve des plaques de vent, cachées sous la neige récente de milieu de semaine et difficiles à identifier. Étant donné qu'une grande partie du terrain du parc est complexe ou exigeant, les conditions sont délicates pour les excursions en ski et en raquettes. , , ,

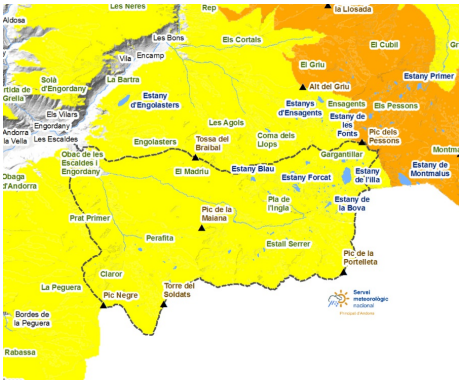

MADRIU-PERAFITA-CLAROR

La neige est revenue à toutes les altitudes de la vallée, mais reculera rapidement des altitudes inférieures. À haute altitude, l'atmosphère est encore hivernale. Nous devrons conduire très prudemment, en gardant une distance de sécurité. , , , , ,

Govern d'Andorra

EAWS
EUROPEAN AVALANCHE WARNING SERVICES

Aquest butlletí ha estat elaborat seguint les normes i recomanacions de l'**European Avalanche Warning Services**, del qual el **Servei meteorològic Nacional** n'és membre

BUTLLETÍ DEL PERILL D'ALLAUS DEL PRINCIPAT D'ANDORRA

Servei meteorològic nacional
Principat d'Andorra

Couche de neige fraiche des derniers jours (De 24 h mesurée à 06:00 h UTC)

	02/04/2026	03/04/2026	04/04/2026	05/04/2026
FEDA (Central)	0 cm	0 cm	0 cm	0 cm
Engolasters - FEDA	0 cm	0 cm	0 cm	0 cm
Bony de les Neres	0 cm	0 cm	0 cm	0 cm
Les Fonts d'Arinsal	0 cm	0 cm	0 cm	0 cm
Perafita	30 cm	0 cm	0 cm	0 cm
Tossa Espiolets	27 cm	0 cm	0 cm	0 cm
Grau Roig - FEDA	0 cm	0 cm	0 cm	0 cm
Fontverd	0 cm	0 cm	0 cm	0 cm
Coll Ordino	0 cm	0 cm	0 cm	0 cm
Ransol - FEDA	3 cm	0 cm	0 cm	0 cm
Setúria	4 cm	0 cm	0 cm	0 cm
Caborreu	1 cm	0 cm	0 cm	0 cm
La Solana	4 cm	0 cm	0 cm	0 cm
Coll Pa	7 cm	0 cm	0 cm	0 cm
Vall del Riu FEDA	13 cm	0 cm	0 cm	0 cm