MINISTERO DELLA DIFESA

meteomont
Servizio Nazionale di previsione neve e valanghe

EAWS EUROPEAN AVALANCHE WARNING SERVICES

CARABINIERI

# ALPI OROBICHE

Bollettino Valanghe N. 395/2026 del 05/04/2026 ore 14.00
Validità 48 ore prossima emissione 06/04/2026

**A cura del Servizio METEOMONT dell'ARMA dei CARABINIERI**
**In collaborazione con Servizio Meteorologico dell'Aeronautica militare**

## SITUAZIONE alle 14:00 del 05/04/2026

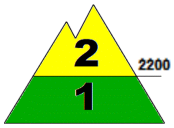


**SITUAZIONE TIPO: passaggio da poca a molta neve.**




**SITUAZIONE TIPO: situazione primaverile.**

| Quota neve (mslm) | Nord | Sud |
|---|---|---|
| | 1600 - 1800 | 2100 - 2200 |

| Altezza Neve (cm) | Neve al suolo | Neve Fresca | Quota (mslm) |
|---|---|---|---|
| | 145 | 0 | 2080 |
| | 53 | 0 | 1760 |

**VALANGHE OSSERVATE: Nessuna valanga.**

## PREVISIONI 06/04/2026

## GRADO DI PERICOLO: MODERATO 2

## SITUAZIONE TIPO: passaggio da poca a molta neve.

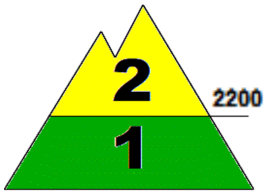


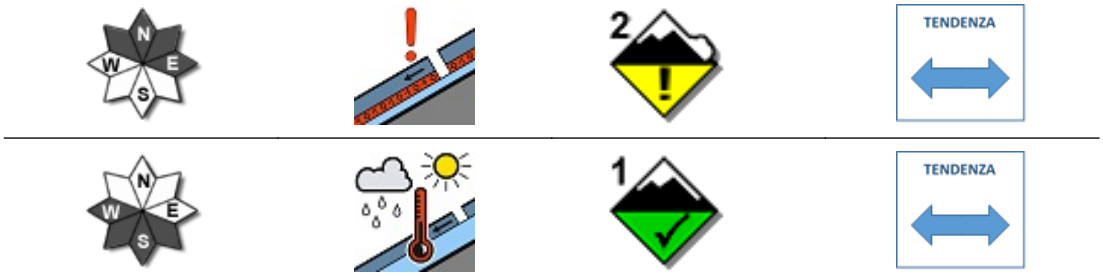


## SITUAZIONE TIPO: situazione primaverile.

**MANTO NEVOSO: La stabilità del manto nevoso è scarsa su alcuni punti (aree) per versanti in ombra al di sopra di 2200 mslm, possibili valanghe di dimensioni medie.**
**La stabilità del manto nevoso è buona su pochi punti (aree) per versanti al sole al di sotto di 2200 mslm, possibili valanghe di dimensioni piccole.**

## AVVERTENZE

A seguito dell'attività eolica registrata sono da evitare le zone di accumulo, conche, canaloni, cambi di pendenza e pendii sotto vento in genere.

## SCALA EUROPEA DEL GRADO DI PERICOLO VALANGHE

5 - MOLTO FORTE | 4 - FORTE | 3 - MARCATO | 2 - MODERATO | 1 - DEBOLE | NO NEVE | NO INFO

## LEGENDA PROBLEMA

NEVE FRESCA | LASTRONI DA VENTO | STRATI DEBOLI PERSISTENTI | NEVE BAGNATA | SLITTAMENTO | CORNICI | NESSUN PROBLEMA VALANGHIVO EVIDENTE | NO_INFO

**Bollettino realizzato su scala sinottica-regionale (standard EAWS). La sua valutazione non può escludere in alcun modo la necessità di una seria e capace valutazione locale del pericolo (singolo pendio) che può essere anche sensibilmente diverso. Le previsioni meteorologiche sono relative all'orario UTC (per l'Italia +1 in inverno e +2 in estate).**

# ALPI OROBICHE

## PREVISIONE METEO

| Quota | | 06/04/2026 h6:00 | 06/04/2026 h12:00 | 06/04/2026 h18:00 |
|---|---|---|---|---|
| 1000 | Venti | 01 nodi da N-Ovest | 02 Nodi da Nord | 03 Nodi da Nord |
| | Temperature | +08 °C | +09 °C | +03 °C |
| | Temp.percepita | 8 °C | 9 °C | 2 °C |
| 2000 | Venti | 01 nodi da N-Ovest | 01 Nodi da Nord | 03 Nodi da Nord |
| | Temperature | +07 °C | +08 °C | +08 °C |
| | Temp.percepita | 7 °C | 8 °C | 7 °C |
| 3000 | Venti | 08 nodi da N-Ovest | 04 nodi da N-Ovest | 04 nodi da N-Ovest |
| | Temperature | +00 °C | +01 °C | +02 °C |
| | Temp.percepita | -4 °C | -1 °C | -0 °C |
| Zero termico | | 2800-3000 m. | 3000-3200 m. | 3200-3400 m. |
| Fenomeno | | — | — | — |
| Stato del cielo | | | | |

## LEGENDA FENOMENI

— Assenza Fenomeni · Nebbia · Foschia · Pioggia debole · Pioggia moderata · Pioggia forte · Temporali

Nevicata debole · Nevicata moderata · Nevicata forte

## STATO DEL CIELO

Sereno · Poco nuvoloso · Nuvoloso · Molto nuvoloso · Coperto

## Parametri meteonivometrici registrati presso i campi di rilevamento il 05/04/2026.

| Località | Comune | Quota (m.s.l.m.) | Altezza neve (cm) | Neve caduta nelle 24 ore (cm) | Temp. Min (°C) | Temp. Max (°C) | Condizioni del tempo |
|---|---|---|---|---|---|---|---|
| QUARTA BAITA | Foppolo (BG) | 1760 | 53 | 0 | 0 | +5 | Assenza di precipitazioni |
| CIMA BIANCA | Colere (BG) | 2080 | 145 | 0 | +1 | +11 | Assenza di precipitazioni |

**(*) Rilievi fuori campo**

**L'INFORMAZIONE E' PREVENZIONE - LEGGI L'ATTUALE GRADO DI PERICOLO VALANGHE!**

**IL CAPO DEL CENTRO NAZIONALE METEOMONT**
**(Ten. Col. RFI Emanuela Gini)**
**FIRMA AUTOGRAFA OMESSA AI SENSI**
**DELL'ART.3 DEL D.LGS N.39/1993**