MINISTERO DELLA DIFESA

meteomont
Servizio Nazionale di previsione neve e valanghe

EAWS EUROPEAN AVALANCHE WARNING SERVICES

CARABINIERI

# GRAN SASSO OVEST

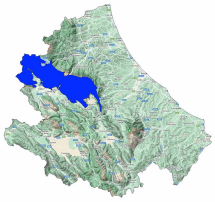

Bollettino Valanghe N. 385/2026 del 05/04/2026 ore 14.00
Validità 48 ore prossima emissione 06/04/2026

**A cura del Servizio METEOMONT dell'ARMA dei CARABINIERI**
**In collaborazione con Servizio Meteorologico dell'Aeronautica militare**

## SITUAZIONE alle 14:00 del 05/04/2026

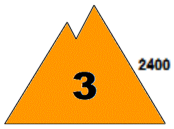


**SITUAZIONE TIPO: neve a debole coesione e vento.**

**SITUAZIONE TIPO: situazione primaverile.**

| Quota neve (mslm) | Nord | Sud |
|---|---|---|
| | 1100 - 1200 | 1200 - 1300 |

| Altezza Neve (cm) | Neve al suolo | Neve Fresca | Quota (mslm) |
|---|---|---|---|
| | 212 | 000 | 2135 |
| | 023 | 000 | 1400 |

**VALANGHE OSSERVATE: Alcune valanghe di medie dimensioni, Valanghe a lastroni di superficie.**

## PREVISIONI 06/04/2026

## GRADO DI PERICOLO: MARCATO 3

### SITUAZIONE TIPO: neve a debole coesione e vento.




### SITUAZIONE TIPO: situazione primaverile.

**MANTO NEVOSO: La stabilità del manto nevoso è scarsa su alcuni punti (aree) per tutte le esposizioni al di sopra di 2400 mslm, possibili valanghe di dimensioni grandi.**
**La stabilità del manto nevoso è scarsa su alcuni punti (aree) per tutte le esposizioni al di sotto di 2400 mslm, possibili valanghe di dimensioni grandi.**

## AVVERTENZE

Evitare le attività al di fuori delle piste battute e segnalate nelle ore più calde della giornata specialmente sui pendii ripidi esposti al sole, alla base di salti di roccia.

## SCALA EUROPEA DEL GRADO DI PERICOLO VALANGHE

## LEGENDA PROBLEMA

**Bollettino realizzato su scala sinottica-regionale (standard EAWS). La sua valutazione non può escludere in alcun modo la necessità di una seria e capace valutazione locale del pericolo (singolo pendio) che può essere anche sensibilmente diverso. Le previsioni meteorologiche sono relative all'orario UTC (per l'Italia +1 in inverno e +2 in estate).**

MINISTERO DELLA DIFESA

meteomont
Servizio Nazionale di previsione neve e valanghe

EAWS EUROPEAN AVALANCHE WARNING SERVICES

CARABINIERI

# GRAN SASSO OVEST

## PREVISIONE METEO

| Quota | | 06/04/2026 h6:00 | 06/04/2026 h12:00 | 06/04/2026 h18:00 |
|---|---|---|---|---|
| 1000 | Venti | 04 Nodi da Nord | 04 Nodi da Nord | 04 Nodi da Nord |
| | Temperature | +05 °C | +04 °C | +04 °C |
| | Temp.percepita | 3 °C | 2 °C | 2 °C |
| 2000 | Venti | 06 nodi da N-Ovest | 11 nodi da N-Ovest | 08 nodi da N-Ovest |
| | Temperature | +08 °C | +08 °C | +07 °C |
| | Temp.percepita | 6 °C | 5 °C | 4 °C |
| 3000 | Venti | 06 nodi da N-Ovest | 07 nodi da N-Ovest | 09 nodi da N-Ovest |
| | Temperature | +00 °C | +01 °C | +03 °C |
| | Temp.percepita | -4 °C | -3 °C | -1 °C |
| Zero termico | | 2900-3100 m. | 3000-3200 m. | 3200-3400 m. |
| Fenomeno | | — | — | — |
| Stato del cielo | | | | |

## LEGENDA FENOMENI

— Assenza Fenomeni · Nebbia · Foschia · Pioggia debole · Pioggia moderata · Pioggia forte · Temporali

Nevicata debole · Nevicata moderata · Nevicata forte

## STATO DEL CIELO

Sereno · Poco nuvoloso · Nuvoloso · Molto nuvoloso · Coperto

## Parametri meteonivometrici registrati presso i campi di rilevamento il 05/04/2026.

| Località | Comune | Quota (m.s.l.m.) | Altezza neve (cm) | Neve caduta nelle 24 ore (cm) | Temp. Min (°C) | Temp. Max (°C) | Condizioni del tempo |
|---|---|---|---|---|---|---|---|
| COLLE RUTO | Campotosto (AQ) | 1384 | 45 | 0 | -1 | +10 | Assenza di precipitazioni |
| S. DONATO | Castel del Monte (AQ) | 1400 | 23 | 0 | -1 | +13 | Assenza di precipitazioni |
| CAMPO IMPERATORE | L'Aquila (AQ) | 2135 | 212 | 0 | N.P. | N.P. | Assenza di precipitazioni |

**(*) Rilievi fuori campo**

**L'INFORMAZIONE E' PREVENZIONE - LEGGI L'ATTUALE GRADO DI PERICOLO VALANGHE!**

**IL CAPO DEL CENTRO NAZIONALE METEOMONT**
**(Ten. Col. RFI Emanuela Gini)**
**FIRMA AUTOGRAFA OMESSA AI SENSI**
**DELL'ART.3 DEL D.LGS N.39/1993**

**Bollettino realizzato su scala sinottica-regionale (standard EAWS). La sua valutazione non può escludere in alcun modo la necessità di una seria e capace valutazione locale del pericolo (singolo pendio) che può essere anche sensibilmente diverso. Le previsioni meteorologiche sono relative all'orario UTC (per l'Italia +1 in inverno e +2 in estate).**