# Bulletin d'estimation du risque d'avalanche
## (valable en dehors des pistes balisées et ouvertes)

# MASSIF : Aravis

Rédigé le lundi 6 avril 2026 à 16h

## Estimation des risques pour le : MARDI 07 AVRIL

**POURSUITE DE L'HUMIDIFICATION AU SOLEIL, ELLE GAGNE EN ALTITUDE ET EN PROFONDEUR.**

2

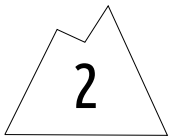


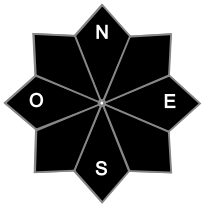


Indice de risque limité.

**Départs spontanés :** Coulées humides au soleil, avalanches de fond.

**Déclenchements provoqués :** Coulées de neige sous les skis.

Indices de risque : 5 très fort - 4 fort - 3 marqué - 2 limité - 1 faible -- En noir : les pentes les plus dangereuses

## Stabilité du manteau neigeux

**Situation avalancheuse typique :** neige humide avalanches de fond

Départs spontanés :
* Coulées de neige humide, dans les versants ensoleillés, elles suivent l'ensoleillement en journée. Elles sont toutes altitudes et toutes orientations. Elles peuvent être plus épaisses sur un très large secteur O/NO, le bon regel de la nuit limitant le réchauffement dans les premiers versants voyant le soleil donc NE/E. Généralement de taille 1, parfois 2 (petite à moyenne). Facteur aggravant : la présence d'une couche fragile persistante localement peut engendrer un départ en plaque, d'apparence humide en surface. De la même manière une première coulée peut déclencher en cascade une seconde plaque avec une cassure linéaire et/ou jusqu'au terrain. Taille 2, plus rarement une taille 3 (grande).
* À toute heure du jour et de la nuit, des fissures de reptations peuvent s'ouvrir et des avalanches de fond sont possibles sur les terrains lisses (pentes herbeuses, dalles rocheuses, etc). Taille 1 à 2.

Déclenchements provoqués :
* Coulées de neige humide sous les skis. Taille 1, 2.

Autre :
* Le redoux peut occasionner des chutes de corniches.

## Qualité de la neige

Enneigement :
Bon pour un début avril. On peut chausser skis ou raquettes dès 1200/1300 m en versants N, et 1400/1600 m en versants S.

Qualité de la neige ce mardi :
* Très bon regel.
* Les pentes chauffent au fil de l'ensoleillement.
* En nord, humidification en surface sous 2500 m voir plus haut sous les quelques nuages. Encore des accumulations de neige importantes, ou au contraire, des zones dures voire ravagées par le vent. Les crêtes et sommets sont les plus ravagées par le vent.
* Nombreuses corniches et accumulations/congères.

## Aperçu météo pour le mardi 07 avril

| nuit | matin | après-midi | soir |
|---|---|---|---|

Nuit clair et très belle journée. Températures très douces, 11°C à 2000 m.

| Pluie-Neige | | | | |
|---|---|---|---|---|
| Iso 0 °C | 3 200 m | 3 300 m | 3 300 m | 3 400 m |
| Vent 2000 m | ↑ 10 km/h | ↖ 5 km/h | ↙ 5 km/h | ↙ 5 km/h |
| Vent 2500 m | → 10 km/h | ↗ 5 km/h | ↙ 10 km/h | ↙ 15 km/h |

## Épaisseur de neige hors-piste

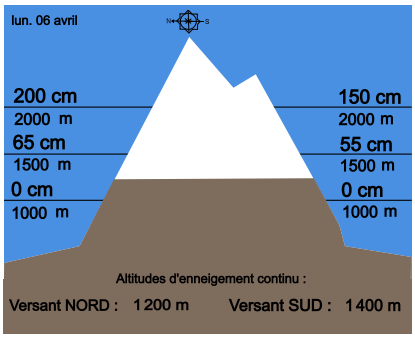


## Précipitations à 1800 m

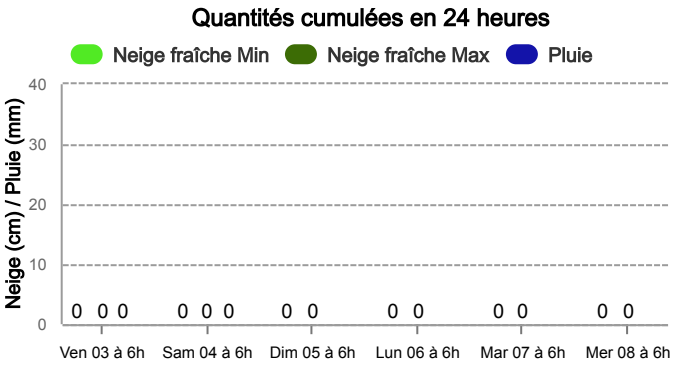


## Tendance du mercredi 08 avril

2

**Indice de risque limité**

Belle journée ensoleillée, très douce avec un isotherme 0°C qui oscille vers 3500 m. Activité en neige humide encore bien présente.

Pour consulter la vigilance en cours, veuillez vous rendre sur le site https://vigilance.meteofrance.fr/fr

Météo-France - 73 avenue de Paris, 94165 Saint-Mandé cedex - Contact : contact@meteo.fr

Rédigé par Météo-France avec la contribution des observateurs du réseau nivo-météorologiques. Partenariat : ANMSM (Maires de Stations de Montagne), DSF (Domaines Skiables de France), ADSP (Directeurs de Pistes et de la Sécurité des Stations de Sports d'Hiver) et autres acteurs de la montagne.

Bulletin neige & avalanches par téléphone au 0 892 68 10 20 Service 0,35 € / min + prix appel

RÉPUBLIQUE FRANÇAISE
*Liberté Égalité Fraternité*

METEO FRANCE
À VOS CÔTÉS, DANS UN CLIMAT QUI CHANGE

# Bulletin d'estimation du risque d'avalanche

## (valable en dehors des pistes balisées et ouvertes)

# MASSIF : Aravis

Rédigé le lundi 6 avril 2026 à 16h

## Conditions nivo-météo des 7 derniers jours

| | mar. 31/03 | | | | mer. 01/04 | | | | jeu. 02/04 | | | | ven. 03/04 | | | | sam. 04/04 | | | | dim. 05/04 | | | | lun. 06/04 | | | |
|---|---|---|---|---|---|---|---|---|---|---|---|---|---|---|---|---|---|---|---|---|---|---|---|---|---|---|---|---|
| | 03h | 09h | 15h | 21h | 03h | 09h | 15h | 21h | 03h | 09h | 15h | 21h | 03h | 09h | 15h | 21h | 03h | 09h | 15h | 21h | 03h | 09h | 15h | 21h | 03h | 09h | 15h | 21h |
| Météo | | | | | | | | | | | | | | | | | | | | | | | | | | | | |
| Vent (km/h) | 65 | 65 | 60 | 60 | 70 | 70 | 50 | 40 | 30 | 40 | 40 | 50 | 50 | 30 | 20 | 15 | 25 | 20 | 10 | 15 | 15 | 30 | 50 | 40 | 40 | 30 | 30 | 20 |
| à 2500m | | | | | | | | | | | | | | | | | | | | | | | | | | | | |
| Vent (km/h) | 45 | 40 | 45 | 40 | 40 | 35 | 35 | 20 | 20 | 20 | 30 | 30 | 20 | 20 | 15 | 5 | 15 | 15 | 5 | 10 | 10 | 20 | 30 | 25 | 20 | 20 | 15 | 10 |
| à 2000m | | | | | | | | | | | | | | | | | | | | | | | | | | | | |

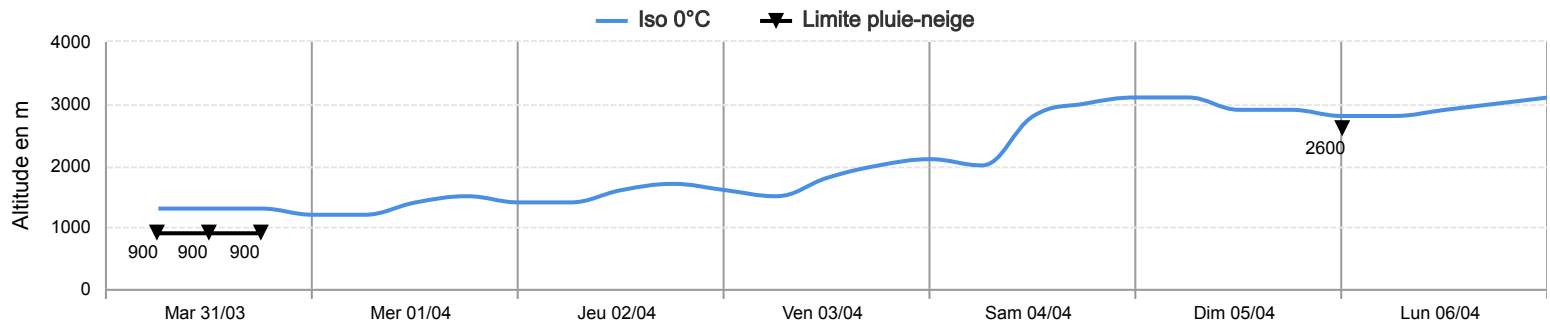


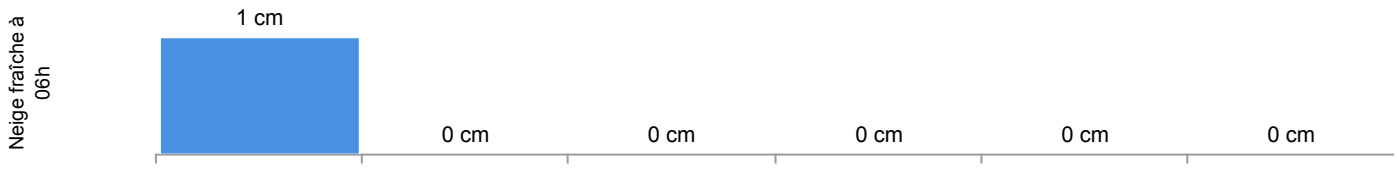


| Risque d'avalanche | mar. 31/03 | mer. 01/04 | jeu. 02/04 | ven. 03/04 | sam. 04/04 | dim. 05/04 | lun. 06/04 |
|---|---|---|---|---|---|---|---|
| | 3 | 3 | 2 | 2 | 2 | 2 | 2 |

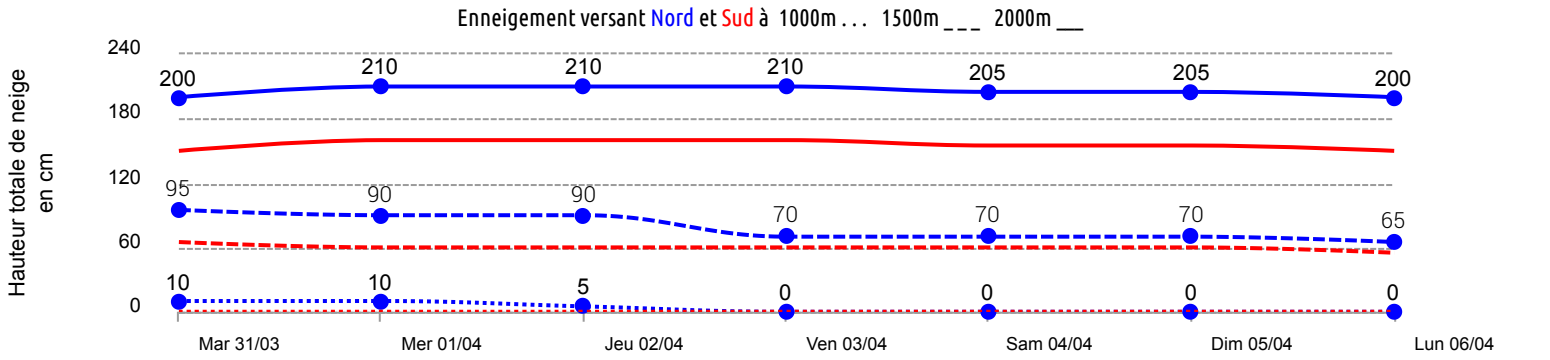


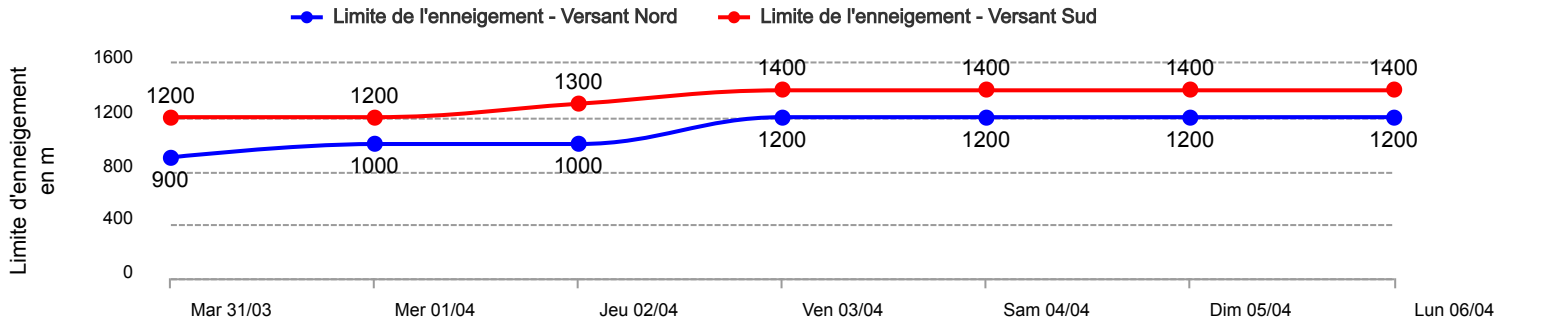


Pour consulter la vigilance en cours, veuillez vous rendre sur le site https://vigilance.meteofrance.fr/fr


**Météo-France - 73 avenue de Paris, 94165 Saint-Mandé cedex - Contact : contact@meteo.fr**



Rédigé par Météo-France avec la contribution des observateurs du réseau nivo-météorologiques. Partenariat : ANMSM (Maires de Stations de Montagne), DSF (Domaines Skiables de France), ADSP (Directeurs de Pistes et de la Sécurité des Stations de Sports d'Hiver) et autres acteurs de la montagne.



Bulletin neige & avalanches par téléphone au
0 892 68 10 20 Service 0,35 € / min + prix appel