Bulletin d'estimation du risque d'avalanche
(valable en dehors des pistes balisées et ouvertes)

MASSIF : Belledonne

Rédigé le lundi 6 avril 2026 à 16h

Estimation des risques pour le : MARDI 07 AVRIL

POURSUITE DE L'HUMIDIFICATION AU SOLEIL, GAGNANT EN ALTITUDE ET EN PROFONDEUR. RARES DÉPARTS VOLUMINEUX POSSIBLES.

2

1 → 2

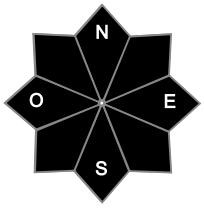

humidification

Indice de risque faible évoluant en limité.

Départs spontanés : Avalanches humides de taille 1 à 2 en pentes réchauffées par le soleil / près des rochers. Rares grandes avalanches de taille 3 non exclues, départ linéaire et/ou au terrain possible.

Déclenchements provoqués : En pente bien humide, coulée ponctuelle sous les skis. Rare plaque en versant Nord d'altitude.

Indices de risque : 5 très fort - 4 fort - 3 marqué - 2 limité - 1 faible -- En noir : les pentes les plus dangereuses

Stabilité du manteau neigeux

Situation avalancheuse typique : neige humide — avalanches de fond

Départs spontanés : - Après un regel nocturne meilleur que la veille (ciel plus dégagé et peu de vent), de nouvelles avalanches humides peuvent se produire ce mardi dans les pentes réchauffées par le soleil, le plus souvent de taille 1 à 2. L'humidification gagne petit à petit en profondeur, et on ne peut exclure qu'elle atteigne localement des couches fragiles enfouies dans le manteau, notamment dans les accumulations des versants Est et Ouest, auquel cas une avalanche plus conséquente de taille 3 est envisageable, avec départ linéaire et/ou jusqu'au terrain.
- Une rupture spontanée de corniche n'est pas exclue.

Déclenchements provoqués : - En pentes soutenues et bien humidifiées (suivant la course du soleil), le pratiquant peut faire couler la neige humide sous les skis.
- Très localement en faces Nord d'altitude au-dessus de 2500 m environ, de rares plaques de surface, souvent dures, peuvent subsister dans les zones d'accumulations où la neige récente a été travaillée voire soufflée par la bise de Nord-Est. Elles sont désormais difficiles à déclencher.

Autres : A l'ombre neige parfois durcie par regel, anciennes traces lustrées. En pentes où le soleil est plus rasant des secteurs temporairement croutés et ski délicat....

Qualité de la neige

Qualification de l'enneigement : L'enneigement est très bon dès la moyenne montagne peu ensoleillée, et dans les combes d'altitude (ce qui est plus classique)... La fonte a bien débuté aux plus basses altitudes enneigées et dans les versants bien ensoleillés, elle se poursuit et s'accentue encore ce lundi.
Limites skiables : Vers 1200/1300m en plein Nord (hors sapins), 1500/1900m au soleil...

Qualité de la neige mardi : En large Sud neige plus transformée, printanière. Regel nocturne meilleur que la veille, puis rapide humidification suivant la course du soleil. Neige encore sèche en plein Nord au dessus de 2400/2600m environ, avec une neige poudreuse dense en couloirs abrités ou bien souvent cartonnée/sculptée, durcie par la bise du début de semaine. En versants intermédiaires neige temporairement croutée/cassante.

Aperçu météo pour le mardi 07 avril

Temps très doux et ensoleillé. Peu de vent, régime de brises.

	nuit	matin	après-midi	soir
Pluie-Neige				
Iso 0 °C	3 200 m	3 300 m	3 300 m	3 400 m
Vent 2000 m	← 10 km/h	↖ 5 km/h	→ 10 km/h	↖ 10 km/h
Vent 3000 m	↘ 15 km/h	↗ 5 km/h	↙ 10 km/h	↙ 15 km/h

Épaisseur de neige hors-piste

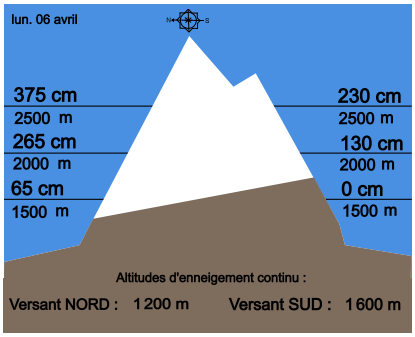

Précipitations à 1800 m

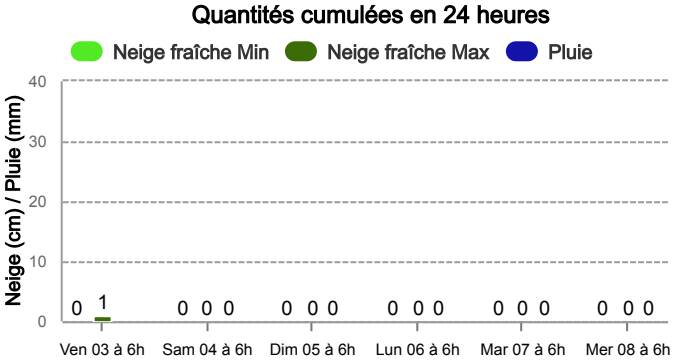

Tendance du mercredi 08 avril

2

Indice de risque limité

Mercredi, maintien du temps très doux et ensoleillé. Isotherme 0°C vers 3500 m. L'humidification se poursuit, gagnant en profondeur et pouvant occasionner de nouvelles avalanches humides au soleil, localement volumineuses.

Pour consulter la vigilance en cours, veuillez vous rendre sur le site https://vigilance.meteofrance.fr/fr

Météo-France - 73 avenue de Paris, 94165 Saint-Mandé cedex - Contact : contact@meteo.fr

Rédigé par Météo-France avec la contribution des observateurs du réseau nivo-météorologiques. Partenariat : ANMSM (Maires de Stations de Montagne), DSF (Domaines Skiables de France), ADSP (Directeurs de Pistes et de la Sécurité des Stations de Sports d'Hiver) et autres acteurs de la montagne.

Bulletin neige & avalanches par téléphone au 0 892 68 10 20 Service 0,35 € / min + prix appel

RÉPUBLIQUE FRANÇAISE
Liberté Égalité Fraternité

METEO FRANCE
À VOS CÔTÉS, DANS UN CLIMAT QUI CHANGE

Bulletin d'estimation du risque d'avalanche
(valable en dehors des pistes balisées et ouvertes)
MASSIF : Belledonne

Rédigé le lundi 6 avril 2026 à 16h

Conditions nivo-météo des 7 derniers jours

	mar. 31/03				mer. 01/04				jeu. 02/04				ven. 03/04				sam. 04/04				dim. 05/04				lun. 06/04			
	03h	09h	15h	21h	03h	09h	15h	21h	03h	09h	15h	21h	03h	09h	15h	21h	03h	09h	15h	21h	03h	09h	15h	21h	03h	09h	15h	21h
Météo																												
Vent (km/h)	90	100	100	70	65	55	25	30	35	55	55	55	50	45	40	30	35	25	10	5	15	20	30	25	25	20	15	10
à 3000m																												
Vent (km/h)	60	60	60	35	25	15	30	10	15	25	30	20	25	30	15	15	15	15	10	10	10	10	25	15	15	10	10	5
à 2000m																												

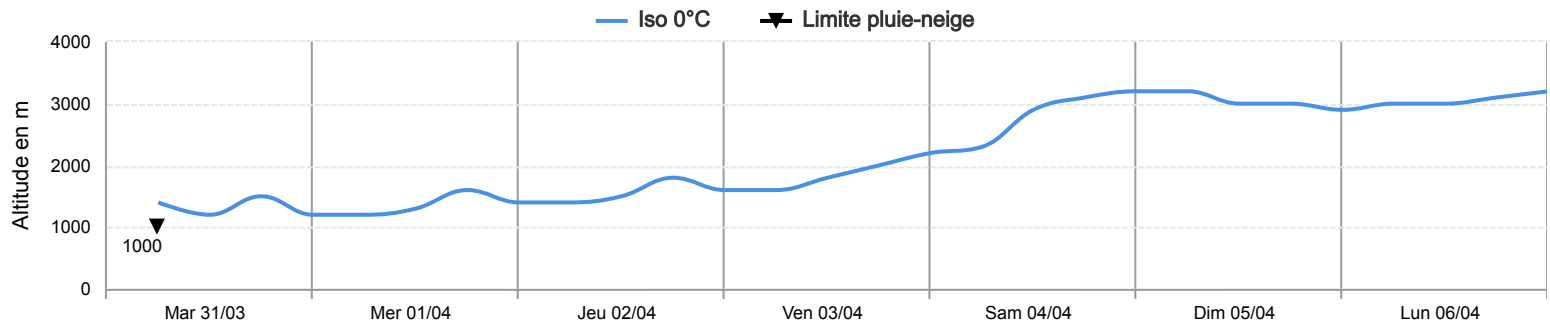

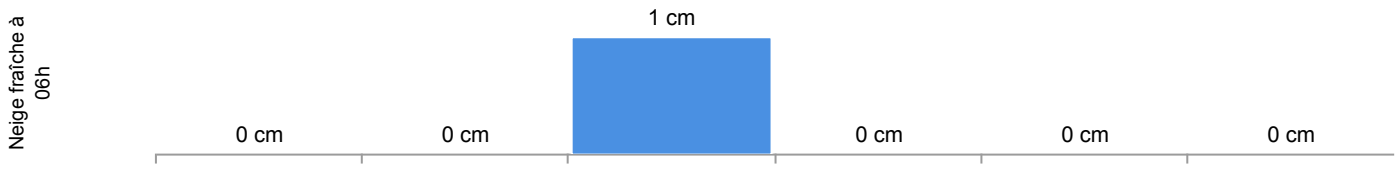

Risque d'avalanche	mar. 31/03	mer. 01/04	jeu. 02/04	ven. 03/04	sam. 04/04	dim. 05/04	lun. 06/04
	3	3	2	2	2	2	2

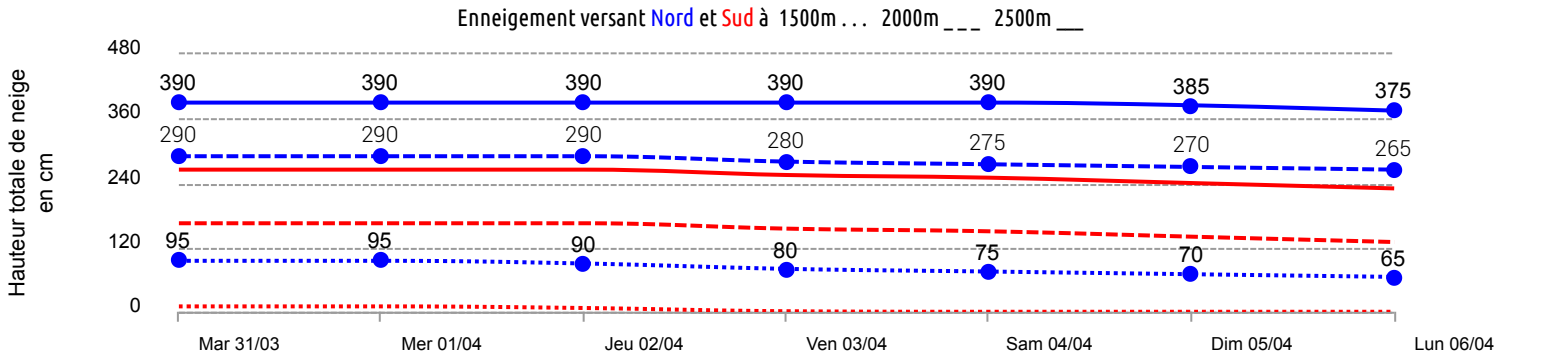

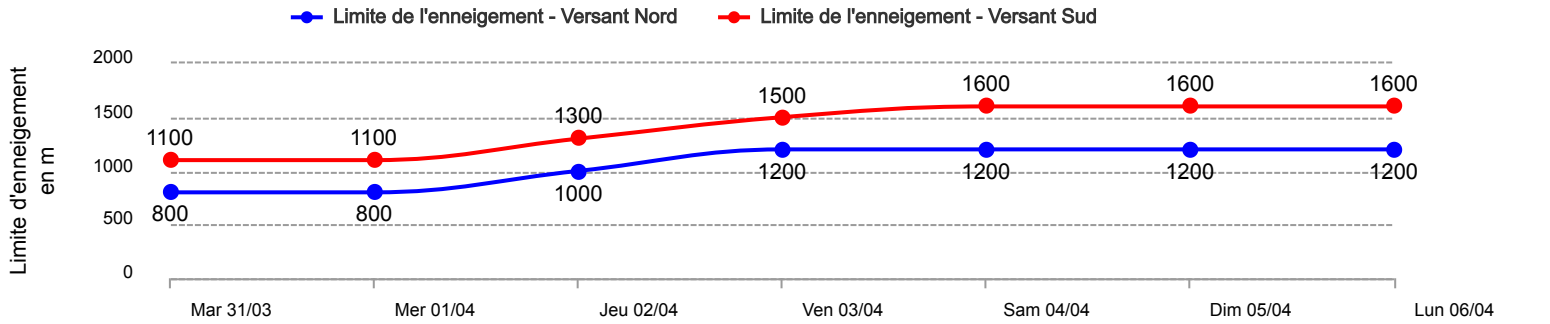

Pour consulter la vigilance en cours, veuillez vous rendre sur le site https://vigilance.meteofrance.fr/fr

Météo-France - 73 avenue de Paris, 94165 Saint-Mandé cedex - Contact : contact@meteo.fr

Rédigé par Météo-France avec la contribution des observateurs du réseau nivo-météorologiques. Partenariat : ANMSM (Maires de Stations de Montagne), DSF (Domaines Skiables de France), ADSP (Directeurs de Pistes et de la Sécurité des Stations de Sports d'Hiver) et autres acteurs de la montagne.

Bulletin neige & avalanches par téléphone au
0 892 68 10 20 Service 0,35 € / min + prix appel