Bulletin d'estimation du risque d'avalanche

(valable en dehors des pistes balisées et ouvertes)

MASSIF : Haut-Var Haut-Verdon

Rédigé le lundi 6 avril 2026 à 16h

Estimation des risques pour le : MARDI 07 AVRIL

QUELQUES DÉPARTS EN NEIGE HUMIDE, RAREMENT GRAND

2

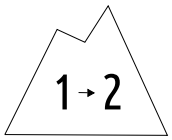

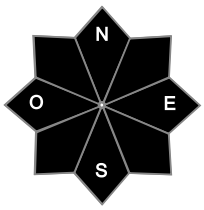

Indice de risque faible évoluant en limité.

Départs spontanés : quelques départs en neige humide, rarement grand

Déclenchements provoqués : départs sous les skis en neige humide, notamment en altitude.

Indices de risque : 5 très fort - 4 fort - 3 marqué - 2 limité - 1 faible -- En noir : les pentes les plus dangereuses

Stabilité du manteau neigeux

Situation avalancheuse typique : neige humide

Départs spontanés : peu probables au lever du jour avec le regel nocturne, puis activité en neige humide au fil de la journée en suivant la course du soleil. Départs ponctuels engendrant des avalanches de taille petite à moyenne (taille 1 à 2). Un départ linéaire est possible, notamment dans les orientations est et ouest, en cas d'humidification d'une couche fragile enfouie à la base du manteau neigeux. Avalanches de taille moyenne (taille 2) à plus rarement grande (taille 3).

Déclenchements provoqués : un skieur évoluant tardivement dans une pente humidifiée peut provoquer un départ ponctuel de neige humide, voire un départ linéaire en sollicitant une couche fragile plus profondément enfouie notamment dans les versants nord-ouest et nord-est. Avalanches généralement de taille petite (taille 1), voire moyenne (taille 2) en cas de départ linéaire.

Qualité de la neige

Enneigement plutôt excédentaire pour un début avril.
Hauteurs de neige observées : vers 2000 m, 161 cm dans le vallon de Valdemars, 98 cm à la Sanguinière dans le Haut Var.

Enneigement skiable : vers 1500/1600 m en terrain favorable en ubacs, 1800/1900 m en adrets peu pentus.

État de la neige en surface : manteau neigeux printanier avec un bon regel nocturne le matin, s'humidifiant rapidement en journée. On trouve localement un peu de neige plus froide et meuble en ubacs bien abrités du vent au-dessus de 2400/2600 m. Neige fortement travaillée par le vent en altitude.

Aperçu météo pour le mardi 07 avril

	nuit	matin	après-midi	soir
Temps sec, ensoleillé et très doux.				
Pluie-Neige				
Iso 0 °C	3 200 m	3 200 m	3 200 m	3 400 m
Vent 2000 m	↙ 10 km/h	→ 10 km/h	↘ 15 km/h	↓ 10 km/h
Vent 3000 m	↘ 20 km/h	→ 15 km/h	→ 15 km/h	↓ 15 km/h

Épaisseur de neige hors-piste

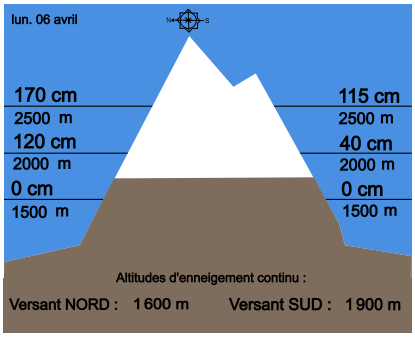

Précipitations à 1800 m

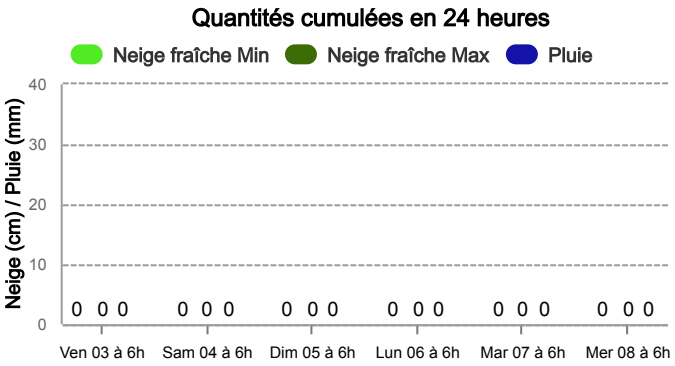

Tendance du mercredi 08 avril

2

Indice de risque limité

Maintien d'un risque limité. L'humidification du manteau neigeux se poursuit et pourrait permettre la sollicitation de couche fragile enfouie dans les orientations nord-ouest et nord-est.

Pour consulter la vigilance en cours, veuillez vous rendre sur le site https://vigilance.meteofrance.fr/fr

Météo-France - 73 avenue de Paris, 94165 Saint-Mandé cedex - Contact : contact@meteo.fr

Rédigé par Météo-France avec la contribution des observateurs du réseau nivo-météorologiques. Partenariat : ANMSM (Maires de Stations de Montagne), DSF (Domaines Skiables de France), ADSP (Directeurs de Pistes et de la Sécurité des Stations de Sports d'Hiver) et autres acteurs de la montagne.

Bulletin neige & avalanches par téléphone au

0 892 68 10 20 Service 0,35 € / min + prix appel

RÉPUBLIQUE FRANÇAISE
Liberté Égalité Fraternité

METEO FRANCE
À VOS CÔTÉS, DANS UN CLIMAT QUI CHANGE

Bulletin d'estimation du risque d'avalanche

(valable en dehors des pistes balisées et ouvertes)

MASSIF : Haut-Var Haut-Verdon

Rédigé le lundi 6 avril 2026 à 16h

Conditions nivo-météo des 7 derniers jours

	mar. 31/03				mer. 01/04				jeu. 02/04				ven. 03/04				sam. 04/04				dim. 05/04				lun. 06/04			
	03h	09h	15h	21h	03h	09h	15h	21h	03h	09h	15h	21h	03h	09h	15h	21h	03h	09h	15h	21h	03h	09h	15h	21h	03h	09h	15h	21h
Météo																												
Vent (km/h)	80	40	40	75	80	60	50	45	50	25	25	20	15	25	25	25	15	10	15	10	10	15	25	30	30	25	20	20
à 3000m																												
Vent (km/h)	45	30	35	65	70	45	40	35	35	20	20	20	15	15	15	10	10	5	15	5	5	10	15	15	15	15	20	10
à 2000m																												

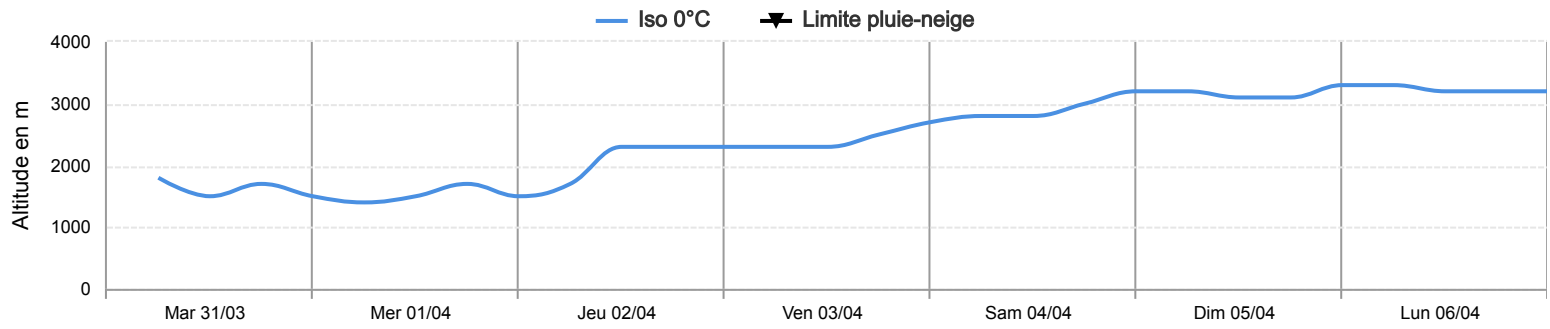

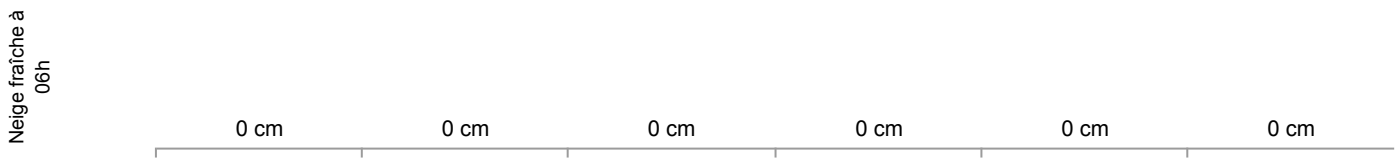

Risque d'avalanche	mar. 31/03	mer. 01/04	jeu. 02/04	ven. 03/04	sam. 04/04	dim. 05/04	lun. 06/04
	2	2	1	1	2	2	2

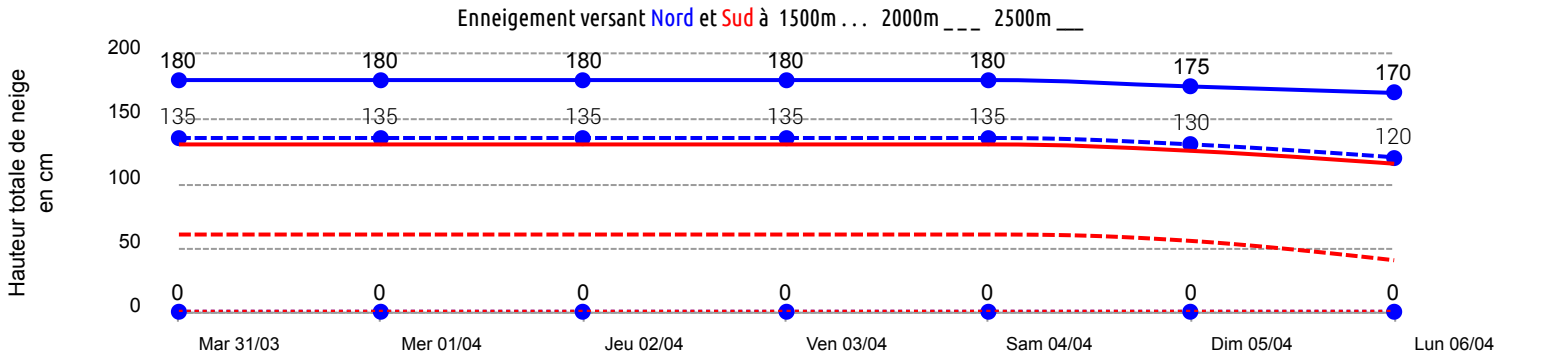

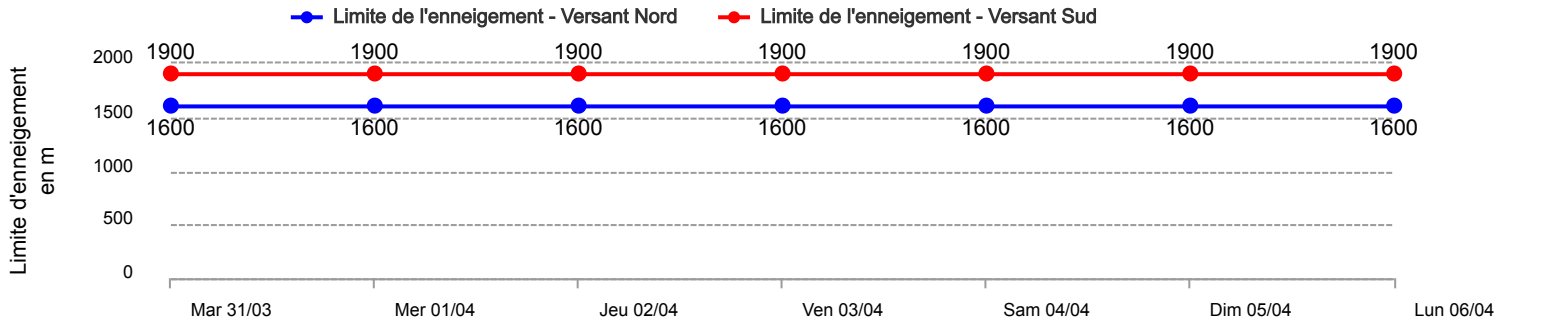

Pour consulter la vigilance en cours, veuillez vous rendre sur le site https://vigilance.meteofrance.fr/fr

Météo-France - 73 avenue de Paris, 94165 Saint-Mandé cedex - Contact : contact@meteo.fr

Rédigé par Météo-France avec la contribution des observateurs du réseau nivo-météorologiques. Partenariat : ANMSM (Maires de Stations de Montagne), DSF (Domaines Skiables de France), ADSP (Directeurs de Pistes et de la Sécurité des Stations de Sports d'Hiver) et autres acteurs de la montagne.

Bulletin neige & avalanches par téléphone au

0 892 68 10 20 Service 0,35 € / min + prix appel