Bulletin d'estimation du risque d'avalanche

(valable en dehors des pistes balisées et ouvertes)

MASSIF : Oisans

Rédigé le lundi 6 avril 2026 à 16h

Estimation des risques pour le : MARDI 07 AVRIL

POURSUITE DE L'HUMIDIFICATION AU SOLEIL, GAGNANT EN ALTITUDE ET EN PROFONDEUR. RARES DÉPARTS VOLUMINEUX POSSIBLES.

2

1 → 2

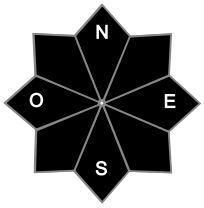

humidification

Indice de risque faible évoluant en limité.

Départs spontanés : Avalanches humides de taille 1 à 2 en pentes réchauffées par le soleil / près des rochers. Rares grandes avalanches de taille 3 non exclues, départ linéaire et/ou au terrain possible.

Déclenchements provoqués : En pente bien humide, coulée ponctuelle sous les skis. Rare plaque en versant Nord d'altitude.

Indices de risque : 5 très fort - 4 fort - 3 marqué - 2 limité - 1 faible -- En noir : les pentes les plus dangereuses

Stabilité du manteau neigeux

Situation avalancheuse typique : neige humide — avalanches de fond

Départs spontanés : - Après un regel nocturne assez bon en général (ciel dégagé et très peu de vent), de nouvelles avalanches humides peuvent se produire ce mardi dans les pentes réchauffées par le soleil, le plus souvent de taille 1 à 2. L'humidification gagne petit à petit en profondeur, et on ne peut exclure qu'elle atteigne localement des couches fragiles enfouies dans le manteau, notamment dans les accumulations des versants Est et Ouest, auquel cas une avalanche plus conséquente de taille 3 est envisageable, avec départ linéaire et/ou jusqu'au terrain.
- Une rupture spontanée de corniche n'est pas exclue.

Déclenchements provoqués : - En pentes soutenues et bien humidifiées (suivant la course du soleil), le pratiquant peut faire couler la neige humide sous les skis.
- Très localement en faces Nord d'altitude au-dessus de 2500 m d'altitude, de rares plaques de surface, souvent dures, peuvent subsister dans les zones d'accumulations où la neige récente a été travaillée voire soufflée par la bise de Nord-Est. Elles sont désormais difficiles à déclencher.

Autres : A l'ombre neige parfois durcie par regel, anciennes traces lustrées. En pentes où le soleil est plus rasant des secteurs temporairement croutés et ski délicat....

Qualité de la neige

Qualification de l'enneigement : L'enneigement est bon dès la moyenne montagne "froide", les fonds de vallées et même très bon dans les combes d'altitude (ce qui est plus classique à cette saison). Hauts sommets, glaciers et faces raides d'altitudes sont plus secs... La fonte a bien débuté aux plus basses altitudes enneigées et dans les versants bien ensoleillés, elle se poursuit et s'accentue encore ce lundi.
Limites skiables : Vers 1300/1500m en Nord, 1600/2200m au soleil suivant l'exposition/ la raideur de la pente...

Qualité de la neige mardi : En large Sud neige plus transformée, printanière. Assez bon regel nocturne, puis rapide humidification suivant la course du soleil. Neige encore sèche en plein Nord au dessus de 2400/2600m environ, avec une neige poudreuse dense en couloirs abrités ou bien souvent cartonnée/sculptée, durcie par la bise du début de semaine. En versants intermédiaires neige temporairement croutée/cassante.

Aperçu météo pour le mardi 07 avril

	nuit	matin	après-midi	soir
Temps très doux et ensoleillé. Peu de vent, régime de brises.				
Pluie-Neige				
Iso 0 °C	3 200 m	3 300 m	3 300 m	3 400 m
Vent 2500 m	5 km/h	5 km/h	5 km/h	5 km/h
Vent 3500 m	10 km/h	5 km/h	5 km/h	10 km/h

Épaisseur de neige hors-piste

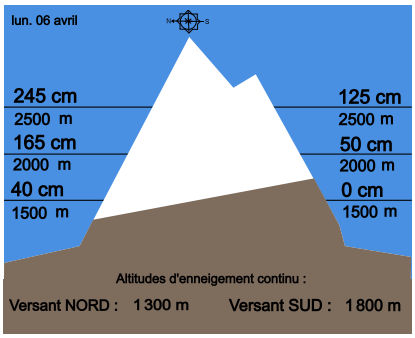

Précipitations à 1800 m

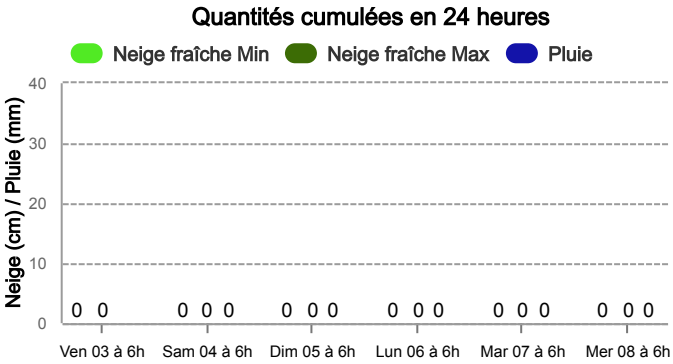

Tendance du mercredi 08 avril

2

Indice de risque limité

Mercredi, maintien du temps très doux et ensoleillé. Isotherme 0°C vers 3500 m. L'humidification se poursuit, gagnant en profondeur et pouvant occasionner de nouvelles avalanches humides au soleil, localement volumineuses.

Pour consulter la vigilance en cours, veuillez vous rendre sur le site https://vigilance.meteofrance.fr/fr

Météo-France - 73 avenue de Paris, 94165 Saint-Mandé cedex - Contact : contact@meteo.fr

Rédigé par Météo-France avec la contribution des observateurs du réseau nivo-météorologiques. Partenariat : ANMSM (Maires de Stations de Montagne), DSF (Domaines Skiables de France), ADSP (Directeurs de Pistes et de la Sécurité des Stations de Sports d'Hiver) et autres acteurs de la montagne.

Bulletin neige & avalanches par téléphone au 0 892 68 10 20 Service 0,35 € / min + prix appel

RÉPUBLIQUE FRANÇAISE
Liberté Égalité Fraternité

METEO FRANCE
À VOS CÔTÉS, DANS UN CLIMAT QUI CHANGE

Bulletin d'estimation du risque d'avalanche

(valable en dehors des pistes balisées et ouvertes)

MASSIF : Oisans

Rédigé le lundi 6 avril 2026 à 16h

Conditions nivo-météo des 7 derniers jours

	mar. 31/03				mer. 01/04				jeu. 02/04				ven. 03/04				sam. 04/04				dim. 05/04				lun. 06/04			
	03h	09h	15h	21h	03h	09h	15h	21h	03h	09h	15h	21h	03h	09h	15h	21h	03h	09h	15h	21h	03h	09h	15h	21h	03h	09h	15h	21h
Météo																												
Vent (km/h)	120	120	110	80	70	60	25	25	25	35	45	40	40	40	30	30	25	20	10	10	10	20	25	25	25	20	15	10
à 3500m																												
Vent (km/h)	85	90	80	45	40	40	25	0	0	0	5	0	0	5	5	0	15	10	5	5	5	10	20	15	10	10	10	5
à 2500m																												

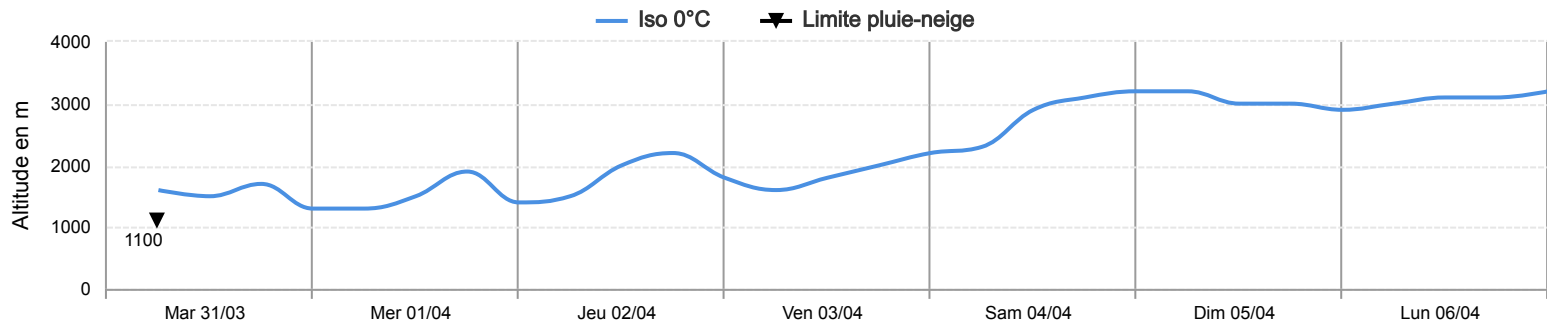

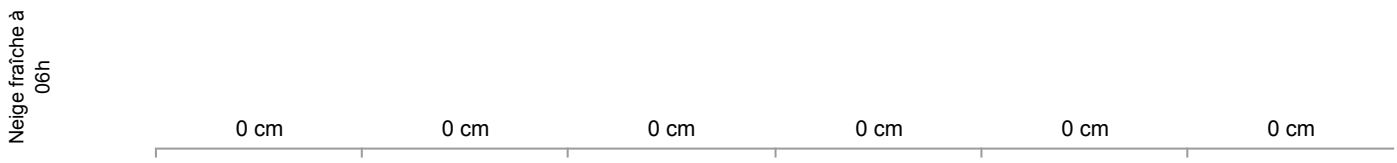

Risque d'avalanche	mar. 31/03	mer. 01/04	jeu. 02/04	ven. 03/04	sam. 04/04	dim. 05/04	lun. 06/04
	2	3	2	2	2	2	2

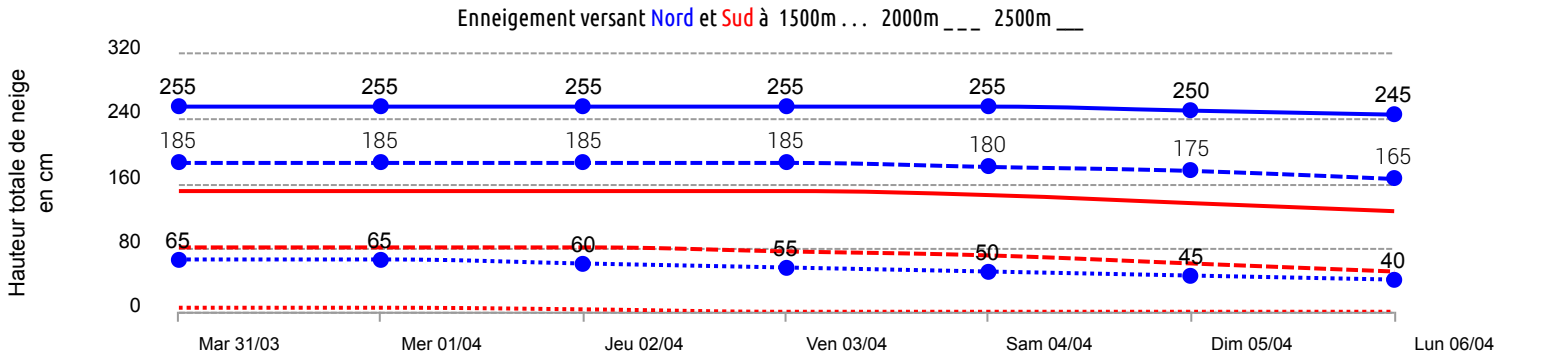

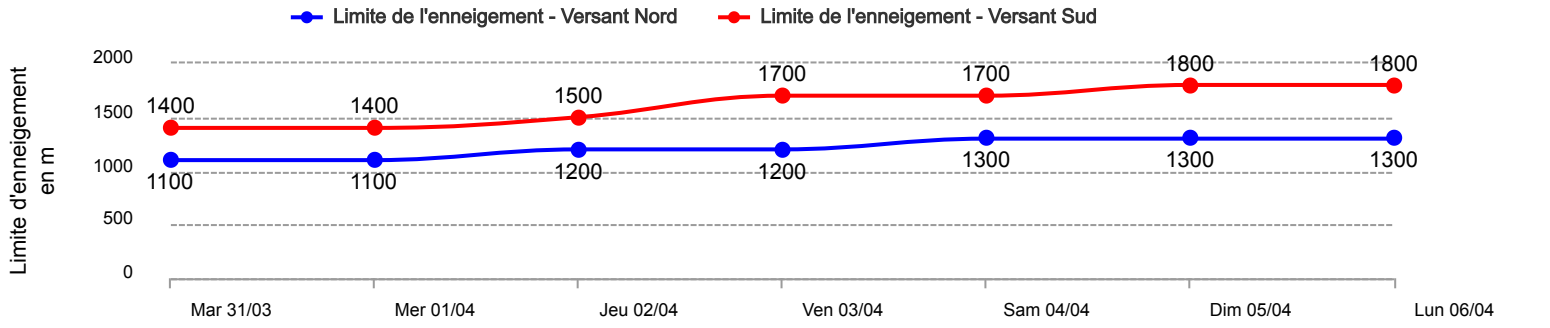

Pour consulter la vigilance en cours, veuillez vous rendre sur le site https://vigilance.meteofrance.fr/fr

Météo-France - 73 avenue de Paris, 94165 Saint-Mandé cedex - Contact : contact@meteo.fr

Rédigé par Météo-France avec la contribution des observateurs du réseau nivo-météorologiques. Partenariat : ANMSM (Maires de Stations de Montagne), DSF (Domaines Skiables de France), ADSP (Directeurs de Pistes et de la Sécurité des Stations de Sports d'Hiver) et autres acteurs de la montagne.

Bulletin neige & avalanches par téléphone au
0 892 68 10 20 Service 0,35 € / min + prix appel