RÉPUBLIQUE FRANÇAISE
Liberté Égalité Fraternité

METEO FRANCE
À VOS CÔTÉS, DANS UN CLIMAT QUI CHANGE

Bulletin d'estimation du risque d'avalanche
(valable en dehors des pistes balisées et ouvertes)

MASSIF : Queyras

Rédigé le lundi 6 avril 2026 à 16h

Estimation des risques pour le : MARDI 07 AVRIL

AVALANCHES DE NEIGE HUMIDE AU SOLEIL, RARES GRANDES POSSIBLES

2

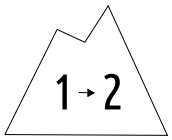

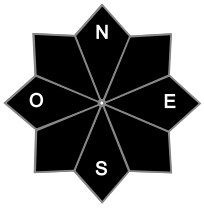

Indice de risque faible évoluant en limité.

Départs spontanés : en neige humide au fil de l'ensoleillement

Déclenchements provoqués : en neige humide sous les skis

Indices de risque : 5 très fort - 4 fort - 3 marqué - 2 limité - 1 faible -- En noir : les pentes les plus dangereuses

Stabilité du manteau neigeux

Situation avalancheuse typique : neige humide neige ventée

Départs spontanés : peu probables en tout début de journée après un bon regel nocturne, puis reprise rapide de l'activité en neige humide au fil de la course du soleil. Départs ponctuels, en particulier en pentes raides près des rochers, engendrant des avalanches petites à moyennes (taille 1 à 2).
Localement, un départ linéaire de grande taille est possible (taille 3), notamment dans les orientations est et ouest, quand l'humidification gagne en profondeur et atteint pour la première fois les couches fragiles persistantes enfouies à la base du manteau neigeux.

Déclenchements provoqués :
Un skieur évoluant tardivement dans une pente raide ensoleillée peut provoquer des départs de neige humide sous les skis, généralement de petite taille.

Qualité de la neige

L'enneigement est proche des normales ou légèrement déficitaire pour un début avril. Hauteurs de neige observées : 143 cm en versant nord du col Izoard à 2300 m, 141 cm au-dessus de St Véran à 2700 m, 89 cm à la Nivôse du Col Agnel à 2630 m

Limite d'enneigement skiable : au plus bas à 1500/1600 m en ubacs bien protégés ou sur pistes forestières, plutôt 2100/2300 m en adrets.

État de la neige de surface : neige en cycle printanier en versants ensoleillés : après un bon regel nocturne, reprise rapide de l'humidification au soleil. Dans les ubacs raides au dessus de 2500/2700 m, neige encore froide, durcie ou travaillée par le vent dans les secteurs exposés, mais encore parfois assez légère dans les combes ou pentes abritées. Sur les crêtes, d'épaisses corniches côtoient des zones pelées par le vent.

Aperçu météo pour le mardi 07 avril

	nuit	matin	après-midi	soir
Poursuite d'un temps calme, bien ensoleillé et très doux.				
Pluie-Neige				
Iso 0 °C	3 200 m	3 300 m	3 400 m	3 400 m
Vent 2000 m	↗ 5 km/h	→ 5 km/h	↗ 20 km/h	↗ 5 km/h
Vent 3000 m	→ 20 km/h	→ 15 km/h	→ 15 km/h	→ 10 km/h

Épaisseur de neige hors-piste

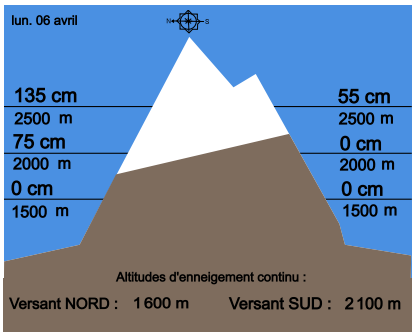

Précipitations à 1800 m

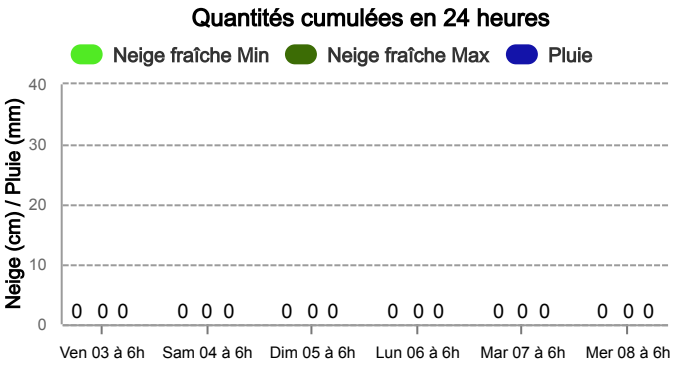

Tendance du mercredi 08 avril

2

Indice de risque limité

Le manteau neigeux printanier continue de s'humidifier de plus en plus profondément. Risque d'avalanches de plus grande taille.

Pour consulter la vigilance en cours, veuillez vous rendre sur le site https://vigilance.meteofrance.fr/fr

Météo-France - 73 avenue de Paris, 94165 Saint-Mandé cedex - Contact : contact@meteo.fr

Rédigé par Météo-France avec la contribution des observateurs du réseau nivo-météorologiques. Partenariat : ANMSM (Maires de Stations de Montagne), DSF (Domaines Skiables de France), ADSP (Directeurs de Pistes et de la Sécurité des Stations de Sports d'Hiver) et autres acteurs de la montagne.

Bulletin neige & avalanches par téléphone au
0 892 68 10 20 Service 0,35 € / min + prix appel

RÉPUBLIQUE FRANÇAISE
Liberté Égalité Fraternité

METEO FRANCE
À VOS CÔTÉS, DANS UN CLIMAT QUI CHANGE

Bulletin d'estimation du risque d'avalanche
(valable en dehors des pistes balisées et ouvertes)

MASSIF : Queyras

Rédigé le lundi 6 avril 2026 à 16h

Conditions nivo-météo des 7 derniers jours

	mar. 31/03				mer. 01/04				jeu. 02/04				ven. 03/04				sam. 04/04				dim. 05/04				lun. 06/04			
	03h	09h	15h	21h	03h	09h	15h	21h	03h	09h	15h	21h	03h	09h	15h	21h	03h	09h	15h	21h	03h	09h	15h	21h	03h	09h	15h	21h
Météo																												
Vent (km/h)	80	70	60	40	40	40	50	50	35	15	15	15	15	20	20	10	15	10	15	10	15	20	30	30	30	20	20	20
à 3000m																												
Vent (km/h)	70	50	35	30	30	30	40	40	20	15	25	15	10	15	20	10	10	10	15	5	5	10	25	10	10	10	20	5
à 2000m																												

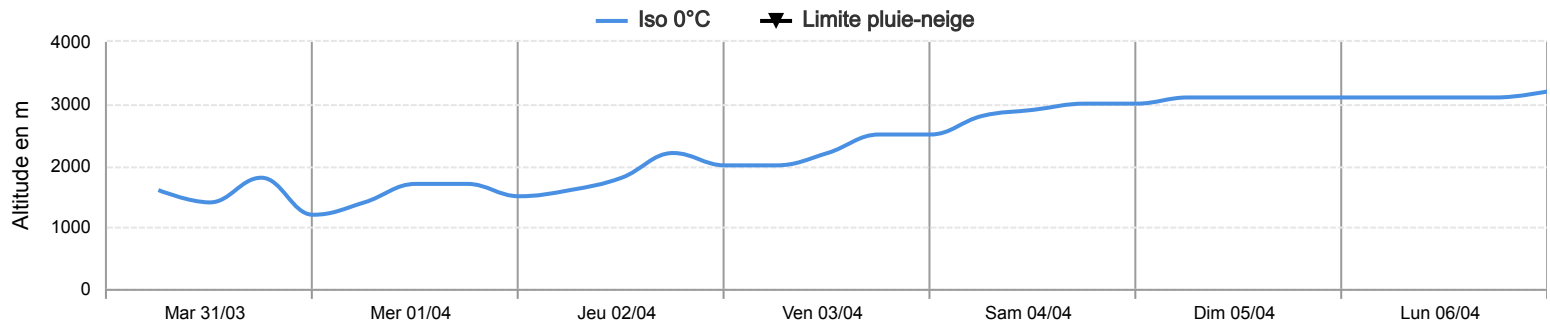

Neige fraîche à 06h	mar. 31/03	mer. 01/04	jeu. 02/04	ven. 03/04	sam. 04/04	dim. 05/04
	0 cm	0 cm	0 cm	0 cm	0 cm	0 cm

Risque d'avalanche	mar. 31/03	mer. 01/04	jeu. 02/04	ven. 03/04	sam. 04/04	dim. 05/04	lun. 06/04
	2	2	2	2	2	2	2

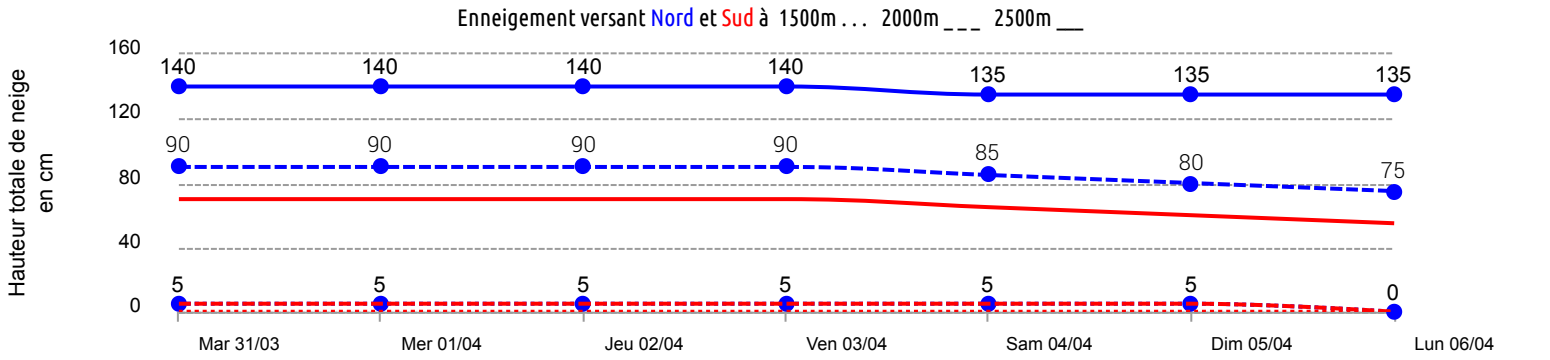

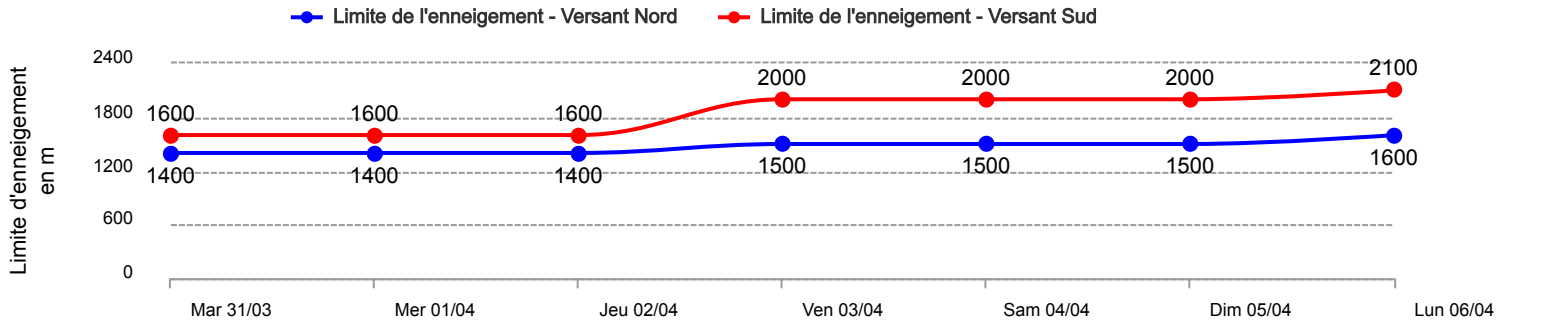

Pour consulter la vigilance en cours, veuillez vous rendre sur le site https://vigilance.meteofrance.fr/fr

Météo-France - 73 avenue de Paris, 94165 Saint-Mandé cedex - Contact : contact@meteo.fr

Rédigé par Météo-France avec la contribution des observateurs du réseau nivo-météorologiques. Partenariat : ANMSM (Maires de Stations de Montagne), DSF (Domaines Skiables de France), ADSP (Directeurs de Pistes et de la Sécurité des Stations de Sports d'Hiver) et autres acteurs de la montagne.

Bulletin neige & avalanches par téléphone au

0 892 68 10 20 Service 0,35 € / min + prix appel