Bulletin d'estimation du risque d'avalanche
(valable en dehors des pistes balisées et ouvertes)

MASSIF : Vercors

Rédigé le lundi 6 avril 2026 à 16h

Estimation des risques pour le : MARDI 07 AVRIL

POURSUITE DE L'HUMIDIFICATION DU MANTEAU NEIGEUX, Y COMPRIS EN FACES "FROIDES"... DÉPART AU TERRAIN PLUS VOLUMINEUX NON EXCLU

2

1 → 2

N O E S

humidification

Indice de risque faible évoluant en limité.

Départs spontanés : Possibles avalanches en pentes raides/humidifiées, y compris en faces "froides" (de taille 1 à 2)... Rare avalanche de glissement de taille 2 à 3 non exclue. Attention aussi aux corniches fragilisées.

Déclenchements provoqués : En pente bien humide, possible coulée ponctuelle sous les skis...

Indices de risque : 5 très fort - 4 fort - 3 marqué - 2 limité - 1 faible -- En noir : les pentes les plus dangereuses

Stabilité du manteau neigeux

Situation avalancheuse typique : neige humide — avalanches de fond

Départs spontanés : - Après un regel nocturne sans doute un peu meilleur que la veille (ciel plus dégagé et peu de vent), de nouvelles avalanches humides peuvent se produire ce mardi, notamment dans les pentes réchauffées par le soleil, le plus souvent de taille 1 à 2. Dans un rare cas, une avalanche de glissement plus conséquente, au terrain, atteignant la taille 2 à 3, ne peut être exclue (alpage raide).
- Une rupture spontanée de corniche ne peut être écartée.

Déclenchements provoqués : En pentes soutenues et bien humidifiées, le pratiquant pourrait faire couler la neige humide sous les skis.

Autres : A l'ombre (le matin surtout) neige parfois durcie ou croutée par regel, si celui-ci est suffisant, avec des surfaces temporairement glissantes...

Qualité de la neige

Qualification de l'enneigement : La fonte s'accélère, mais l'enneigement reste correct dès assez basse altitude, et même très bon vers les hauts du Vercors...
Limites skiables : Vers 1200/1300m en Nord, 1500/1900m au soleil...

Qualité de la neige mardi : Neige printanière, regel nocturne meilleur que la veille, puis rapide humidification en journée, dans tous les versants. En Nord d'altitude toutefois, la neige peut encore être finement croutée/cassante le matin avec des restes de congères/effets du vent...

Aperçu météo pour le mardi 07 avril

	nuit	matin	après-midi	soir
Temps très doux et ensoleillé. Peu de vent, régime de brises.				
Pluie-Neige				
Iso 0 °C	3 200 m	3 300 m	3 300 m	3 400 m
Vent 1500 m	5 km/h	10 km/h	10 km/h	10 km/h
Vent 2000 m	10 km/h	15 km/h	15 km/h	10 km/h

Épaisseur de neige hors-piste

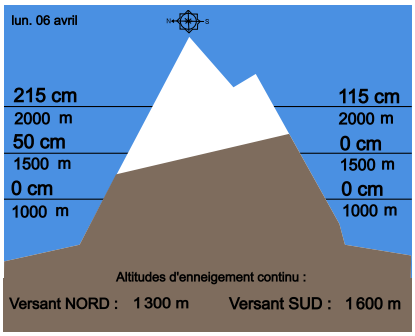

Précipitations à 1800 m

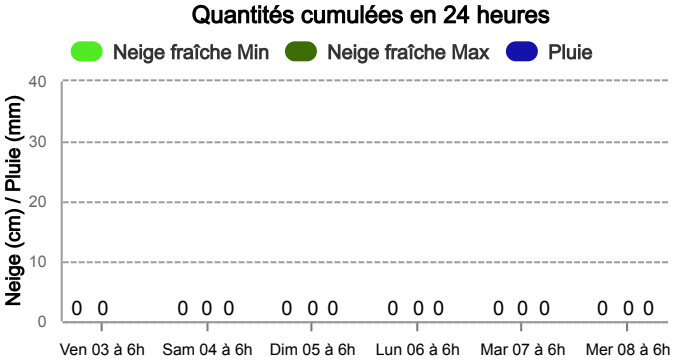

Tendance du mercredi 08 avril

2

Indice de risque limité

Mercredi, maintien du temps très doux et ensoleillé. Isotherme 0°C vers 3500 m. L'humidification se poursuit, gagnant en profondeur et pouvant occasionner de nouvelles avalanches humides, localement volumineuses.

Pour consulter la vigilance en cours, veuillez vous rendre sur le site https://vigilance.meteofrance.fr/fr

Météo-France - 73 avenue de Paris, 94165 Saint-Mandé cedex - Contact : contact@meteo.fr

Rédigé par Météo-France avec la contribution des observateurs du réseau nivo-météorologiques. Partenariat : ANMSM (Maires de Stations de Montagne), DSF (Domaines Skiables de France), ADSP (Directeurs de Pistes et de la Sécurité des Stations de Sports d'Hiver) et autres acteurs de la montagne.

Bulletin neige & avalanches par téléphone au 0 892 68 10 20 Service 0,35 € / min + prix appel

RÉPUBLIQUE FRANÇAISE
Liberté Égalité Fraternité

METEO FRANCE
À VOS CÔTÉS, DANS UN CLIMAT QUI CHANGE

Bulletin d'estimation du risque d'avalanche
(valable en dehors des pistes balisées et ouvertes)

MASSIF : Vercors

Rédigé le lundi 6 avril 2026 à 16h

Conditions nivo-météo des 7 derniers jours

	mar. 31/03				mer. 01/04				jeu. 02/04				ven. 03/04				sam. 04/04				dim. 05/04				lun. 06/04			
	03h	09h	15h	21h	03h	09h	15h	21h	03h	09h	15h	21h	03h	09h	15h	21h	03h	09h	15h	21h	03h	09h	15h	21h	03h	09h	15h	21h
Météo																												
Vent (km/h)	90	90	90	65	60	45	50	30	35	50	55	50	55	45	30	35	40	30	20	10	15	20	30	15	20	20	15	10
à 2000m	↓	↓	↓	↙	↙	↓	↓	↙	↙	↙	↙	↙	↓	↙	↙	↓	↓	↙	↙	↑	↑	↗	↗	↗	↗	→	→	↑
Vent (km/h)	80	70	70	45	45	30	40	25	25	30	40	35	35	35	20	25	35	25	15	10	15	20	25	10	10	10	10	5
à 1500m	↓	↓	↓	↓	↓	↓	↓	↙	↙	↓	↓	↙	↙	↓	↓	↓	↓	↙	↗	↖	↑	↑	↗	↑	↑	↖	→	↖

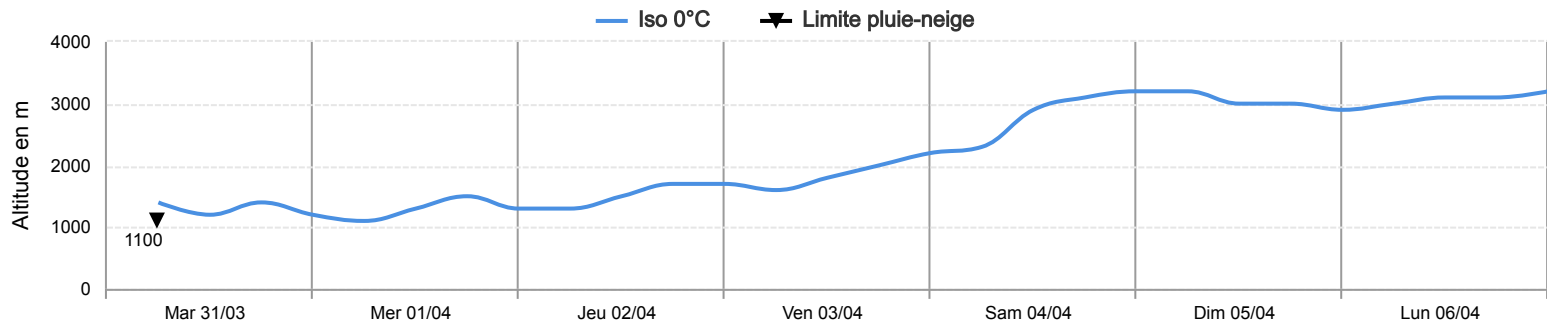

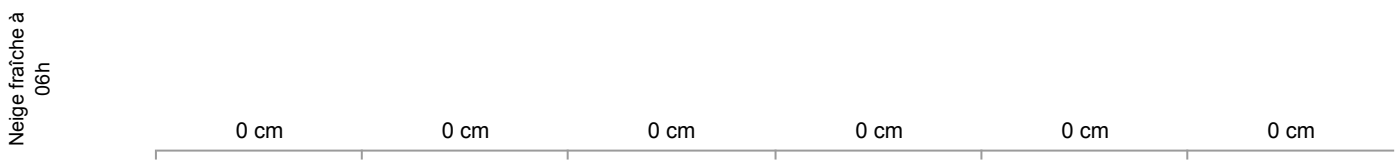

Risque d'avalanche	mar. 31/03	mer. 01/04	jeu. 02/04	ven. 03/04	sam. 04/04	dim. 05/04	lun. 06/04
	2	2	2	2	2	2	2

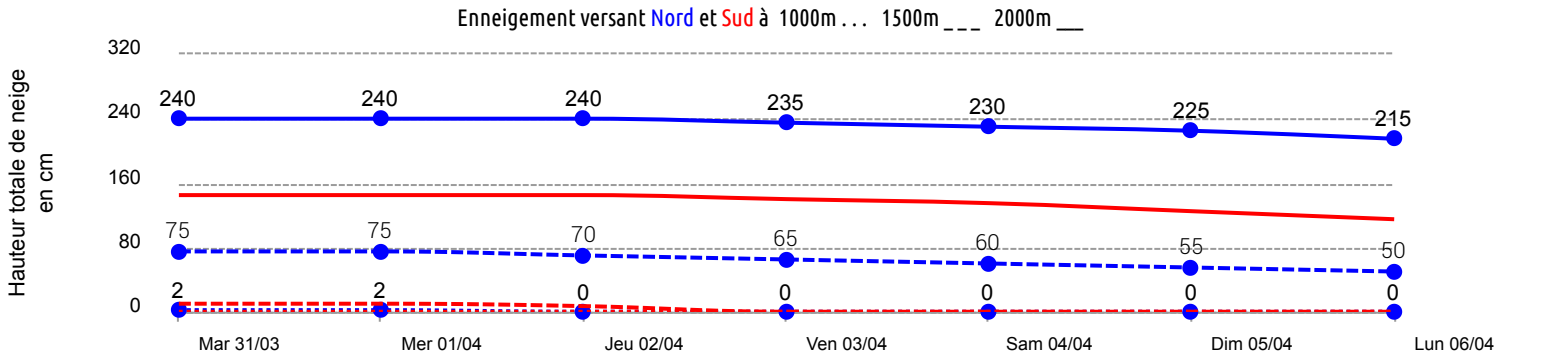

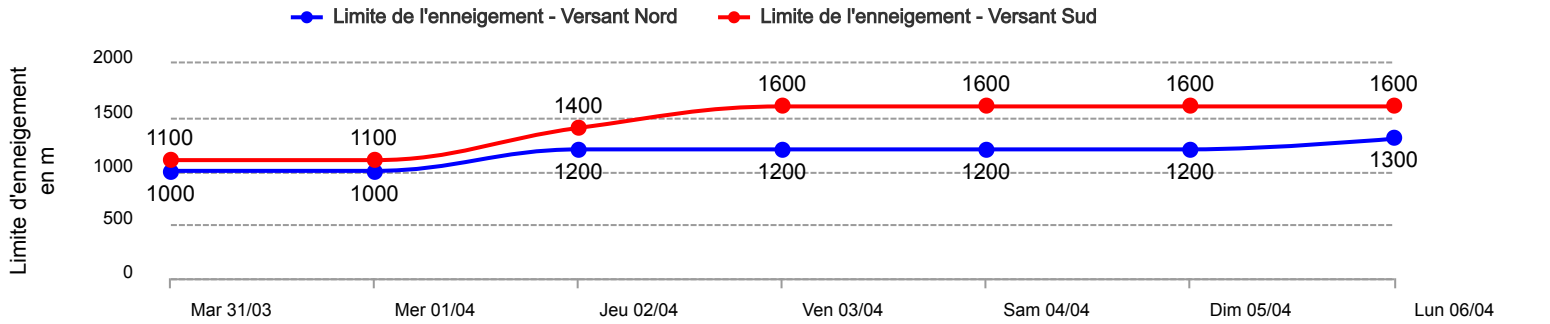

Pour consulter la vigilance en cours, veuillez vous rendre sur le site https://vigilance.meteofrance.fr/fr

Météo-France - 73 avenue de Paris, 94165 Saint-Mandé cedex - Contact : contact@meteo.fr

Rédigé par Météo-France avec la contribution des observateurs du réseau nivo-météorologiques. Partenariat : ANMSM (Maires de Stations de Montagne), DSF (Domaines Skiables de France), ADSP (Directeurs de Pistes et de la Sécurité des Stations de Sports d'Hiver) et autres acteurs de la montagne.

Bulletin neige & avalanches par téléphone au
0 892 68 10 20 Service 0,35 € / min + prix appel