GOBIERNO DE ESPAÑA
VICEPRESIDENCIA TERCERA DEL GOBIERNO
MINISTERIO PARA LA TRANSICIÓN ECOLÓGICA Y EL RETO DEMOGRÁFICO

Boletín de información nivológica y de peligro de aludes

Pirineo Catalán

aemet Agencia Estatal de Meteorología

martes, 7 de abril de 2026

Pronóstico hasta las 24 horas del miércoles, día 8 de abril

(Válido fuera de pistas de esquí balizadas y abiertas)

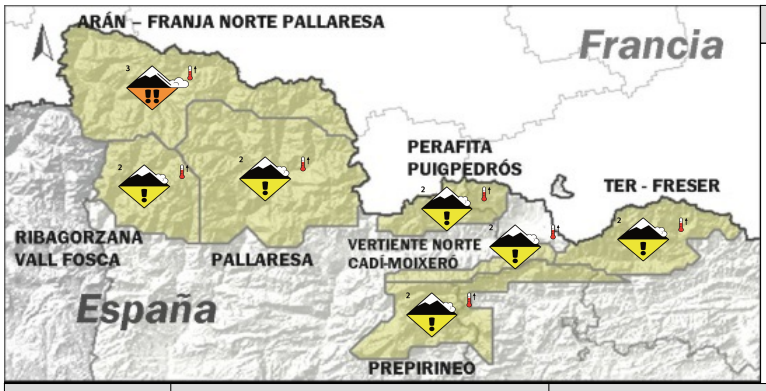

Problemas de aludes

Nieve húmeda

Capas débiles persistentes

Macizo	Peligro	Problemas de aludes, cota, orientación, tamaño	Innivación observada (m)
Arán - Franja norte Pallaresa	3 → 2→3 Por la mañana **Notable**	**Nieve húmeda** N, O, E, S; 2 **Capas débiles persistentes** 2400; N, O, E, S; 3	2026-04-07 N S Cota más baja caras N
Ribagorzana - Vall Fosca	2 → 2 **Limitado**	**Nieve húmeda** N, O, E, S; 2 **Capas débiles persistentes** 2400; N, O, E, S; 2	2026-04-07 N S Cota más baja caras N
Pallaresa	2 → 2 **Limitado**	**Nieve húmeda** N, O, E, S; 2 **Capas débiles persistentes** 2400; N, O, E, S; 2	2026-04-07 N S Cota más baja caras N

AEMET. Se autoriza la reproducción de su contenido citando la fuente.

Boletín de información nivológica y de peligro de aludes

Pirineo Catalán

Perafita - Puigpedrós	2 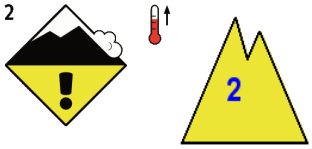 Limitado	**Nieve húmeda** 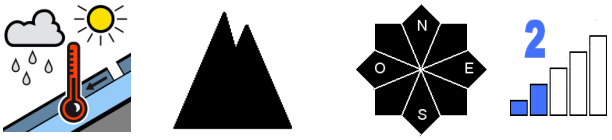 **Capas débiles persistentes** 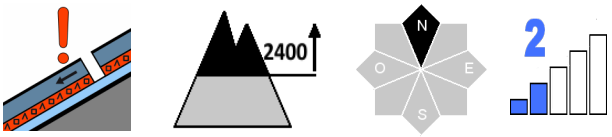	2026-04-07 Cota más baja caras N
Ter - Freser	2 Por la mañana Limitado	**Nieve húmeda** **Capas débiles persistentes** 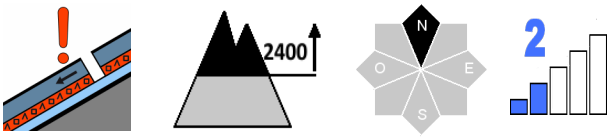	2026-04-07 Cota más baja caras N
Vertiente norte Cadí - Moixeró	2 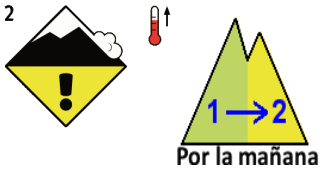 Por la mañana Limitado	**Nieve húmeda** **Capas débiles persistentes** 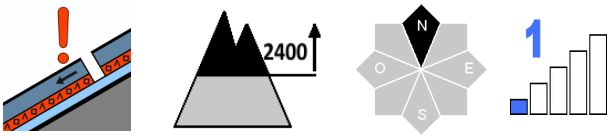	2026-04-07 Cota más baja caras N
Prepirineo	2 Limitado Por la mañana	**Nieve húmeda**	2026-04-07 Cota más baja caras N

Estado del manto y observaciones recientes

Las elevadas temperaturas y la abundante insolación de los últimos días, que van a continuar en las próximas jornadas, están intensificando la humidificación y compactación del manto, con pérdidas de unos 5-15 cm en las últimas 24 horas, así como su retroceso a cotas más elevadas. Pese a ello, presenta continuidad a partir de unos 1700 metros en umbrías y 1900 metros en solanas, algo más abajo en el Arán y la Franja Norte Pallaresa, estando los espesores muy por encima de lo que sería habitual para estas fechas. Así, a unos 2200-2400 metros se alcanzan los 120-220 cm en el Arán y los 60-170 cm en el resto, valores que se pueden superar en ventisqueros y otras zonas propensas a la acumulación.

En general, el manto está húmedo y presenta perfil primaveral, sobre todo en las solanas, aunque en cotas altas la humidificación afecta principalmente a los estratos más superficiales. A primeras horas se forman costras de rehielo en algunas zonas, pero tienden a fundirse

AEMET. Se autoriza la reproducción de su contenido citando la fuente.

rápidamente con el calentamiento diurno. Las placas de viento han ido estabilizándose, pero todavía podrían quedar activas en las altas umbrías, donde también persisten algunas capas débiles a distintas profundidades que podrían mostrar cierta reactividad.

Evolución del manto y peligro de aludes para el miércoles, día 8

Problema de nieve húmeda y deslizamientos basales. Problema de placas de viento y capas débiles persistentes en umbrías de cotas altas.

Pocos cambios en las condiciones respecto a días anteriores. De nuevo podrían formarse algunas costras de rehielo que sustenten el manto a primeras horas, pero que se fundirán rápidamente con el calentamiento diurno. Así, se esperan aludes de nieve húmeda, más probables en solanas y a partir del mediodía, incluso se podrán producir deslizamientos basales en terrenos herbosos o de roca lisa. Por lo general, serán pequeños (riesgo de caída) o medianos (capaz de enterrar a una persona), sin descartar que alguno pudiera alcanzar un tamaño algo mayor.

Las placas de viento generadas durante el pasado episodio han ido estabilizándose, aunque todavía podrán mantenerse frágiles en umbrías por encima de unos 2400 metros. Generalmente, se necesitará una sobrecarga fuerte (paso de varios esquiadores sin respetar la distancia de seguridad) para colapsarlas, provocando aludes de tamaño mediano, que podrían llegar a ser grandes (capaz de enterrar un vehículo) en las zonas de mayor acumulación o si se ve afectada alguna capa débil persistente situada a cierta profundidad.

Predicción meteorológica para el miércoles, día 8

Poco nuboso o despejado, con alguna nubosidad de evolución diurna por la tarde. Temperaturas mínimas en ascenso y máximas con pocos cambios. Algunas heladas débiles en las cumbres de mayor altitud. Predominio del viento de componente sur, flojo, con algún intervalo moderado a primeras horas.

Datos en la atmósfera libre:

Altitud de la isoterma de 0 ºC: 3300 m
Altitud de la isoterma de -10 ºC: 4700 m

Viento a 1500 m: S 20 km/h
Viento a 3000 m: S 20 km/h

Evolución para el jueves día 9

Con pocos cambios.

Escala europea de peligro de aludes

Débil | Limitado | Notable | Fuerte | Muy Fuerte

Problemas de aludes

Nieve reciente | Placas de viento | Capas débiles persistentes | Nieve húmeda | Deslizamientos basales | Sin problema evidente

Nota1: Se recuerda que, siempre que haya nieve, la ausencia total de peligro no existe. Hay que tener presente que en circunstancias desfavorables, con aludes de tamaño 1 (alud pequeño o colada) y tamaño 2 (alud mediano), se pueden sufrir severos daños personales.

AEMET. Se autoriza la reproducción de su contenido citando la fuente.

Nota2: Los BPA se elaboran en base a información meteorológica así como al estado del manto nivoso a través de sondeos puntuales. Se advierte a los usuarios de la variabilidad de esta información al extrapolarla a zonas extensas de montaña. Por ello, AEMET no se hace responsable de su uso para la toma de decisiones que conciernen a la seguridad personal, ni de los riesgos físicos o materiales de ellas derivadas.

AEMET. Se autoriza la reproducción de su contenido citando la fuente.