# Mercoledì 08.04.2026

Pubblicato il 07.04.2026 alle ore 17:00

## Mattina

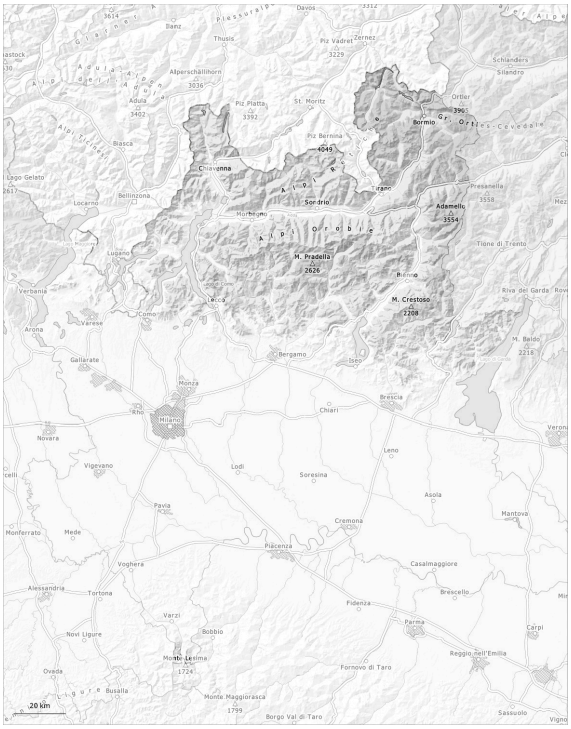
Davos
Piz Vadret
3229
Zernez
Thusis
Alpe
Schlanders
Silandro
Alpe Bella
Alpe Adona
Alpe Cavaglia
Alpe Gera
Alpe Livigno
Alpe Lepontine
Alpe Orobie
Alpe Retiche
Alpe Sarentine
Alpe Venoste
Alpe Vinschgau
Alpe Zillertal
Alpe Ötztal
Alpe Silvretta
Alpe Ortler
Alpe Cevedale
Alpe Adamello
Alpe Pennine
Alpe Lepontine
Alpe Orobie
Alpe Ligure
Alpe Marittime
Alpe Cozie
Alpe Graie

## Grado di pericolo 2 - Moderato

### AM:

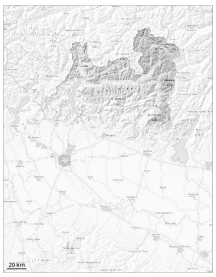

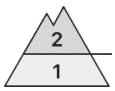


**2500m**

**Tendenza: pericolo valanghe stabile**
per Giovedì il 09.04.2026

Neve bagnata

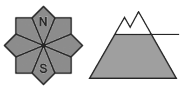


**2500m**

Strati deboli persistenti

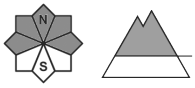


**2500m**

### PM:

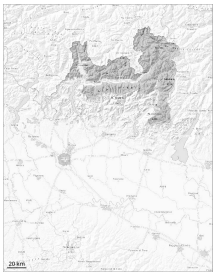

**Tendenza: pericolo valanghe stabile**
per Giovedì il 09.04.2026

Neve bagnata

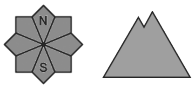

Strati deboli persistenti

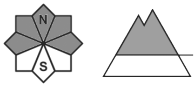


**Limite del bosco**

## Con il rialzo termico e l'irradiazione solare diurni, progressivo aumento del pericolo di valanghe umide e bagnate.

Con il rialzo termico e l'irradiazione solare diurni, sono possibili valanghe umide e bagnate di piccole e medie dimensioni a tutte le altitudini. Gli ultimi accumuli di neve ventata sono ben individuabili. Gli accumuli di neve ventata possono subire un distacco soprattutto in caso di forte sovraccarico soprattutto sui pendii ripidi ombreggiati. I punti pericolosi si trovano soprattutto nelle basi di pareti rocciose, come pure nelle zone in prossimità delle creste, nei canaloni e nelle conche.
Sui pendii esposti a nord ovest, nord e nord est, all'interno del manto di neve vecchia si trovano strati fragili. Le valanghe possono coinvolgere il manto di neve vecchia, soprattutto sui pendii esposti a nord ovest, nord e nord est, raggiungere grandi dimensioni a livello isolato.

## Manto nevoso

**Situazione tipo** st.6: neve a debole coesione e vento | st.1: strato debole persistente basale

A partire dalla mattinata queste condizioni meteo primaverili causeranno a tutte le esposizioni un inumidimento del manto nevoso. Il legame tra i vari accumuli di neve ventata e quello tra i vari accumuli di neve ventata e la neve vecchia è in corso.

> Principalmente sui pendii ombreggiati, all'interno del manto di neve vecchia si trovano isolati strati fragili. In alcuni punti, le valanghe possono subire un distacco negli strati profondi del manto nevoso soprattutto sui pendii esposti a nord ovest, nord e nord est.

## Grado di pericolo 2 - Moderato

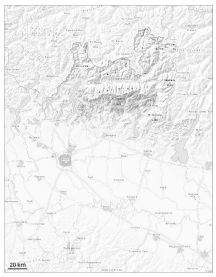

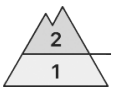


**1500m**

**Tendenza: pericolo valanghe stabile**
per Giovedì il 09.04.2026

Neve bagnata

**1500m**

Lastrone da vento

**2100m**

### Valanghe bagnate di neve a debole coesione a tutte le esposizioni.

La superficie del manto nevoso si è rigelata ed è portante e si ammorbidirà nel corso della giornata. Con il rialzo termico e l'irradiazione solare diurni, nel corso della giornata sono possibili valanghe umide e bagnate, ma per lo più solo di piccole dimensioni. Gli ultimi accumuli di neve ventata sono ben individuabili e possono subire un distacco soprattutto in seguito a un forte sovraccarico nelle zone marginali.
Le valanghe possono trascinare l'interno manto nevoso e in parte raggiungere dimensioni medie.

### Manto nevoso

**Situazione tipo** st.10: situazione primaverile st.6: neve a debole coesione e vento

La poca neve fresca e soprattutto gli accumuli di neve ventata che si sono formati con il vento di forte intensità poggiano su una sfavorevole superficie del manto di neve vecchia.
A partire dalla mattinata il calore causerà soprattutto sui pendii soleggiati in parte un progressivo ammorbidimento del manto nevoso.

## Grado di pericolo 1 - Debole

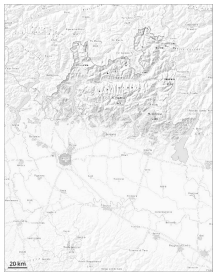

**Tendenza: pericolo valanghe stabile**
per Giovedì il 09.04.2026

Neve bagnata

**Limite del bosco**

### Neve ventata e neve bagnata sono la principale fonte di pericolo.

In prossimità delle cime, la situazione valanghiva è a livello locale per lo più favorevole. Con il rialzo termico diurno, nel corso della giornata il pericolo di valanghe bagnate aumenterà. Al di sopra dei 1500 m circa sono possibili piccole valanghe di piccole dimensioni.

### Manto nevoso

**Situazione tipo** st.10: situazione primaverile

Con il rialzo termico, la probabilità di distacco di colate e valanghe bagnate aumenterà a tutte le esposizioni a tutte le altitudini.