Mittwoch 08.04.2026

Veröffentlicht am 07.04.2026 um 17:00

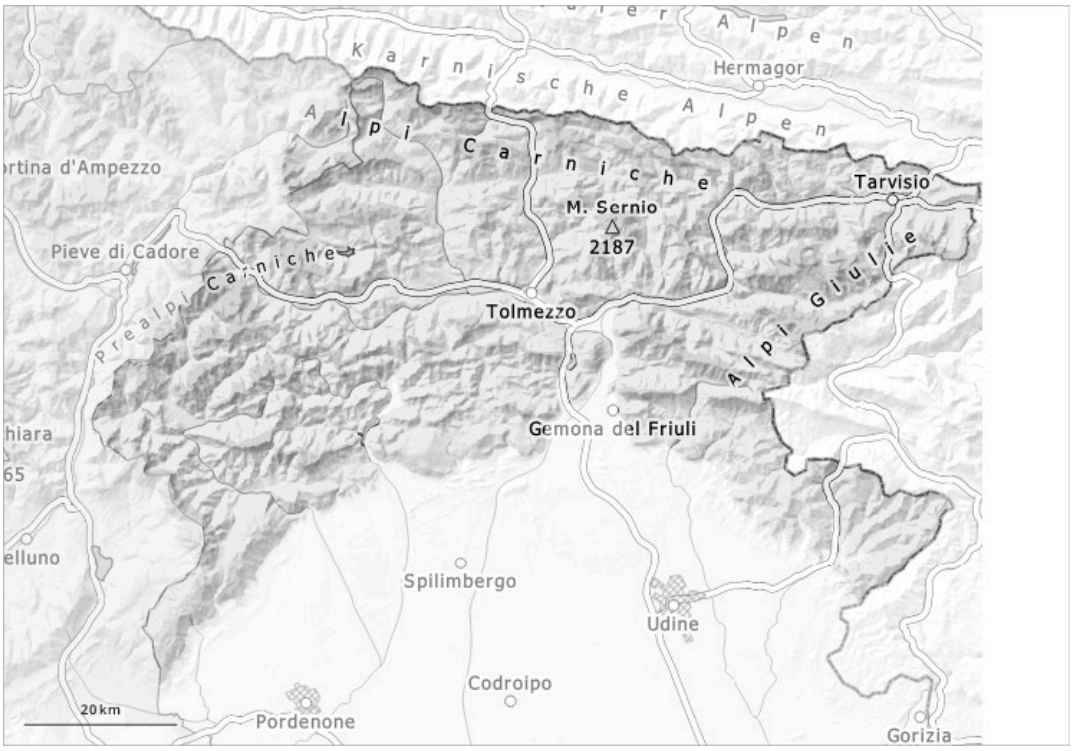

1	2	3	4	5
gering	mäßig	erheblich	groß	sehr groß

Gefahrenstufe 2 - Mäßig

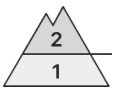

1800m

Tendenz: Lawinengefahr bleibt gleich
am Donnerstag, den 09.04.2026

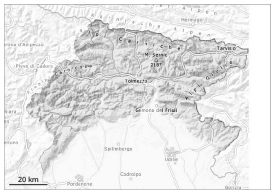

Triebschnee

1800m

Altschnee

1800m

Nassschnee

Waldgrenze

Es ist mild. Die Gefahrenstellen nehmen zu.

Der Lawinenwarndienst hat derzeit wenig Informationen aus dem Gelände, weshalb die Lawinengefahr vor Ort besonders gründlich überprüft werden sollte.
Die Gefahrenstellen liegen vor allem an Felswandfüßen, sowie in Kammlagen, Rinnen und Mulden. Die Triebschneeansammlungen bleiben teilweise störanfällig. Die spontane Lawinenaktivität nimmt mit der Erwärmung und der Sonneneinstrahlung allmählich zu. Die Lawinen können in tiefen Schichten anreißen. Zudem sind Gleitschneelawinen möglich.

Schneedecke

Snowpack thickness varies depending on exposure and altitude; especially on shady slopes, eroded areas are interspersed with deposits. In many places, hard surface crusts are present, and near the ridges, there are evident cornices. In der Schneedecke sind vor allem an Schattenhängen Schwachschichten vorhanden. Die Wetterbedingungen führen zu einer allmählichen Durchnässung der Schneedecke.

Tendenz

Es ist teilweise sonnig.