ICGC Institut Cartogràfic i Geològic de Catalunya

Servei Meteorològic de Catalunya meteo.cat

Boletín de peligro de aludes para el Pirineo de Catalunya
Del 07/04/2026 al 08/04/2026

(Válido fuera pistas de esquí y zonas no controladas)

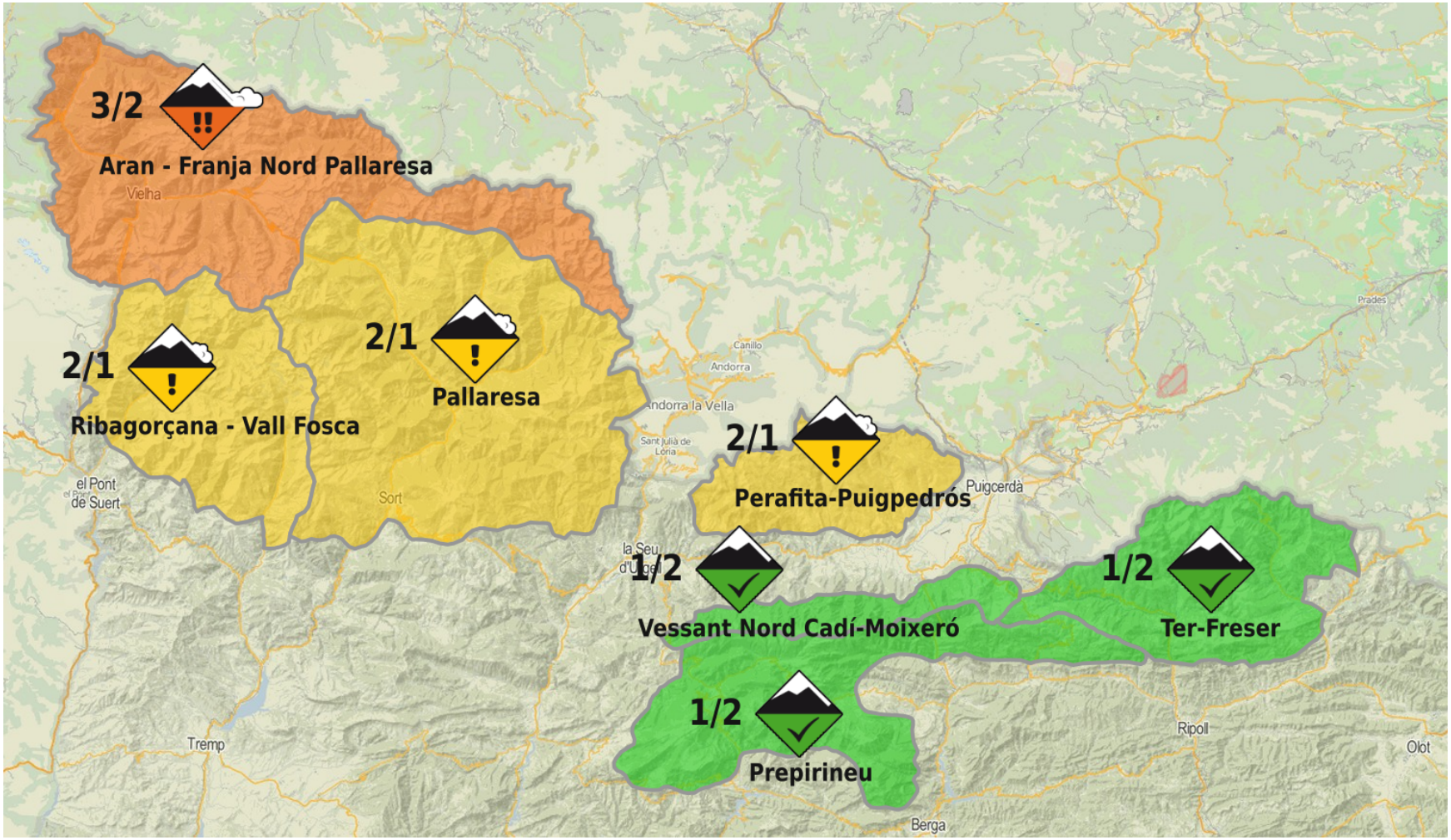

5 MUY FUERTE	4 FUERTE	3 NOTABLE	2 LIMITADO	1 DÉBIL

ICGC Institut Cartogràfic i Geològic de Catalunya

Servei Meteorològic de Catalunya meteo.cat

Boletín de peligro de aludes Aran - Franja Nord Pallaresa Del 07/04/2026 al 08/04/2026

(Válido fuera pistas de esquí y zonas no controladas)

NOTABLE (3) a partir de media mañana. LIMITADO (2) durante el resto del día.

Situación primaria

Capas débiles persistentes

Distribución

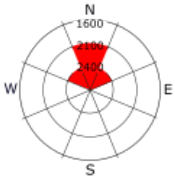

Tamaño

Origen

Tendencia

Situación secundaria

Nieve húmeda

Distribución

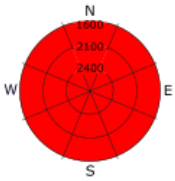

Tamaño

Origen

Tendencia

Estado del manto nivoso

Han caído aludes naturales de placa de tamaños 2 y 3 (suficiente para enterrar a un grupo de personas) en forma de placas blandas por encima de niveles débiles persistentes. Los aludes accidentales siguen siendo probables por encima de 2.300 m en terreno umbrío por sobrecarga débil. Allí donde encontramos la nieve ligeramente placada, en sectores protegidos del viento, aunque superficialmente haya humedecido ligeramente, los aludes serán todavía posibles, en especial en el Arán. Además se espera que el manto se humedezca después del rehielo nocturno y que a partir de media mañana haya aludes de nieve húmeda de tamaños 1 y 2 (suficiente para enterrar a una persona). Serán más frecuentes en las cotas más bajas y en el terreno más soleado, cerca de puntos oscuros como rocas y árboles. En las umbrías más elevadas no se descarta la caída natural de placas húmedas de hasta tamaño 3. También se espera la caída natural de deslizamientos basales de tamaño 2 en terreno herboso y pulido.

Distribución del manto nivoso

Los espesores a unos 2.200 m son ligeramente superiores a los normales en la Franja Norte de la Pallaresa y en la mitad sur de Arán, donde rondan los 180-220 cm. En la mitad norte del Arán son los normales por estas fechas con unos 140-160 cm de espesor total.

Tendencia para las próximas 48-72h

Pasará a prediminar el problema de nieve húmeda, así como los deslizamientos basales, que en terreno propicio irán tomando protagonismo. Peligro: SIN CAMBIOS.

El próximo boletín será emitido el día 2026-04-08

5 MUY FUERTE	4 FUERTE	3 NOTABLE	2 LIMITADO	1 DÉBIL

EAWS EUROPEAN AVALANCHE WARNING SERVICES

ICGC Institut Cartogràfic i Geològic de Catalunya

Servei Meteorològic de Catalunya

Boletín de peligro de aludes Ribagorçana - Vall Fosca Del 07/04/2026 al 08/04/2026

(Válido fuera pistas de esquí y zonas no controladas)

LIMITADO (2) en la mitad norte. DÉBIL (1) en la mitad sur.

Situación primaria

Nieve húmeda

Distribución

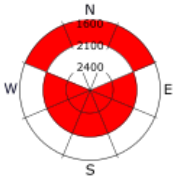

Tamaño

Origen

Tendencia

Situación secundaria

Capas débiles persistentes

Distribución

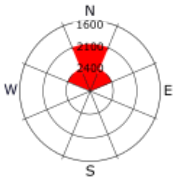

Tamaño

Origen

Tendencia

Estado del manto nivoso

En gran parte del terreno la nieve presenta un comportamiento primaveral. A primera hora se encuentra encostrada, pero se transforma por la insolación y las temperaturas elevadas. Se esperan a partir de media mañana aludes de nieve húmeda en terreno bastante inclinado, especialmente alrededor de puntos rocosos y afectando a la nieve más superficial; serán de tamaño 1 (pequeño, con capacidad de arrastrarnos). En terreno muy umbrío los aludes de nieve húmeda serán poco probables. Además, en la mitad norte del sector actualmente existen placas de viento antiguas en lugares protegidos de todas las orientaciones. Se mantienen las capas débiles persistentes. Pueden caer aludes de placa al paso de personas. Las más sensibles se encuentran entre 2.300 y 2.500 m, aproximadamente, en terreno umbrío y sectores protegidos del viento. En caso de caer, los aludes de placa podrán alcanzar tamaño 2 (mediano, suficiente para enterrar a una persona).

Distribución del manto nivoso

La nieve es continúa a partir de 1.700 m en terreno umbrío y de 1.900 m en solanas. Los grosores alcanzan los 100-120 cm a unos 2.200 m, con frecuentes deflaciones y acumulaciones por encima del nivel del bosque. Estos valores se acercan a los normales para la época.

Tendencia para las próximas 48-72h

Se espera que el problema de nieve húmeda sea el más importante. Peligro SIN CAMBIOS.

El próximo boletín será emitido el día 2026-04-08

5 MUY FUERTE	4 FUERTE	3 NOTABLE	2 LIMITADO	1 DÉBIL

EAWS EUROPEAN AVALANCHE WARNING SERVICES

ICGC Institut Cartogràfic i Geològic de Catalunya

Servei Meteorològic de Catalunya

Boletín de peligro de aludes Pallaresa
Del 07/04/2026 al 08/04/2026

(Válido fuera pistas de esquí y zonas no controladas)

LIMITADO (2) en la mitad norte. DÉBIL (1) en la mitad sur.

Situación primaria

Nieve húmeda

Distribución

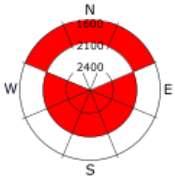

Tamaño

Origen

Tendencia

Situación secundaria

Capas débiles persistentes

Distribución

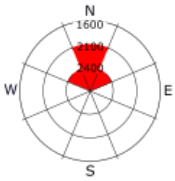

Tamaño

Origen

Tendencia

Estado del manto nivoso

En gran parte del terreno la nieve presenta un comportamiento primaveral. A primera hora se encuentra encostrada, pero se transforma por la insolación y las temperaturas elevadas. Se esperan a partir de media mañana aludes de nieve húmeda en terreno bastante inclinado, especialmente alrededor de puntos rocosos y afectando a la nieve más superficial; serán de tamaño 1 (pequeño, con capacidad de arrastrarnos). En terreno muy umbrío los aludes de nieve húmeda serán poco probables. Además, en la mitad norte del sector actualmente existen placas de viento antiguas en lugares protegidos de todas las orientaciones. Se mantienen las capas débiles persistentes. Pueden caer aludes de placa al paso de personas. Las más sensibles se encuentran entre 2.300 y 2.500 m, aproximadamente, en terreno umbrío y sectores protegidos del viento. En caso de caer, los aludes de placa podrán alcanzar tamaño 2 (mediano, suficiente para enterrar a una persona).

Distribución del manto nivoso

La nieve se continúa a partir de 1.700 ma terreno umbrío y de 1.900 ma solanas. Los grosores alcanzan los 100-120 cm a unos 2.200 m, con frecuentes deflaciones y acumulaciones por encima del nivel del bosque. Estos valores se acercan a los normales para la época.

Tendencia para las próximas 48-72h

Se espera que el problema de nieve húmeda sea el más importante. Peligro SIN CAMBIOS.

El próximo boletín será emitido el día 2026-04-08

5 MUY FUERTE	4 FUERTE	3 NOTABLE	2 LIMITADO	1 DÉBIL

EAWS EUROPEAN AVALANCHE WARNING SERVICES

ICGC Institut Cartogràfic i Geològic de Catalunya

Servei Meteorològic de Catalunya

Boletín de peligro de aludes Perafita-Puigpedrós Del 07/04/2026 al 08/04/2026

(Válido fuera pistas de esquí y zonas no controladas)

LIMITADO (2) en el extremo norte. DÉBIL (1) en la mitad sur.

Situación primaria

Nieve húmeda

Distribución

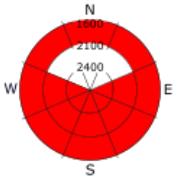

Tamaño

Origen

Tendencia

Situación secundaria

Capas débiles persistentes

Distribución

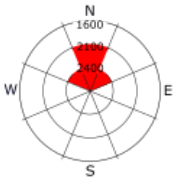

Tamaño

Origen

Tendencia

Estado del manto nivoso

En gran parte del terreno la nieve presenta un comportamiento primaveral. A primera hora se encuentra encostrada, pero se transforma por la insolación y las temperaturas elevadas. Se esperan a partir de media mañana aludes de nieve húmeda en terreno bastante inclinado, especialmente alrededor de puntos rocosos y afectando a la nieve más superficial; serán de tamaño 1 (pequeño, con capacidad de arrastrarnos). En terreno muy umbrío los aludes de nieve húmeda serán poco probables. Además, en el extremo norte del sector actualmente existen placas de viento antiguas en lugares resguardados de todas las orientaciones. Se mantienen las capas débiles persistentes. Pueden caer aludes de placa al paso de personas. Las más sensibles se encuentran entre 2.300 y 2.500 m, aproximadamente, en terreno umbrío y sectores protegidos del viento. En caso de caer, los aludes de placa podrán alcanzar tamaño 2 (mediano, suficiente para enterrar a una persona).

Distribución del manto nivoso

Hay nieve en el suelo con cierta continuidad por encima de unos 1.900 m en terreno umbrío, y de 2.200 m en solanas. Es esquiable a partir de unos 2.000 m en N. Los espesores, aunque irregulares, rondan los 70-110 cm en umbrías, a 2.300 m; existen frecuentes deflaciones y acumulaciones por encima del nivel del bosque. Son grosores por encima de los habituales en esta época.

Tendencia para las próximas 48-72h

Se espera que el problema de nieve húmeda sea el más importante. Peligro SIN CAMBIOS.

El próximo boletín será emitido el día 2026-04-08

5 MUY FUERTE	4 FUERTE	3 NOTABLE	2 LIMITADO	1 DÉBIL

EAWS EUROPEAN AVALANCHE WARNING SERVICES

ICGC Institut Cartogràfic i Geològic de Catalunya

Servei Meteorològic de Catalunya meteo.cat

Boletín de peligro de aludes Vessant Nord Cadí-Moixeró Del 07/04/2026 al 08/04/2026

(Válido fuera pistas de esquí y zonas no controladas)

DÉBIL (1). LIMITADO (2) a partir de media mañana.

Situación primaria

Nieve húmeda

Distribución

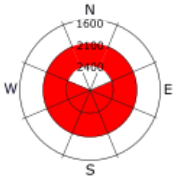

Tamaño

Origen

Tendencia

Situación secundaria

Capas débiles persistentes

Distribución

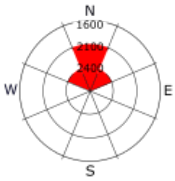

Tamaño

Origen

Tendencia

Estado del manto nivoso

Actualmente hay placas de viento antiguas principalmente en el Moixeró, ya que en el Cadí las nevadas fueron muy escasas la semana pasada. En la sombra se están formando capas débiles internas por debajo de las placas. Se pueden desencadenar algunos aludes de placa al paso de un grupo de personas en las umbrías más elevadas. En caso de desprenderse se tratará de aludes de tamaño 1 (pequeño, suficiente para arrastrarnos). Además, se espera que continúe el humedecimiento del manto debido a la insolación y al incremento de temperaturas. Habrá aludes de nieve húmeda que afectarán sobre todo a la nieve más superficial y blanda. Estos aludes tendrán lugar en el terreno más soleado, bastante inclinado y a partir de puntos rocosos; serán por lo general de tamaño 1, suficiente para producir caídas y lesiones.

Distribución del manto nivoso

En umbrías hay nieve por encima de unos 1.600 m; en solanas por encima de unos 2.000 m. Los grosores están alrededor de 150-170 cm a 2.200 m, con algunas acumulaciones y deflaciones por encima del nivel del bosque. Estos valores son muy excedentarios para la época del año.

Tendencia para las próximas 48-72h

Continuará el comportamiento primaveral del manto, con algunos aludes de fusión en momentos de insolación. Peligro SIN CAMBIOS.

El próximo boletín será emitido el día 2026-04-08

5 MUY FUERTE	4 FUERTE	3 NOTABLE	2 LIMITADO	1 DÉBIL

EAWS EUROPEAN AVALANCHE WARNING SERVICES

ICGC Institut Cartogràfic i Geològic de Catalunya

Servei Meteorològic de Catalunya

Boletín de peligro de aludes Prepirineu
Del 07/04/2026 al 08/04/2026

(Válido fuera pistas de esquí y zonas no controladas)

DÉBIL (1). LIMITADO (2) a partir de media mañana.

Situación primaria

Nieve húmeda

Distribución

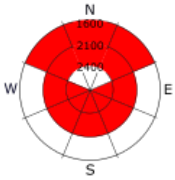

Tamaño

Origen

Tendencia

Estado del manto nivoso

Las condiciones son de primavera avanzada en el sector. El manto se presenta húmedo durante las horas diurnas, ablandándose tanto en sur como en norte, y se enfría y rehiela a lo largo de la noche. Podrán caer purgas de nieve húmeda a partir de media mañana en terreno muy inclinado, especialmente en torno a puntos rocosos. Los aludes esperados serán de tamaño 1 (pequeños, suficiente para generar caídas y lesiones). El terreno elevado y umbría será el menos afectado por estos aludes. Internamente el manto se presenta todavía endurecido fuera del terreno más soleado. Hay que evitar el terreno donde la penetración de la bota o el esquí sean profundas, y las laderas en las que observamos caída de purgas.

Distribución del manto nivoso

Aunque podemos encontrar nieve en cotas más bajas por el último episodio de nevadas, el manto es continuo por encima de unos 1.800 m a terreno umbrío y de unos 2.000 m a solanas. Los espesores, aunque irregulares, rondan los 80-110 cm a 2.300 m.

Tendencia para las próximas 48-72h

El humedecimiento durante las horas de máxima insolación seguirán siendo el principal elemento a tener en cuenta. Peligro SIN CAMBIOS.

El próximo boletín será emitido el día 2026-04-08

5 MUY FUERTE	4 FUERTE	3 NOTABLE	2 LIMITADO	1 DÉBIL

EAWS EUROPEAN AVALANCHE WARNING SERVICES

ICGC Institut Cartogràfic i Geològic de Catalunya

Servei Meteorològic de Catalunya

Boletín de peligro de aludes Ter-Freser
Del 07/04/2026 al 08/04/2026

(Válido fuera pistas de esquí y zonas no controladas)

DÉBIL (1). LIMITADO (2) a partir de media mañana.

Situación primaria

Nieve húmeda

Distribución

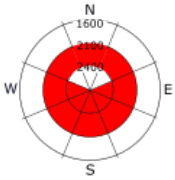

Tamaño

Origen

Tendencia

Situación secundaria

Capas débiles persistentes

Distribución

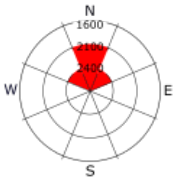

Tamaño

Origen

Tendencia

Estado del manto nivoso

El manto se presenta húmedo durante las horas diurnas y se enfría y rehiela a lo largo de la noche. Podrán caer purgas de nieve húmeda en terreno muy pendiente soleado, especialmente alrededor de puntos rocosos y afectando principalmente a la nieve superficial de los últimos episodios. El terreno elevado y menos soleado será el menos afectado por estos aludes. Hay que evitar el terreno donde la penetración de la bota o el esquí sean profundas, así como laderas en las que observamos caídas de purgas. En terreno muy umbrío las placas de viento formadas en la última nevada reposan a menudo sobre niveles de nieve granulada. Al paso de un grupo de personas se podrían desencadenar aludes de placa de hasta tamaño 2 (suficiente para enterrar a una persona). El manto es todavía sensible a estos desencadenamientos donde la nieve se encuentre seca y no encostrada.

Distribución del manto nivoso

El manto es esquiable a umbrías a partir de unos 1.800 m en umbrías. Los grosores son muy excedentarios para la época del año y en lugares no afectados por el viento oscilan entre 70-100 cm a unos 2.000 m, y más de 150 cm por encima de 2.400 m, muy variable por los efectos del viento.

Tendencia para las próximas 48-72h

Durante la semana, el humedecimiento durante las horas de máxima insolación seguirá siendo el principal elemento a tener en cuenta. Peligro SIN CAMBIOS.

El próximo boletín será emitido el día 2026-04-08

5 MUY FUERTE	4 FUERTE	3 NOTABLE	2 LIMITADO	1 DÉBIL

EAWS EUROPEAN AVALANCHE WARNING SERVICES