BUTLLETÍ DEL PERILL D'ALLAUS DEL PRINCIPAT D'ANDORRA

Servei meteorològic nacional
Principat d'Andorra

Elaborat el 07/04/2026 16:00
Propera actualització 08/04/2026 a les 16h

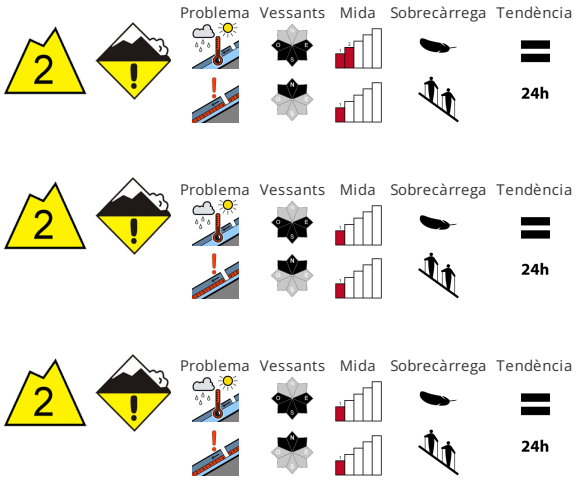

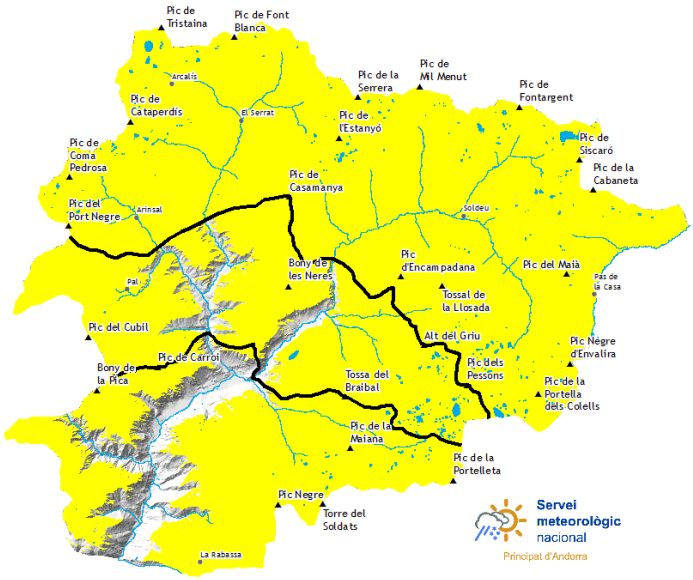

ESTABILITAT DEL MANTELL NIVAL

Amb l'augment de la temperatura diurna i la radiació solar, la probabilitat de desencadenament d'allaus humides augmentarà progressivament als vessants assolellats. A més, són possibles algunes allaus de lliscament basal. Als vessants obacs, són encara possibles allaus de placa seca. Les allaus són sovint de mida mitjana i poden ser desencadenades per fortes sobrecàrregues.

QUALITAT DE LA NEU

El temps serà assolellat. La superfície del mantell de neu es regelarà per formar una crosta portant i s'estovarà al llarg del dia. El mantell de neu roman extremadament variable en pocs metres de manera generalitzada. Prop de les carenes els gruixos de neu varien molt per la influència del vent. En alguns sectors encara hi ha molta neu. A causa de la superfície dura del mantell de neu hi ha el perill de relliscar i caure fins i tot en vessants moderadament inclinats. Les excursions de muntanya han de començar i acabar d'hora.

GRUIXOS DEL MANTELL NIVAL FORA DE PISTA

Zona nord		Gruix neu		
Mantell Nival		1500m	2000m	2500m
N	1300 m	20 cm	180 cm	250 cm
S	1300 m	10 cm	150 cm	200 cm

Zona centre		Gruix neu		
Mantell Nival		1500m	2000m	2500m
N	1300 m	10 cm	150 cm	200 cm
S	1500 m	5 cm	100 cm	150 cm

Zona sud		Gruix neu		
Mantell Nival		1500m	2000m	2500m
N	1300 m	10 cm	120 cm	160 cm
S	1500 m	5 cm	60 cm	120 cm

Govern d'Andorra

EAWS EUROPEAN AVALANCHE WARNING SERVICES

Aquest butlletí ha estat elaborat seguint les normes i recomanacions de l'**European Avalanche Warning Services**, del qual el **Servei meteorològic Nacional** n'és membre

Informació detallada per espais naturals protegits

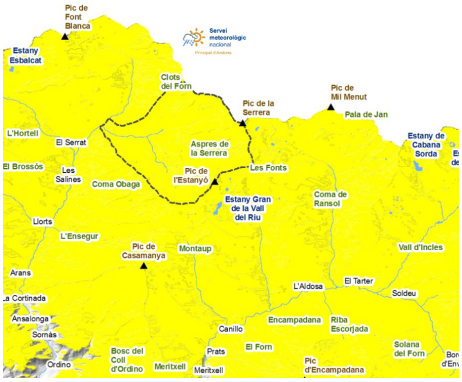

SORTENY

Als vessants sud han tornat a quedar al descobert les estries de la percolació de l´aigua, fet que ens dona indicis de l´estabilitat. Al matí, però, la neu dura ens ha de fer extremar les precaucions per no relliscar. Als vessants nord, identificarem les acumulacions de neu ventada pel seu color. Sempre serà més segur, quant a estabilitat d´allaus, circular per la neu dura.

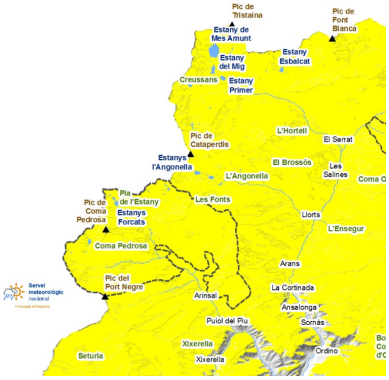

COMAPEDROSA

Encara es poden fer nombroses excursions amb esquí de muntanya, però les parts baixes d´Arinsal no tenen neu. O bé ens haurem d´aproximar esquiant o bé hi haurem d´accedir per Soulcem o l´Angonella. Haurem d´accedir-hi aviat al matí, ja que hem de tenir temps suficient per tornar quan la neu encara no hagi transformat excessivament.

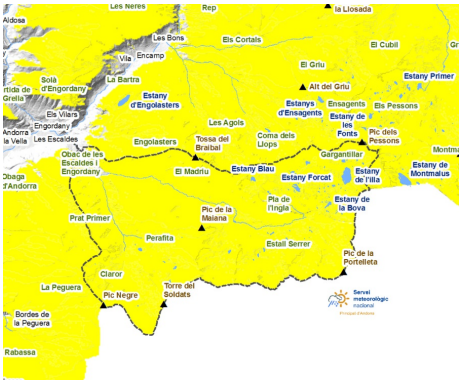

MADRIU-PERAFITA-CLAROR

Les condicions són primaverals, però als vessants nord més inclinats i obacs encara poden trobar alguna placa de neu seca que haurem d´evitar

BUTLLETÍ DEL PERILL D'ALLAUS DEL PRINCIPAT D'ANDORRA

Servei meteorològic nacional
Principat d'Andorra

Gruixos de neu nova dels darrers dies (de les últimes 24h mesurat a les 06:00h UTC)

	03/04/2026	04/04/2026	05/04/2026	06/04/2026
FEDA (Central)	0 cm	0 cm	0 cm	0 cm
Engolasters - FEDA	0 cm	0 cm	0 cm	0 cm
Bony de les Neres	0 cm	0 cm	0 cm	0 cm
Les Fonts d'Arinsal	0 cm	0 cm	0 cm	0 cm
Perafita	0 cm	0 cm	0 cm	0 cm
Tossa Espiolets	0 cm	0 cm	0 cm	0 cm
Grau Roig - FEDA	0 cm	0 cm	0 cm	0 cm
Fontverd	0 cm	0 cm	0 cm	0 cm
Coll Ordino	0 cm	0 cm	72 cm	0 cm
Ransol - FEDA	0 cm	0 cm	0 cm	0 cm
Setúria	0 cm	0 cm	0 cm	0 cm
Caborreu	0 cm	0 cm	0 cm	0 cm
La Solana	0 cm	0 cm	0 cm	0 cm
Coll Pa	0 cm	0 cm	0 cm	0 cm
Vall del Riu FEDA	0 cm	0 cm	0 cm	0 cm