BUTLLETÍ DEL PERILL D'ALLAUS DEL PRINCIPAT D'ANDORRA

Elaborado el 07/04/2026 16:00
Proxima actualización 08/04/2026 a las 16h

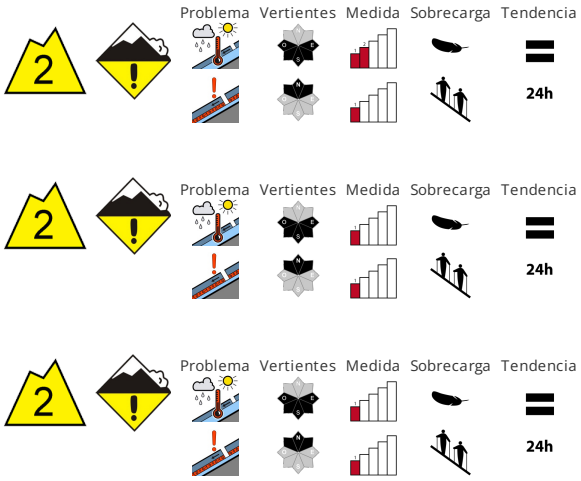

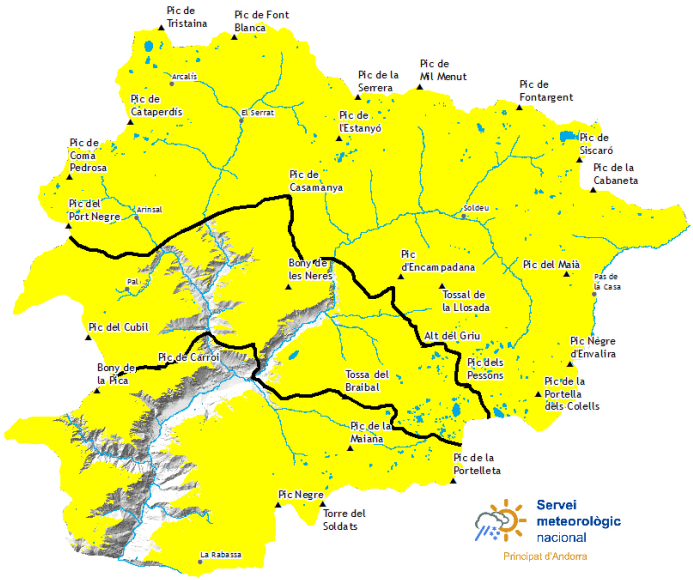

CALIDAD DE LA NIEVE

Con el aumento de la temperatura diurna y la radiación solar, la probabilidad de desencadenamiento de aludes de nieve húmeda aumentará progresivamente en las laderas solanas. Además son posibles algunos aludes de deslizamiento basal. En las laderas umbrías, son posibles avalanchas de placa seca. Los aludes son a menudo de tamaño mediano y pueden ser desencadenados por fuertes sobrecargas.

ESTABILIDAD DEL MANTO NIVOSO

El tiempo será soleado. La superficie del manto de nieve se volverá a helar para formar una costra portante y se ablandará durante el día. El manto de nieve permanece extremadamente variable en pocos metros en general. Cerca de los cordales los espesores de nieve varían mucho por la influencia del viento. En algunos sectores aún hay mucha nieve. Debido a la superficie dura del manto de nieve hay el peligro de resbalar y caer incluso en laderas moderadamente inclinadas. Las excursiones de montaña deben comenzar y acabar temprano.

ESPESORES DEL MANTO NIVOSO FUERA DE PISTA

Zona norte		Espesor nieve		
Manto Nival		1500m	2000m	2500m
N	1300 m	20 cm	180 cm	250 cm
S	1300 m	10 cm	150 cm	200 cm

zona centro		Espesor nieve		
Manto Nival		1500m	2000m	2500m
N	1300 m	10 cm	150 cm	200 cm
S	1500 m	5 cm	100 cm	150 cm

Zona sur		Espesor nieve		
Manto Nival		1500m	2000m	2500m
N	1300 m	10 cm	120 cm	160 cm
S	1500 m	5 cm	60 cm	120 cm

Govern d'Andorra

EAWS EUROPEAN AVALANCHE WARNING SERVICES

Aquest butlletí ha estat elaborat seguint les normes i recomanacions de l'**European Avalanche Warning Services**, del qual el **Servei meteorològic Nacional** n'és membre

Información detallada por espacios naturales protegidos

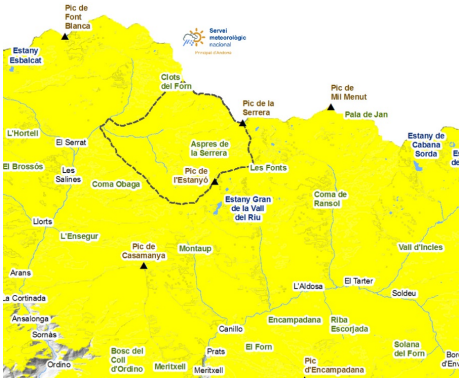

SORTENY

En la vertiente sur, las vetas de filtración de agua han vuelto a quedar al descubierto, lo que nos da señales de estabilidad. Por la mañana, sin embargo, la dura nieve nos obligará a extremar las precauciones para no resbalar. En la vertiente norte identificaremos las acumulaciones de nieve arrastradas por su color. Siempre será más seguro, en términos de estabilidad ante avalanchas, conducir sobre nieve dura. , , , , , , ,

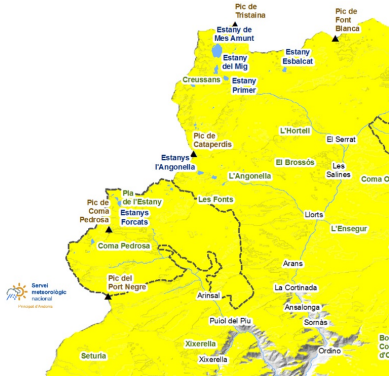

COMAPEDROSA

Aún se pueden realizar numerosas excursiones en esquí de montaña, pero las partes bajas de Arinsal no tienen nieve. O tendremos que aproximarnos esquiando o tendremos que acceder por Soulcem o Angonella. Deberemos acceder pronto por la mañana, ya que debemos tener tiempo suficiente para volver cuando la nieve todavía no haya transformado excesivamente.

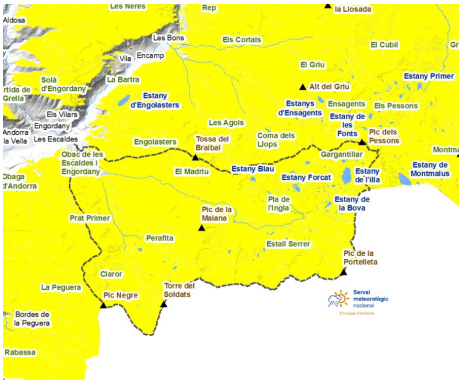

MADRIU-PERAFITA-CLAROR

Las condiciones son primaverales, pero en las vertientes norte más inclinadas y umbrías todavía pueden encontrar alguna placa de nieve seca que deberemos evitar

BUTLLETÍ DEL PERILL D'ALLAUS DEL PRINCIPAT D'ANDORRA

Servei meteorològic nacional
Principat d'Andorra

Espesores de nieve nueva de los últimos días (de las ultimas 24h mesurado a las 06:00h UTC)

	03/04/2026	04/04/2026	05/04/2026	06/04/2026
FEDA (Central)	0 cm	0 cm	0 cm	0 cm
Engolasters - FEDA	0 cm	0 cm	0 cm	0 cm
Bony de les Neres	0 cm	0 cm	0 cm	0 cm
Les Fonts d'Arinsal	0 cm	0 cm	0 cm	0 cm
Perafita	0 cm	0 cm	0 cm	0 cm
Tossa Espiolets	0 cm	0 cm	0 cm	0 cm
Grau Roig - FEDA	0 cm	0 cm	0 cm	0 cm
Fontverd	0 cm	0 cm	0 cm	0 cm
Coll Ordino	0 cm	0 cm	72 cm	0 cm
Ransol - FEDA	0 cm	0 cm	0 cm	0 cm
Setúria	0 cm	0 cm	0 cm	0 cm
Caborreu	0 cm	0 cm	0 cm	0 cm
La Solana	0 cm	0 cm	0 cm	0 cm
Coll Pa	0 cm	0 cm	0 cm	0 cm
Vall del Riu FEDA	0 cm	0 cm	0 cm	0 cm