RÉPUBLIQUE FRANÇAISE
*Liberté Égalité Fraternité*

METEO FRANCE
À VOS CÔTÉS, DANS UN CLIMAT QUI CHANGE

# Bulletin d'estimation du risque d'avalanche
## (valable en dehors des pistes balisées et ouvertes)

# MASSIF : Aravis

Rédigé le mardi 7 avril 2026 à 16h

## Estimation des risques pour le : MERCREDI 08 AVRIL

**LE PRINTEMPS S'INSTALLE**

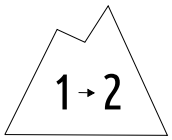


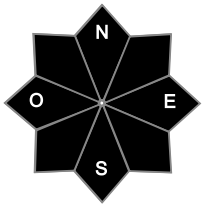


Indice de risque faible évoluant en limité.

**Départs spontanés :** avalanches de neige humide

**Déclenchements provoqués :** avalanches de neige humide

Indices de risque : 5 très fort - 4 fort - 3 marqué - 2 limité - 1 faible -- En noir : les pentes les plus dangereuses

## Stabilité du manteau neigeux

**Situation avalancheuse typique :** neige humide avalanches de fond

Déclenchements provoqués :
* **avalanches de neige humide**, de plus en **plus nombreuses au fil du réchauffement** et du rayonnement solaire. En toutes orientations et altitudes. Taille 1 à 2 (petite à moyenne) et rarement 3 (grande). Au-dessus de **2200 m**, de petits départs ponctuels peuvent **déclencher, en cascade, une plaque** de fond ou seulement en surface.
* quelques **plaques de fond** dans les zones herbeuses ou les dalles rocheuses, à toute heure du jour ou de la nuit. En dessous de 2100 m en nord et 2500 m en sud. Taille 2 (moyenne).

Départs spontanés :
* **avalanches de neige humide** en sud et en dessous de 2500 m en nord. Facile à déclencher au soleil. Départ ponctuel sous les skis, pouvant parfois déclencher, en cascade, une petite plaque. Taille 1 à 2 (petite à moyenne). Causé par le réchauffement et le rayonnement solaire.

## Qualité de la neige

Enneigement :
Pour la saison, l'enneigement est correct.
On peut chausser les skis au-dessus de 1600 m en sud et 1300/1400 m en nord.

Qualité de la neige ce mercredi matin :
Bon regel nocturne. Manteau neigeux printanier sous 2600 m en sud et 2000 m en nord.
L'humidification de surface a progressé à toutes altitudes.
Corniches fragilisées par le redoux.

## Aperçu météo pour le mercredi 08 avril

| nuit | matin | après-midi | soir |
|---|---|---|---|

Journée ensoleillée. Températures maximales : 12°C à 2000 m et 16°C à 1500 m.

| Pluie-Neige | | | | |
|---|---|---|---|---|
| Iso 0 °C | 3 300 m | 3 400 m | 3 400 m | 3 400 m |
| Vent 2000 m | 25 km/h | 20 km/h | 5 km/h | 5 km/h |
| Vent 2500 m | 20 km/h | 25 km/h | 5 km/h | 5 km/h |

## Épaisseur de neige hors-piste

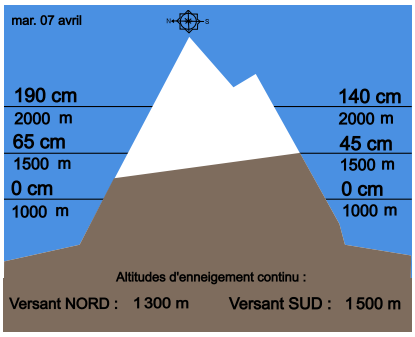


## Précipitations à 1800 m

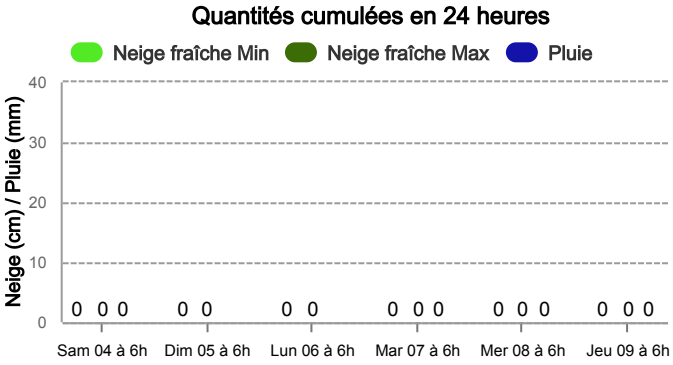


## Tendance du jeudi 09 avril

**Indice de risque limité**

Jeudi : journée ensoleillée, vent calme et isotherme 0°C en baisse vers 3000 m.
⇒ risque stable, poursuite de l'humidification du manteau neigeux.

Pour consulter la vigilance en cours, veuillez vous rendre sur le site https://vigilance.meteofrance.fr/fr

Météo-France - 73 avenue de Paris, 94165 Saint-Mandé cedex - Contact : contact@meteo.fr

Rédigé par Météo-France avec la contribution des observateurs du réseau nivo-météorologiques. Partenariat : ANMSM (Maires de Stations de Montagne), DSF (Domaines Skiables de France), ADSP (Directeurs de Pistes et de la Sécurité des Stations de Sports d'Hiver) et autres acteurs de la montagne.

Bulletin neige & avalanches par téléphone au
**0 892 68 10 20** Service 0,35 € / min + prix appel

RÉPUBLIQUE FRANÇAISE
*Liberté Égalité Fraternité*

METEO FRANCE
À VOS CÔTÉS, DANS UN CLIMAT QUI CHANGE

# Bulletin d'estimation du risque d'avalanche

## (valable en dehors des pistes balisées et ouvertes)

# MASSIF : Aravis

Rédigé le mardi 7 avril 2026 à 16h

## Conditions nivo-météo des 7 derniers jours

| | mer. 01/04 | | | | jeu. 02/04 | | | | ven. 03/04 | | | | sam. 04/04 | | | | dim. 05/04 | | | | lun. 06/04 | | | | mar. 07/04 | | | |
|---|---|---|---|---|---|---|---|---|---|---|---|---|---|---|---|---|---|---|---|---|---|---|---|---|---|---|---|---|
| | 03h | 09h | 15h | 21h | 03h | 09h | 15h | 21h | 03h | 09h | 15h | 21h | 03h | 09h | 15h | 21h | 03h | 09h | 15h | 21h | 03h | 09h | 15h | 21h | 03h | 09h | 15h | 21h |
| Météo | | | | | | | | | | | | | | | | | | | | | | | | | | | | |
| Vent (km/h) | 70 | 70 | 50 | 40 | 30 | 40 | 40 | 50 | 50 | 30 | 20 | 15 | 25 | 20 | 10 | 15 | 15 | 30 | 50 | 40 | 40 | 30 | 30 | 20 | 10 | 10 | 5 | 10 |
| à 2500m | | | | | | | | | | | | | | | | | | | | | | | | | | | | |
| Vent (km/h) | 40 | 35 | 35 | 20 | 20 | 20 | 30 | 30 | 20 | 20 | 15 | 5 | 15 | 15 | 5 | 10 | 10 | 20 | 30 | 25 | 20 | 20 | 15 | 10 | 10 | 10 | 5 | 10 |
| à 2000m | | | | | | | | | | | | | | | | | | | | | | | | | | | | |

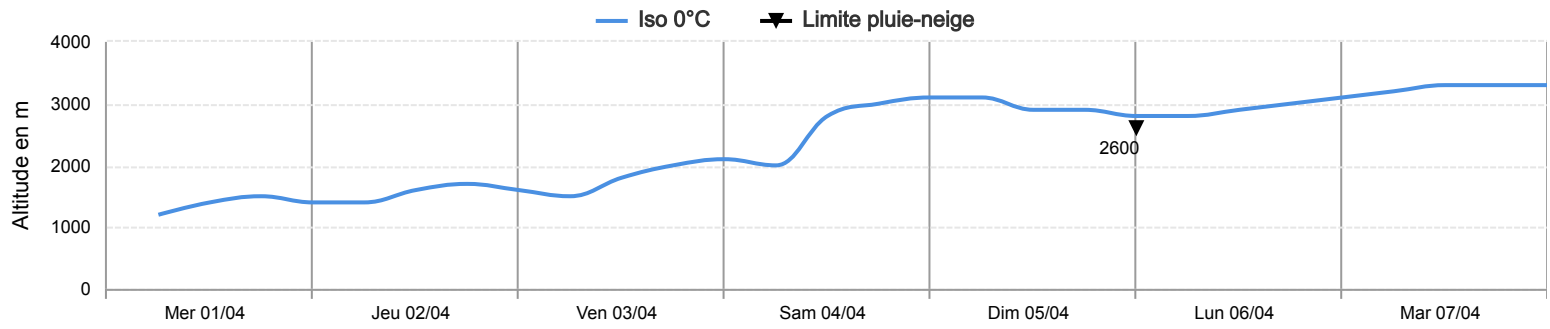


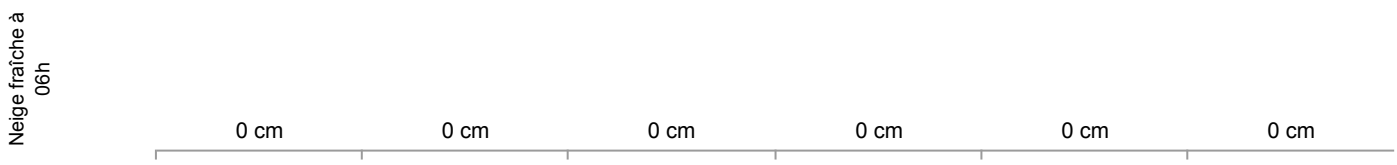


| Risque d'avalanche | mer. 01/04 | jeu. 02/04 | ven. 03/04 | sam. 04/04 | dim. 05/04 | lun. 06/04 | mar. 07/04 |
|---|---|---|---|---|---|---|---|
| | 3 | 2 | 2 | 2 | 2 | 2 | 2 |

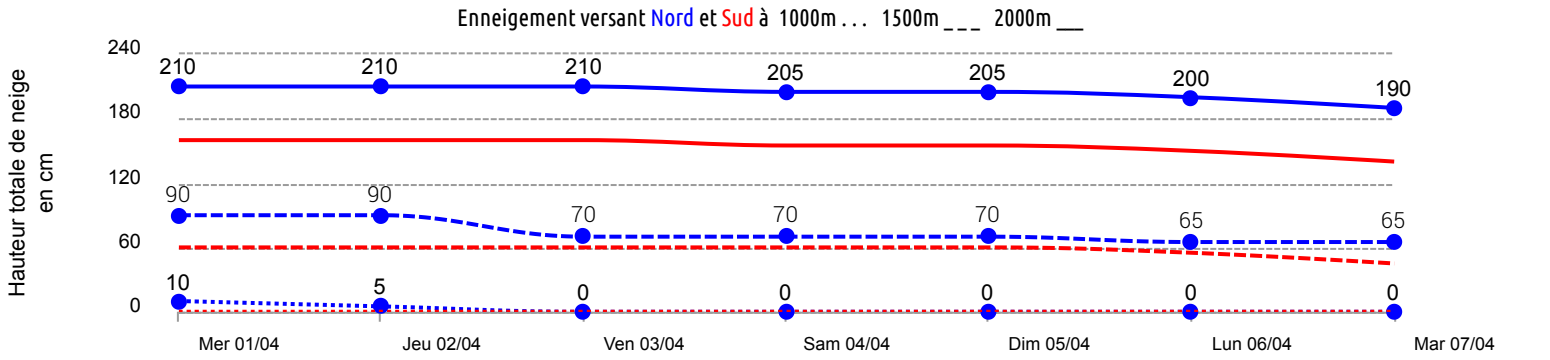


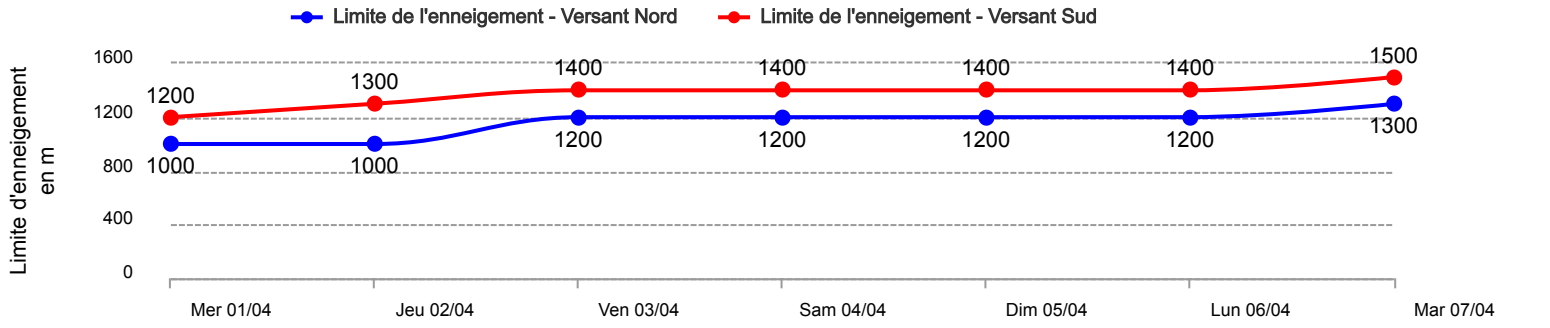


Pour consulter la vigilance en cours, veuillez vous rendre sur le site https://vigilance.meteofrance.fr/fr


**Météo-France - 73 avenue de Paris, 94165 Saint-Mandé cedex - Contact : contact@meteo.fr**


Rédigé par Météo-France avec la contribution des observateurs du réseau nivo-météorologiques. Partenariat : ANMSM (Maires de Stations de Montagne), DSF (Domaines Skiables de France), ADSP (Directeurs de Pistes et de la Sécurité des Stations de Sports d'Hiver) et autres acteurs de la montagne.


Bulletin neige & avalanches par téléphone au
0 892 68 10 20 Service 0,35 € / min + prix appel