RÉPUBLIQUE FRANÇAISE
Liberté Égalité Fraternité

METEO FRANCE
À VOS CÔTÉS, DANS UN CLIMAT QUI CHANGE

Bulletin d'estimation du risque d'avalanche
(valable en dehors des pistes balisées et ouvertes)
MASSIF : Capcir Puymorens

Rédigé le mardi 7 avril 2026 à 16h

Estimation des risques pour le : MERCREDI 08 AVRIL

PROGRESSION DE L'HUMIDIFICATION DU MANTEAU PLUS EN ALTITUDE ; QUELQUES STRUCTURES DE PLAQUES ENCORE PRÉSENTES EN VERSANTS FROIDS D'ALTITUDE.

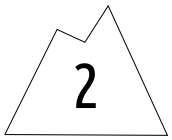

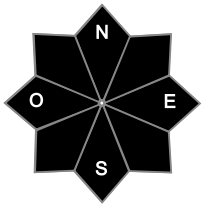

Indice de risque limité.

Départs spontanés : Reprise de l'activité en neige humide au fil de l'ensoleillement

Déclenchements provoqués : En versants froids d'altitude, de moins en moins probables

Indices de risque : 5 très fort - 4 fort - 3 marqué - 2 limité - 1 faible -- En noir : les pentes les plus dangereuses

Stabilité du manteau neigeux

Situation avalancheuse typique : neige humide couche fragile persistante

Départs spontanés :
- Départs ponctuels en neige humide de taille petite à moyenne au cours de la journée et de l'ensoleillement dans presque toutes les orientations et jusqu'en altitude. Seules les faces nord raides de haute montagne sont susceptibles encore d'y échapper. Ces départs ponctuels pourront favoriser, en cascade, des départs linéaires de plus grande taille notamment dans les versants nord-est à sud, plus chargés par les récentes chutes de neige.
- Sous 2000m, avalanches de fond de taille petite à moyenne possibles dans les pentes herbeuses ou dalles rocheuses lisses récemment recouvertes par les chutes de neige récentes.

Déclenchements provoqués :
- Avalanches de plaques encore éventuellement déclenchables au passage d'un pratiquant, plutôt au-dessus de 2300/2400 m, dans les versants nord-ouest, nord et nord-est. Des structures de plaques peuvent subsister avec des couches fragiles persistantes encore présentes dans le manteau neigeux. Bien qu'en cours de stabilisation, elles peuvent occasionner des avalanches moyennes, voire grandes dans les zones de forte accumulation. *Observables : Avalanches récentes, aspect venté de la surface et accumulations locales.*
- Ailleurs, un pratiquant peut provoquer un départ ponctuel en surface dans la neige humide en coupant une pente raide déjà bien humidifiée.

Autre : Corniches volumineuses proches des crêtes.

Qualité de la neige

Enneigement :
L'enneigement est excellent pour la saison, parmi les meilleurs de ces 30 dernières années avec les derniers apports de la semaine passée. Les quantités remarquables côtoient des crêtes et sommets exposés au vent d'ouest à nord-ouest souvent assez dégarnis. Même si la neige est visible dès 1500/1600 m dans certains secteurs ombragés et en fond de vallée, on chausse plutôt à partir de 1600/1700 m en nord voire plus haut en Sud sur une couche de neige rapidement épaisse.

Qualité de la neige :
Mercredi matin, regel nocturne peu efficace et peu portant sous 1800 m, plus dur et portant au-dessus. On trouve de la neige froide et parfois poudreuse dans de rares combes d'altitude abritées du vent plutôt en nord à nord-est. Là où le vent a soufflé, la neige est plus dure et tassée.
En journée, reprise de l'humidification pratiquement jusqu'en haut des massifs sauf dans quelques versants bien ombragés en Nord. Neige humide et gorgée d'eau au soleil au fil de l'ensoleillement, ainsi qu'en versants nord sous 2400m environ.

Aperçu météo pour le mercredi 08 avril

	nuit	matin	après-midi	soir

Beau temps printanier avec de la douceur et du vent de sud à sud-ouest en montagne.

Pluie-Neige				
Iso 0 °C	3 500 m	3 300 m	3 300 m	3 300 m
Vent 2000 m	↗ 20 km/h	↗ 25 km/h	↗ 20 km/h	↗ 10 km/h
Vent 3000 m	↗ 30 km/h	↗ 35 km/h	↗ 35 km/h	→ 20 km/h

Pour consulter la vigilance en cours, veuillez vous rendre sur le site https://vigilance.meteofrance.fr/fr

Météo-France - 73 avenue de Paris, 94165 Saint-Mandé cedex - Contact : contact@meteo.fr

Rédigé par Météo-France avec la contribution des observateurs du réseau nivo-météorologiques. Partenariat : ANMSM (Maires de Stations de Montagne), DSF (Domaines Skiables de France), ADSP (Directeurs de Pistes et de la Sécurité des Stations de Sports d'Hiver) et autres acteurs de la montagne.

Bulletin neige & avalanches par téléphone au
0 892 68 10 20 Service 0,35 € / min + prix appel

Bulletin d'estimation du risque d'avalanche

(valable en dehors des pistes balisées et ouvertes)

MASSIF : Capcir Puymorens

Rédigé le mardi 7 avril 2026 à 16h

Épaisseur de neige hors-piste

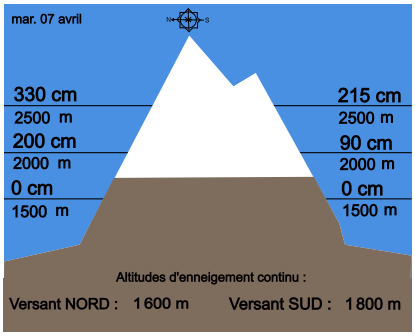

Précipitations à 1800 m

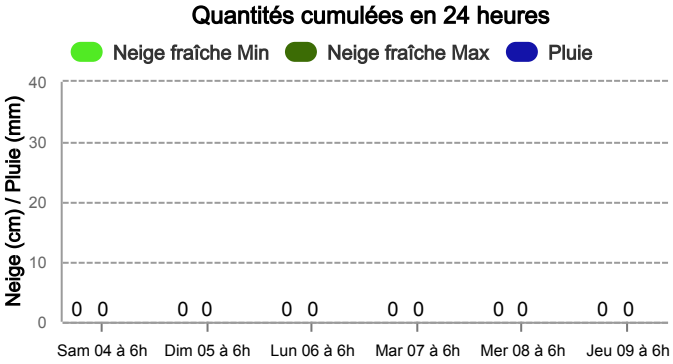

Tendance du jeudi 09 avril

Indice de risque limité

Peu d'évolution du risque avalancheux pour jeudi.

Pour consulter la vigilance en cours, veuillez vous rendre sur le site https://vigilance.meteofrance.fr/fr

Météo-France - 73 avenue de Paris, 94165 Saint-Mandé cedex - Contact : contact@meteo.fr

Rédigé par Météo-France avec la contribution des observateurs du réseau nivo-météorologiques. Partenariat : ANMSM (Maires de Stations de Montagne), DSF (Domaines Skiables de France), ADSP (Directeurs de Pistes et de la Sécurité des Stations de Sports d'Hiver) et autres acteurs de la montagne.

Bulletin neige & avalanches par téléphone au

0 892 68 10 20 Service 0,35 € / min + prix appel

RÉPUBLIQUE FRANÇAISE
Liberté Égalité Fraternité

METEO FRANCE
À VOS CÔTÉS, DANS UN CLIMAT QUI CHANGE

Bulletin d'estimation du risque d'avalanche

(valable en dehors des pistes balisées et ouvertes)

MASSIF : Capcir Puymorens

Rédigé le mardi 7 avril 2026 à 16h

Conditions nivo-météo des 7 derniers jours

	mer. 01/04				jeu. 02/04				ven. 03/04				sam. 04/04				dim. 05/04				lun. 06/04				mar. 07/04			
	03h	09h	15h	21h	03h	09h	15h	21h	03h	09h	15h	21h	03h	09h	15h	21h	03h	09h	15h	21h	03h	09h	15h	21h	03h	09h	15h	21h
Météo																												
Vent (km/h)	90	85	90	95	90	90	95	85	75	70	50	45	40	35	25	20	15	10	15	15	15	20	35	30	30	25	20	20
à 3000m																												
Vent (km/h)	80	75	85	85	75	75	80	75	60	55	40	35	20	15	15	15	10	5	10	10	10	15	25	20	20	15	15	10
à 2000m																												

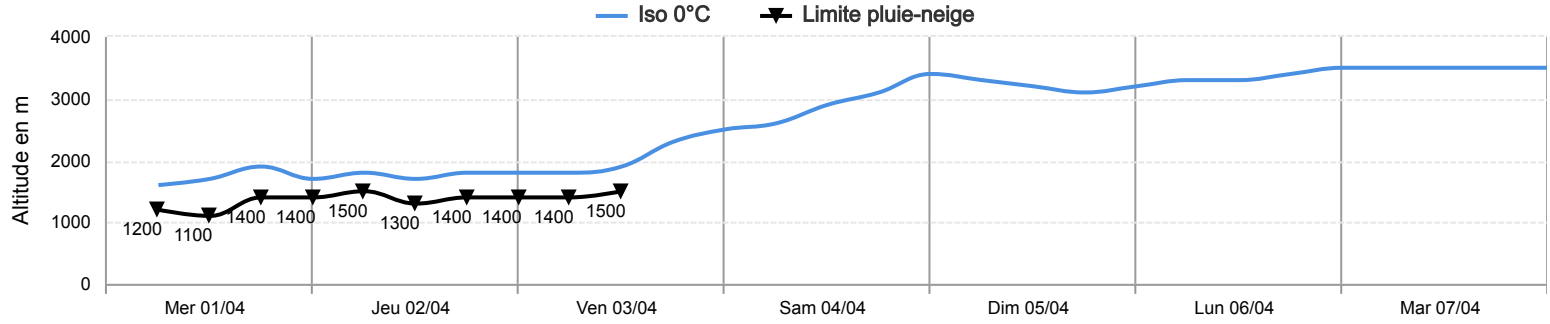

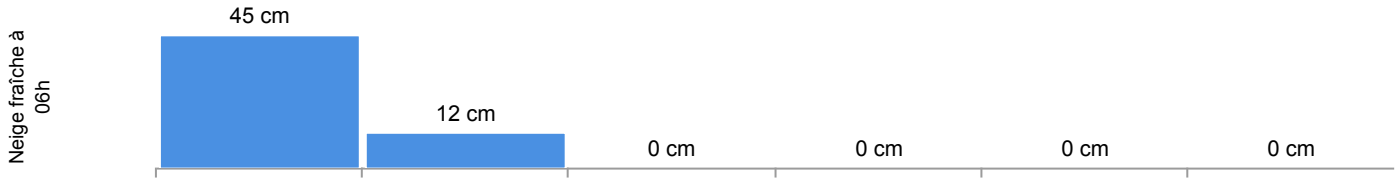

Risque d'avalanche	mer. 01/04	jeu. 02/04	ven. 03/04	sam. 04/04	dim. 05/04	lun. 06/04	mar. 07/04
	3	4	4	3	2	2	2

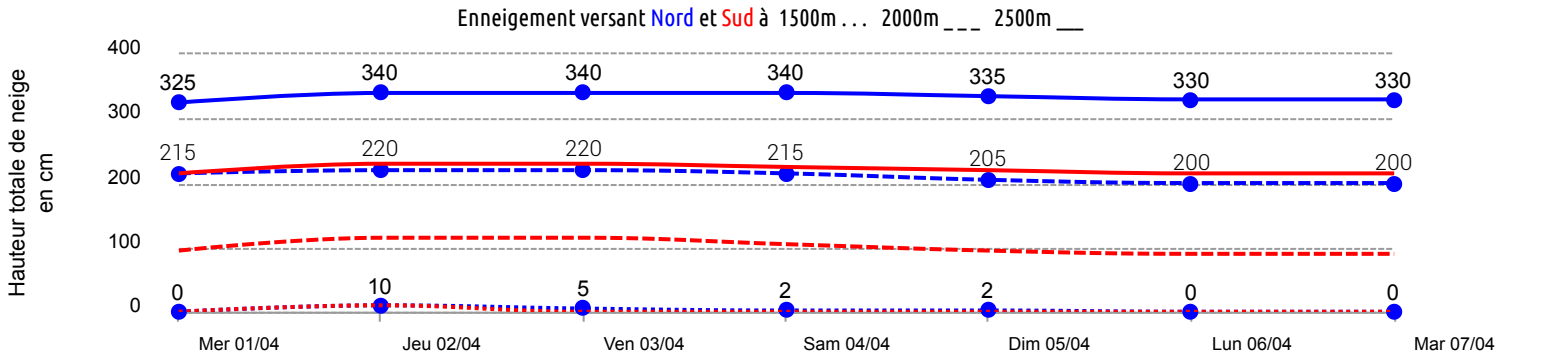

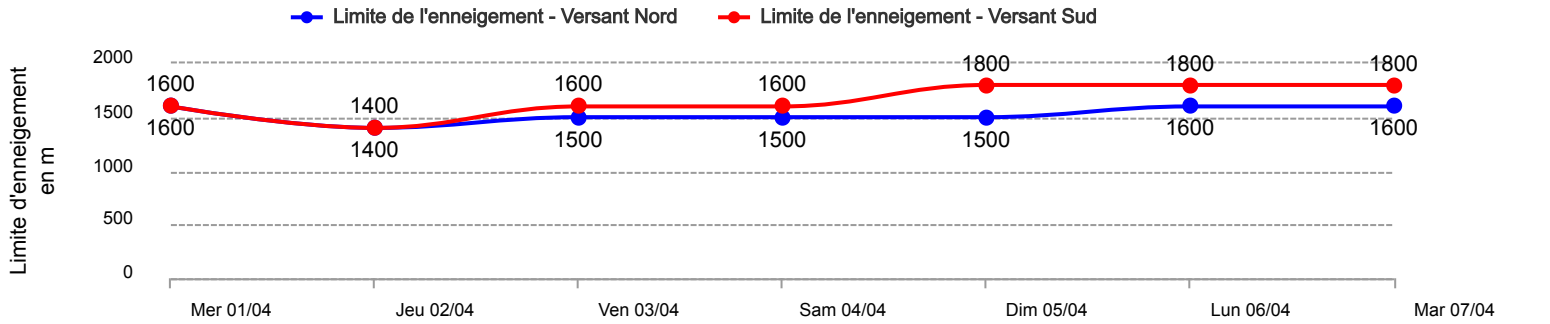

Pour consulter la vigilance en cours, veuillez vous rendre sur le site https://vigilance.meteofrance.fr/fr

Météo-France - 73 avenue de Paris, 94165 Saint-Mandé cedex - Contact : contact@meteo.fr

Rédigé par Météo-France avec la contribution des observateurs du réseau nivo-météorologiques. Partenariat : ANMSM (Maires de Stations de Montagne), DSF (Domaines Skiables de France), ADSP (Directeurs de Pistes et de la Sécurité des Stations de Sports d'Hiver) et autres acteurs de la montagne.

Bulletin neige & avalanches par téléphone au
0 892 68 10 20 Service 0,35 € / min + prix appel