Bulletin d'estimation du risque d'avalanche

(valable en dehors des pistes balisées et ouvertes)

MASSIF : Cerdagne Canigou

Rédigé le mardi 7 avril 2026 à 16h

Estimation des risques pour le : MERCREDI 08 AVRIL

PROGRESSION DE L'HUMIDIFICATION EN ALTITUDE; PLAQUES ENCORE PRÉSENTES EN VERSANTS FROIDS D'ALTITUDE

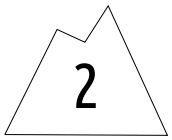

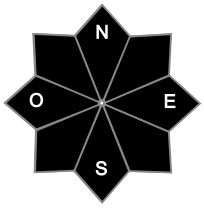

Indice de risque limité.

Départs spontanés : En neige humide au fil de l'ensoleillement

Déclenchements provoqués : En versants froids d'altitude, de moins en moins probables

Indices de risque : 5 très fort - 4 fort - 3 marqué - 2 limité - 1 faible -- En noir : les pentes les plus dangereuses

Stabilité du manteau neigeux

Situation avalancheuse typique : neige humide couche fragile persistante

Départs spontanés :

- Départs ponctuels en neige humide de taille petite à moyenne au cours de la journée et de l'ensoleillement dans presque toutes les orientations et jusqu'en altitude. Seules les faces nord raides de haute montagne sont susceptibles encore d'y échapper. Ces départs ponctuels pourront favoriser, en cascade, des départs linéaires de plus grande taille notamment dans les versants nord-est à sud, plus chargés par les chutes de neige ventées de la semaine passée.
- En dessous de 2000m, des avalanches de fond de taille petite à moyenne sont possibles dans les pentes herbeuses ou sur des dalles rocheuses lisses. *Observables : fissures, reptations récentes.*

Déclenchements provoqués :

- Avalanches de plaques encore éventuellement déclenchables au passage d'un pratiquant, plutôt au-dessus de 2400 m, dans les versants nord-ouest, nord et nord-est. Des structures de plaques peuvent subsister avec des couches fragiles persistantes encore présentes dans le manteau neigeux. Bien qu'en cours de stabilisation, elles peuvent occasionner des avalanches moyennes, voire grandes dans les zones de forte accumulation. *Observables : Avalanches récentes, aspect venté de la surface et accumulations locales.*
- Ailleurs, un pratiquant peut provoquer un départ ponctuel en surface dans la neige humide en coupant une pente raide déjà bien humidifiée.

Autre : Corniches volumineuses proches des crêtes.

Qualité de la neige

Enneigement :

L'enneigement est excellent sur le massif, parmi les meilleurs de ces 30 dernières années. Des hauteurs de neige conséquentes voire remarquables en altitude côtoient des crêtes et sommets exposés au vent d'ouest à nord-ouest souvent assez dégarnis. On trouve de la neige dès 1600 m dans des vallons ombragés, on chausse plutôt vers 1600/1700 m en Nord et plutôt 1800/2000 m en Sud sur une couche devenant rapidement plus épaisse.

Qualité de la neige :

Mercredi matin, regel efficace et portant dès 1800/2000m, plutôt mauvais plus bas et dans la forêt. Reprise de l'humidification en journée pratiquement jusqu'en haut des massifs avec une couche profonde de neige humide et gorgée d'eau au soleil dans les versants Est à Ouest en passant par le Sud, au fil de l'ensoleillement, et en versants nord en dessous de 2400/2500 m environ. Il peut encore subsister de la neige plus légère et poudreuse dans de rares combes d'altitude ombragées.

Aperçu météo pour le mercredi 08 avril

	nuit	matin	après-midi	soir

Belle journée douce et ensoleillée au programme. Vent de sud à sud-ouest en montagne.

Pluie-Neige				
Iso 0 °C	3 500 m	3 300 m	3 300 m	3 300 m
Vent 2000 m	20 km/h	25 km/h	25 km/h	20 km/h
Vent 3000 m	30 km/h	35 km/h	35 km/h	25 km/h

Épaisseur de neige hors-piste

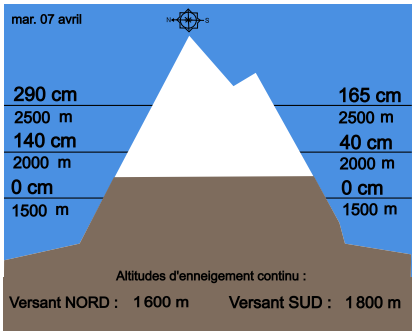

Précipitations à 1800 m

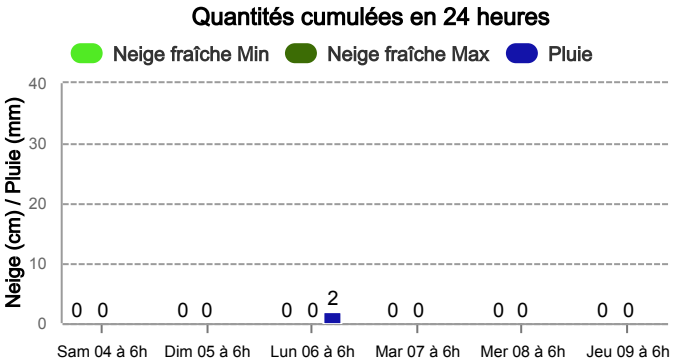

Tendance du jeudi 09 avril

Indice de risque limité

Stationnaire sans changement météorologique significatif.

Pour consulter la vigilance en cours, veuillez vous rendre sur le site https://vigilance.meteofrance.fr/fr

Météo-France - 73 avenue de Paris, 94165 Saint-Mandé cedex - Contact : contact@meteo.fr

Rédigé par Météo-France avec la contribution des observateurs du réseau nivo-météorologiques. Partenariat : ANMSM (Maires de Stations de Montagne), DSF (Domaines Skiables de France), ADSP (Directeurs de Pistes et de la Sécurité des Stations de Sports d'Hiver) et autres acteurs de la montagne.

Bulletin neige & avalanches par téléphone au 0 892 68 10 20 Service 0,35 € / min + prix appel

RÉPUBLIQUE FRANÇAISE
Liberté Égalité Fraternité

METEO FRANCE
À VOS CÔTÉS, DANS UN CLIMAT QUI CHANGE

Bulletin d'estimation du risque d'avalanche

(valable en dehors des pistes balisées et ouvertes)

MASSIF : Cerdagne Canigou

Rédigé le mardi 7 avril 2026 à 16h

Conditions nivo-météo des 7 derniers jours

	mer. 01/04				jeu. 02/04				ven. 03/04				sam. 04/04				dim. 05/04				lun. 06/04				mar. 07/04			
	03h	09h	15h	21h	03h	09h	15h	21h	03h	09h	15h	21h	03h	09h	15h	21h	03h	09h	15h	21h	03h	09h	15h	21h	03h	09h	15h	21h
Météo																												
Vent (km/h)	100	90	95	100	100	95	95	90	85	75	55	50	40	35	25	20	15	10	15	15	15	20	35	30	30	25	20	20
à 3000m																												
Vent (km/h)	70	70	75	80	70	65	70	70	60	55	40	35	20	15	15	15	10	5	10	10	10	15	25	20	20	15	15	10
à 2000m																												

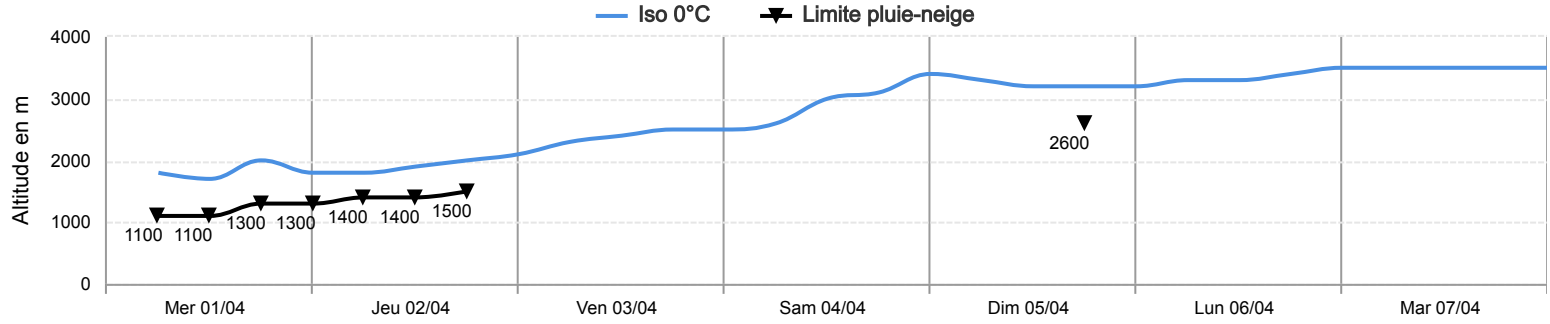

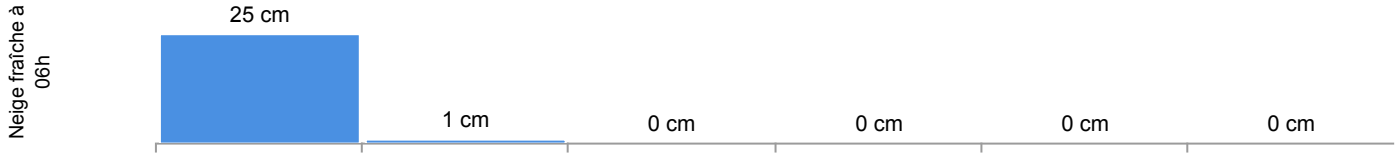

Risque d'avalanche	mer. 01/04	jeu. 02/04	ven. 03/04	sam. 04/04	dim. 05/04	lun. 06/04	mar. 07/04
	2	2	2	2	2	2	2

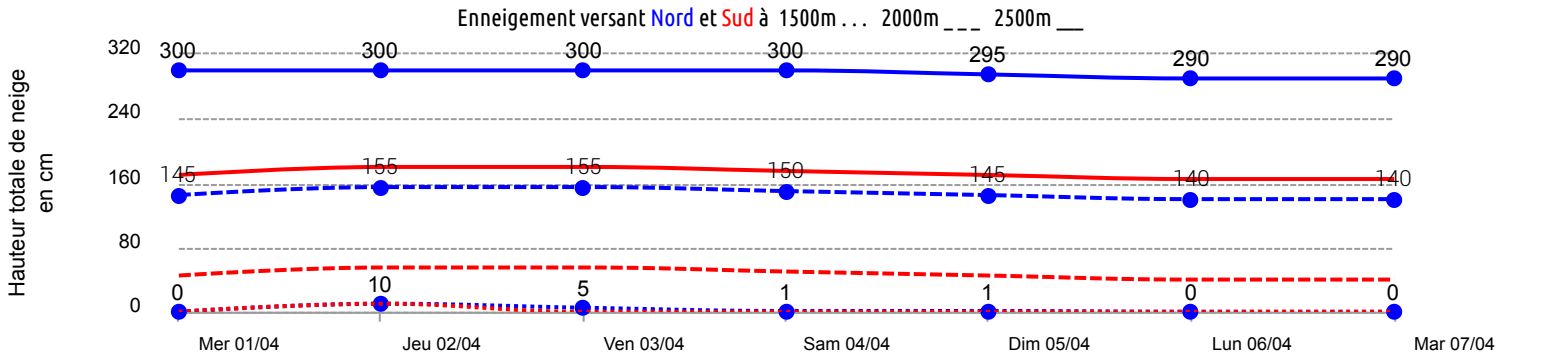

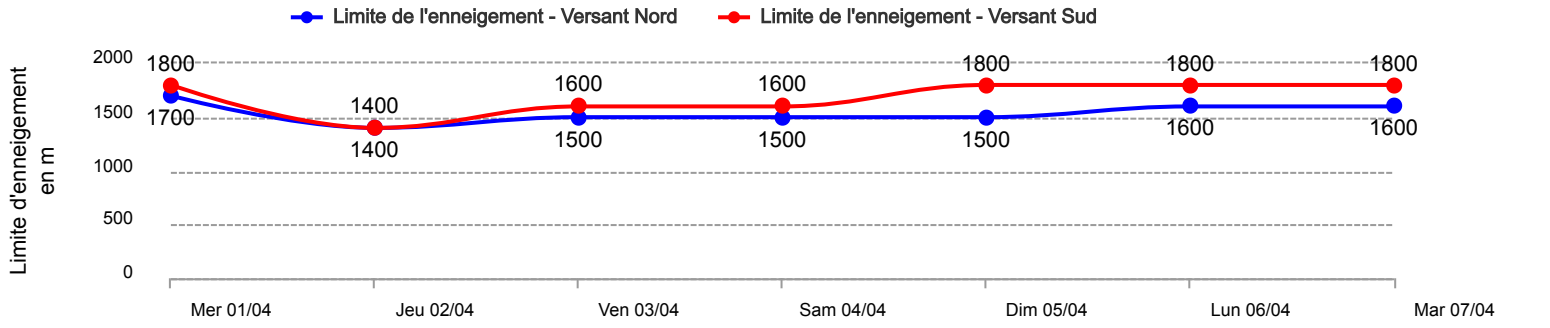

Pour consulter la vigilance en cours, veuillez vous rendre sur le site https://vigilance.meteofrance.fr/fr

Météo-France - 73 avenue de Paris, 94165 Saint-Mandé cedex - Contact : contact@meteo.fr

Rédigé par Météo-France avec la contribution des observateurs du réseau nivo-météorologiques. Partenariat : ANMSM (Maires de Stations de Montagne), DSF (Domaines Skiables de France), ADSP (Directeurs de Pistes et de la Sécurité des Stations de Sports d'Hiver) et autres acteurs de la montagne.

Bulletin neige & avalanches par téléphone au

0 892 68 10 20 Service 0,35 € / min + prix appel