RÉPUBLIQUE FRANÇAISE
Liberté Égalité Fraternité

METEO FRANCE
À VOS CÔTÉS, DANS UN CLIMAT QUI CHANGE

Bulletin d'estimation du risque d'avalanche
(valable en dehors des pistes balisées et ouvertes)

MASSIF : Chablais

Rédigé le mardi 7 avril 2026 à 16h

Estimation des risques pour le : MERCREDI 08 AVRIL

LE PRINTEMPS S'INSTALLE

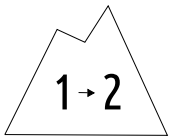

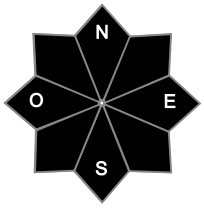

Indice de risque faible évoluant en limité.

Départs spontanés : avalanches de neige humide

Déclenchements provoqués : avalanches de neige humide

Indices de risque : 5 très fort - 4 fort - 3 marqué - 2 limité - 1 faible -- En noir : les pentes les plus dangereuses

Stabilité du manteau neigeux

Situation avalancheuse typique : neige humide avalanches de fond

Déclenchements provoqués :
* **avalanches de neige humide**, de plus en **plus nombreuses au fil du réchauffement** et du rayonnement solaire. En toutes orientations et altitudes. Taille 1 à 2 (petite à moyenne) et rarement 3 (grande). Dans la tranche **2200/2800 m**, de petits départs ponctuels peuvent **déclencher, en cascade, une plaque** de fond ou seulement en surface.
* quelques **plaques de fond** dans les zones herbeuses ou les dalles rocheuses, à toute heure du jour ou de la nuit. En dessous de 2100 m en nord et 2500 m en sud. Taille 2 (moyenne).

Départs spontanés :
* **avalanches de neige humide** en sud et en dessous de 2500 m en nord. Facile à déclencher au soleil. Départ ponctuel sous les skis, pouvant parfois déclencher, en cascade, une petite plaque. Taille 1 à 2 (petite à moyenne). Causé par le réchauffement et le rayonnement solaire.

Qualité de la neige

Enneigement :
Pour la saison, l'enneigement est correct.
On peut chausser les skis au-dessus de 1600 m en sud et 1300/1400 m en nord.

Qualité de la neige ce mercredi matin :
Bon regel nocturne. Manteau neigeux printanier sous 2600 m en sud et 2000 m en nord.
L'humidification de surface a progressé à toutes altitudes en sud et jusqu'à 2700 m en nord.
Au-dessus de 2700 m en versant nord, il reste de la neige froide et soufflée.
Corniches fragilisées par le redoux.

Aperçu météo pour le mercredi 08 avril

nuit	matin	après-midi	soir

Journée ensoleillée. Températures maximales : 12°C à 2000 m et 16°C à 1500 m.

Pluie-Neige				
Iso 0 °C	3 300 m	3 400 m	3 400 m	3 400 m
Vent 2000 m	20 km/h	25 km/h	5 km/h	5 km/h
Vent 2500 m	20 km/h	25 km/h	10 km/h	5 km/h

Épaisseur de neige hors-piste

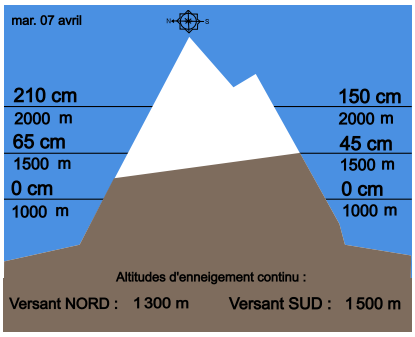

Précipitations à 1800 m

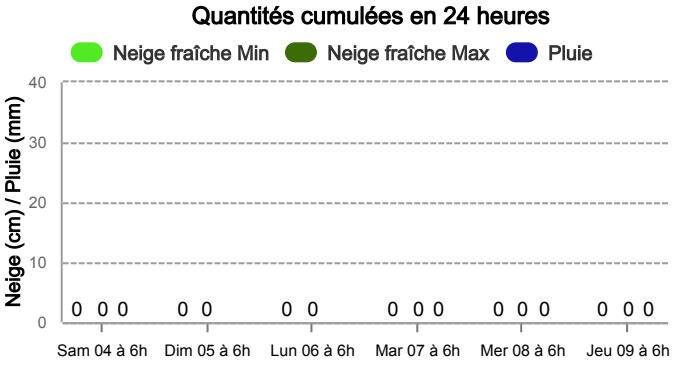

Tendance du jeudi 09 avril

Indice de risque limité

Jeudi : journée ensoleillée, vent calme et isotherme 0°C en baisse vers 3000 m.
⇒ risque stable, poursuite de l'humidification du manteau neigeux.

Pour consulter la vigilance en cours, veuillez vous rendre sur le site https://vigilance.meteofrance.fr/fr

Météo-France - 73 avenue de Paris, 94165 Saint-Mandé cedex - Contact : contact@meteo.fr

Rédigé par Météo-France avec la contribution des observateurs du réseau nivo-météorologiques. Partenariat : ANMSM (Maires de Stations de Montagne), DSF (Domaines Skiables de France), ADSP (Directeurs de Pistes et de la Sécurité des Stations de Sports d'Hiver) et autres acteurs de la montagne.

Bulletin neige & avalanches par téléphone au
0 892 68 10 20 Service 0,35 € / min + prix appel

RÉPUBLIQUE FRANÇAISE
Liberté Égalité Fraternité

METEO FRANCE
À VOS CÔTÉS, DANS UN CLIMAT QUI CHANGE

Bulletin d'estimation du risque d'avalanche

(valable en dehors des pistes balisées et ouvertes)

MASSIF : Chablais

Rédigé le mardi 7 avril 2026 à 16h

Conditions nivo-météo des 7 derniers jours

	mer. 01/04				jeu. 02/04				ven. 03/04				sam. 04/04				dim. 05/04				lun. 06/04				mar. 07/04			
	03h	09h	15h	21h	03h	09h	15h	21h	03h	09h	15h	21h	03h	09h	15h	21h	03h	09h	15h	21h	03h	09h	15h	21h	03h	09h	15h	21h
Météo																												
Vent (km/h)	60	50	40	30	30	40	50	50	40	20	15	15	20	15	5	10	25	30	50	40	40	30	30	20	15	10	5	10
à 2500m																												
Vent (km/h)	35	35	30	10	10	20	30	30	20	15	10	5	10	10	0	5	15	20	35	25	25	20	15	10	10	10	5	5
à 2000m																												

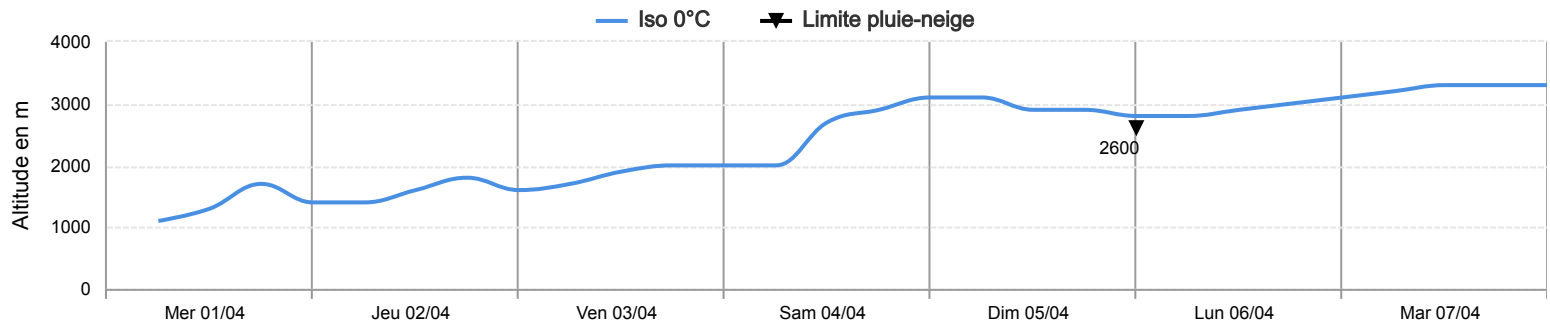

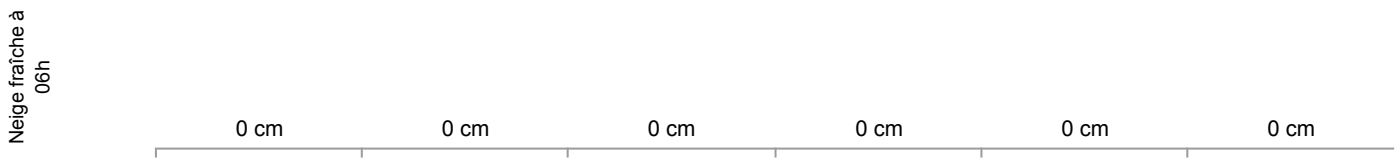

Risque d'avalanche	mer. 01/04	jeu. 02/04	ven. 03/04	sam. 04/04	dim. 05/04	lun. 06/04	mar. 07/04
	3	2	2	2	2	2	2

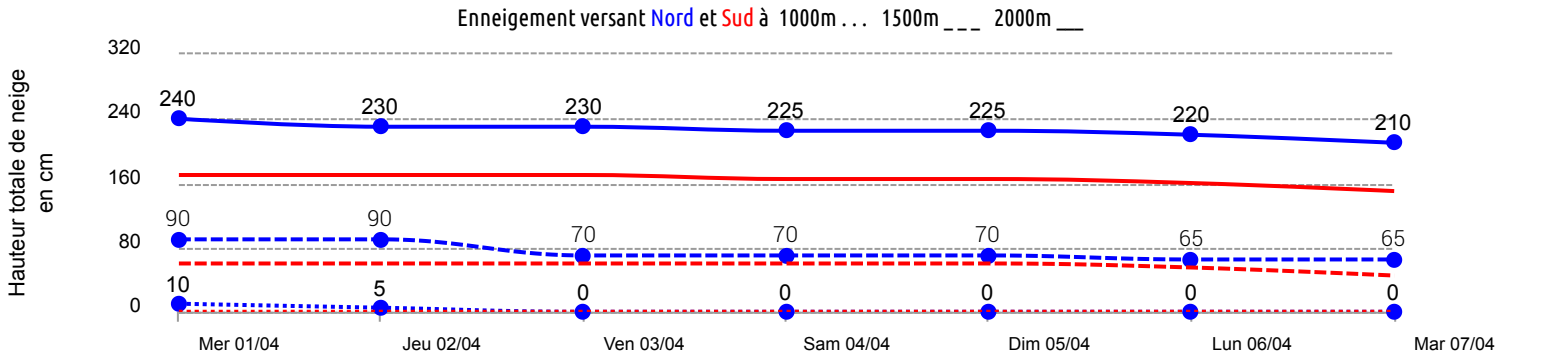

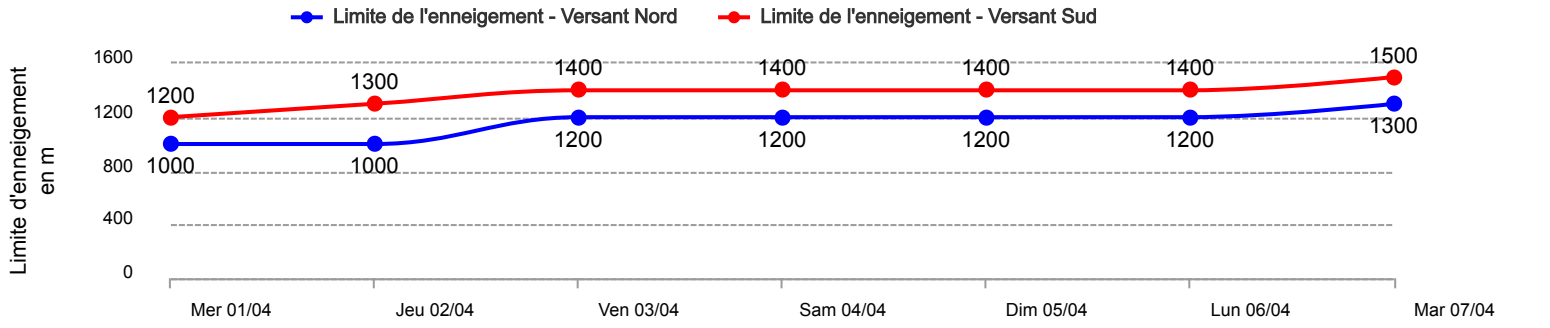

Pour consulter la vigilance en cours, veuillez vous rendre sur le site https://vigilance.meteofrance.fr/fr

Météo-France - 73 avenue de Paris, 94165 Saint-Mandé cedex - Contact : contact@meteo.fr

Rédigé par Météo-France avec la contribution des observateurs du réseau nivo-météorologiques. Partenariat : ANMSM (Maires de Stations de Montagne), DSF (Domaines Skiables de France), ADSP (Directeurs de Pistes et de la Sécurité des Stations de Sports d'Hiver) et autres acteurs de la montagne.

Bulletin neige & avalanches par téléphone au
0 892 68 10 20
Service 0,35 € / min + prix appel