Bulletin d'estimation du risque d'avalanche

(valable en dehors des pistes balisées et ouvertes)

MASSIF : Cinto Rotondo

Rédigé le mardi 7 avril 2026 à 16h

Estimation des risques pour le : MERCREDI 08 AVRIL

DÉPARTS EN NEIGE HUMIDE EN JOURNÉE

2

1 → 2

N O E S

Indice de risque faible évoluant en limité.

Départs spontanés : Coulées et avalanches de neige humide

Déclenchements provoqués : Très rares plaques à vent en altitude

Indices de risque : 5 très fort - 4 fort - 3 marqué - 2 limité - 1 faible -- En noir : les pentes les plus dangereuses

Stabilité du manteau neigeux

Situation avalancheuse typique : neige humide

Départs spontanés : Des coulées et avalanches de neige humide sont attendues en journée, surtout dans les pentes raides bien ensoleillées, au fil de la course du soleil. En altitude, l'humidification gagnant en profondeur dans la neige récente, des avalanches de taille moyenne, rarement une grande, peuvent se produire, y compris dans les couloirs nord toujours bien chargés.

Déclenchements provoqués : Un skieur coupant une pente raide peut déclencher une coulée de neige humide, à plus forte raison aux heures les plus chaudes de la journée. De fines plaques à vent peuvent également persister, dans les pentes ombragées en haute altitude, mais elles restent difficiles à solliciter.

Autres : Présence de corniches, susceptibles de rompre à cause des conditions printanières. Persistance de surfaces dures et glacées, pouvant être recouvertes de quelques centimètres de neige récente humide.

Qualité de la neige

Qualification de l'enneigement : L'enneigement est excellent pour la saison. Sur la Maniccia, à 2400 m d'altitude dans le massif du Rotondo, on relève 3m de hauteur de neige totale.

Limite d'enneigement skiable : 1600m.

État de la neige : Évolution progressive vers une neige de printemps en toutes orientations. En Nord en haute altitude, il reste quelques surfaces de neige sèche, souvent dure, dans les rares pentes raides qui restent ombragées. Ailleurs, l'humidification gagne en profondeur tandis que le regel nocturne est moins efficace. Toutefois, les surfaces dures peuvent être fréquentes le matin en altitude. Dans les orientations Sud, le manteau neigeux est généralement humidifié sur toute son épaisseur, au moins jusqu'à 2200 m. En moyenne montagne, la croûte de regel est inexistante le matin, la neige devient molle voire pourrie l'après-midi.

Aperçu météo pour le mercredi 08 avril

	nuit	matin	après-midi	soir
Temps ensoleillé et doux.				
Pluie-Neige				
Iso 0 °C	3 200 m	3 200 m	3 300 m	3 300 m
Vent 1500 m	→ 15 km/h	↗ 10 km/h	↙ 10 km/h	↗ 10 km/h
Vent 3000 m	→ 15 km/h	↑ 10 km/h	→ 20 km/h	→ 15 km/h

Épaisseur de neige hors-piste

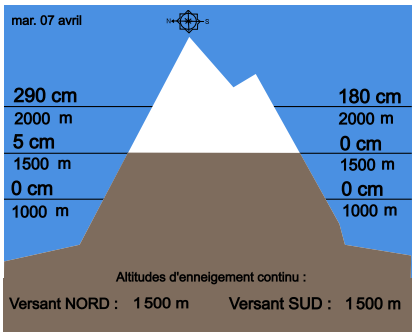

Précipitations à 1800 m

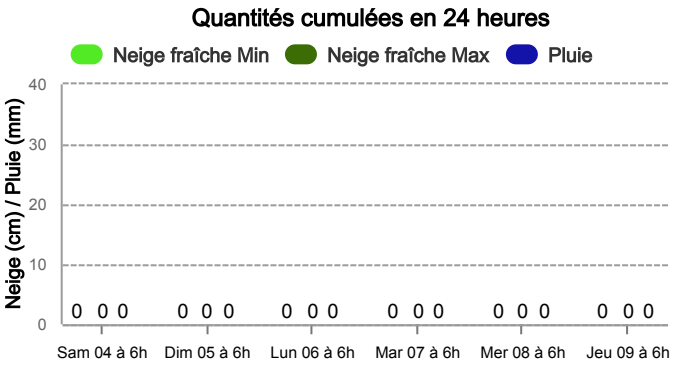

Tendance du jeudi 09 avril

2

Indice de risque limité

Maintien d'un risque limité. L'humidification du manteau neigeux se poursuit avec la douceur.

Pour consulter la vigilance en cours, veuillez vous rendre sur le site https://vigilance.meteofrance.fr/fr

Météo-France - 73 avenue de Paris, 94165 Saint-Mandé cedex - Contact : contact@meteo.fr

Rédigé par Météo-France avec la contribution des observateurs du réseau nivo-météorologiques. Partenariat : ANMSM (Maires de Stations de Montagne), DSF (Domaines Skiables de France), ADSP (Directeurs de Pistes et de la Sécurité des Stations de Sports d'Hiver) et autres acteurs de la montagne.

Bulletin neige & avalanches par téléphone au 0 892 68 10 20 Service 0,35 € / min + prix appel

RÉPUBLIQUE FRANÇAISE
Liberté Égalité Fraternité

METEO FRANCE
À VOS CÔTÉS, DANS UN CLIMAT QUI CHANGE

Bulletin d'estimation du risque d'avalanche

(valable en dehors des pistes balisées et ouvertes)

MASSIF : Cinto Rotondo

Rédigé le mardi 7 avril 2026 à 16h

Conditions nivo-météo des 7 derniers jours

	mer. 01/04				jeu. 02/04				ven. 03/04				sam. 04/04				dim. 05/04				lun. 06/04				mar. 07/04			
	03h	09h	15h	21h	03h	09h	15h	21h	03h	09h	15h	21h	03h	09h	15h	21h	03h	09h	15h	21h	03h	09h	15h	21h	03h	09h	15h	21h
Météo																												
Vent (km/h)	80	70	45	60	60	45	40	50	60	50	40	25	40	40	30	40	25	15	10	15	25	20	20	20	25	20	20	15
à 3000m																												
Vent (km/h)	95	100	50	55	50	40	40	35	35	30	25	15	10	15	15	15	15	5	10	10	20	15	15	20	15	15	20	10
à 1500m																												

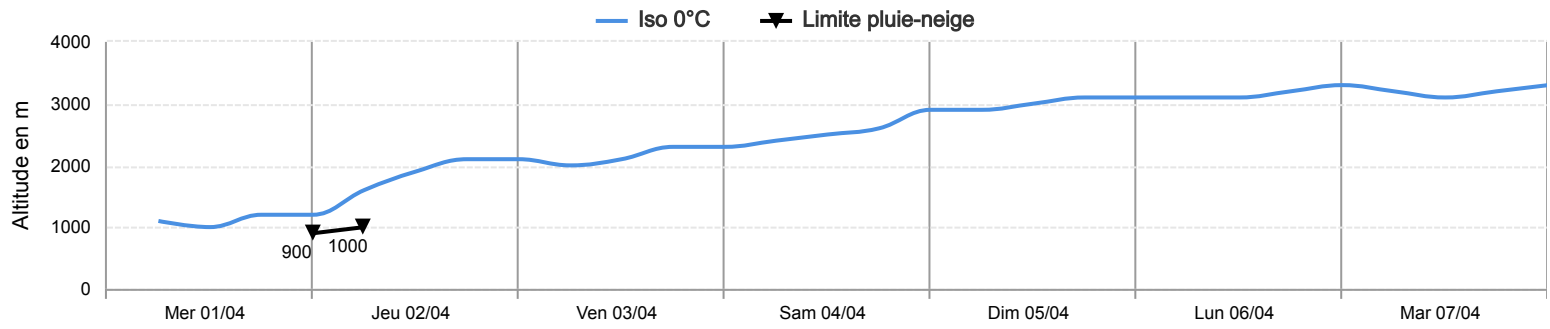

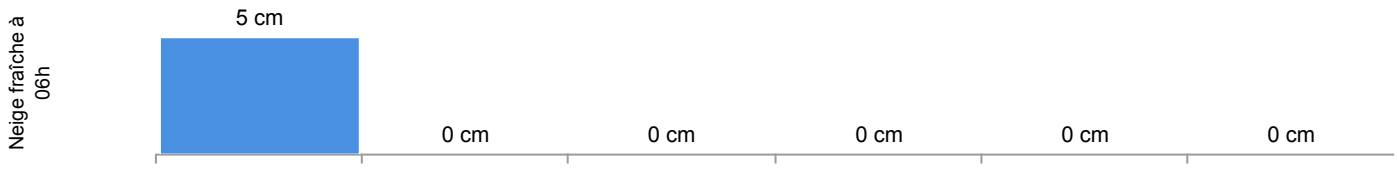

Risque d'avalanche	mer. 01/04	jeu. 02/04	ven. 03/04	sam. 04/04	dim. 05/04	lun. 06/04	mar. 07/04
	2	2	2	2	2	2	1

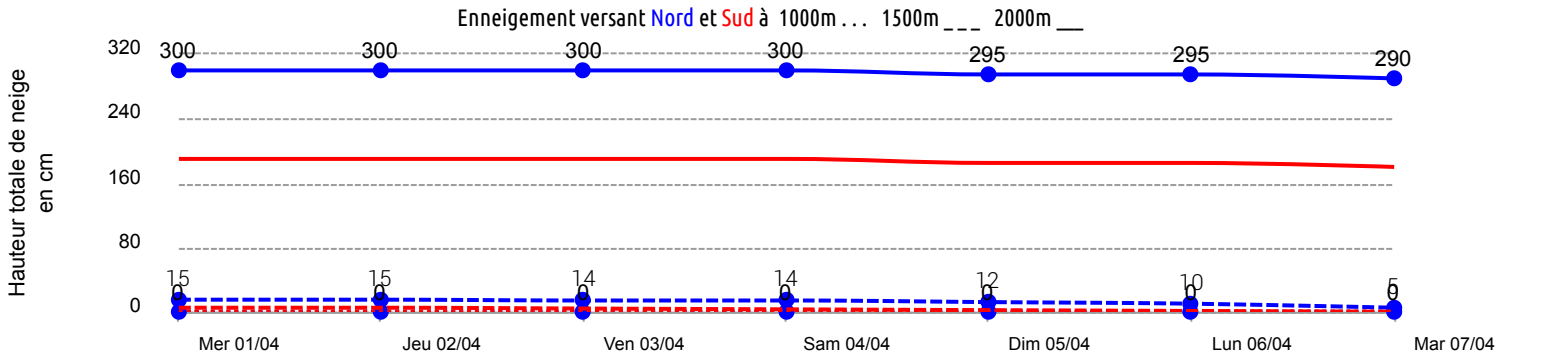

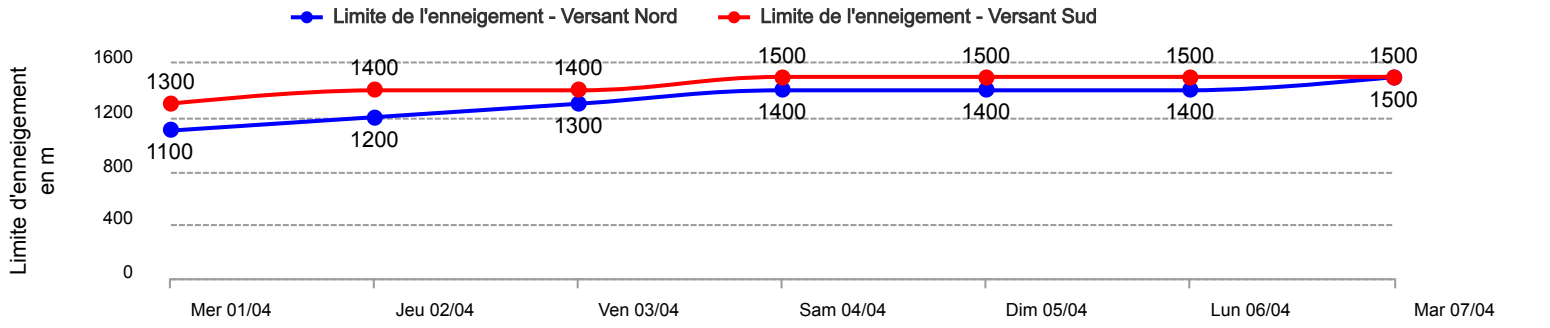

Pour consulter la vigilance en cours, veuillez vous rendre sur le site https://vigilance.meteofrance.fr/fr

Météo-France - 73 avenue de Paris, 94165 Saint-Mandé cedex - Contact : contact@meteo.fr

Rédigé par Météo-France avec la contribution des observateurs du réseau nivo-météorologiques. Partenariat : ANMSM (Maires de Stations de Montagne), DSF (Domaines Skiables de France), ADSP (Directeurs de Pistes et de la Sécurité des Stations de Sports d'Hiver) et autres acteurs de la montagne.

Bulletin neige & avalanches par téléphone au
0 892 68 10 20 Service 0,35 € / min + prix appel