Bulletin d'estimation du risque d'avalanche

(valable en dehors des pistes balisées et ouvertes)

MASSIF : Haute-Bigorre

Rédigé le mardi 7 avril 2026 à 16h

Estimation des risques pour le : MERCREDI 08 AVRIL

QUELQUES STRUCTURES DE PLAQUES DANS LES VERSANTS NORD D'ALTITUDE SE STABILISANT PROGRESSIVEMENT, HUMIDIFICATION AILLEURS.

2

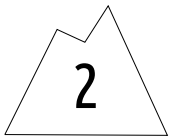

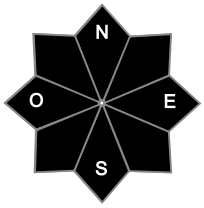

Indice de risque limité.

Départs spontanés : En neige humide au soleil, avalanches de fond possibles.

Déclenchements provoqués : Structures de plaques dans les versants Nord d'altitude se stabilisant progressivement, couche fragile persistante enfouie. En neige humide ailleurs.

Indices de risque : 5 très fort - 4 fort - 3 marqué - 2 limité - 1 faible -- En noir : les pentes les plus dangereuses

Stabilité du manteau neigeux

Situation avalancheuse typique : neige humide couche fragile persistante

Déclenchements provoqués :
- **Au-dessus de 2500 à 2600m**, dans les pentes raides des versants allant du Nord-Ouest vers le Nord-Est, quelques structures de plaques peuvent encore subsister, issues des dernières chutes de neige. Bien qu'en cours de stabilisation et parfois même durcies le matin, elles peuvent encore être déclenchées par un simple skieur en se ramollissant, sinon sollicitables dès la matinée. Elles peuvent reposer sur une couche fragile persistante enfouie plus difficile à déclencher. Des cassures linéaires petites à moyennes sont généralement attendues (taille 1 à 2), plus rarement des grandes (taille 3) dans les zones d'accumulation les plus importantes.
- **Partout ailleurs**, un simple skieur peut déclencher des départs ponctuels dans la neige humide et dans les pentes raides en tous versants. Des avalanches petites à moyennes (taille 1 à 2) sont attendues dès la matinée en est à sud-est, puis rapidement dans tous les autres versants au fil de la matinée et de l'ensoleillement, dans la douceur ambiante. Un bon regel matinal peut limiter l'activité avalancheuse tôt le matin, mais le risque sera bien présent dès la matinée, l'humidification se faisant rapidement.

Départs spontanés :
Des départs ponctuels sont attendus dans les pentes raides et en tous versants au fil de la journée et de l'ensoleillement. Ils sont peu importants le matin, avec un regel plus ou moins efficace, mais tendent à être plus nombreux ensuite avec l'humidification rapide. Des avalanches petites à moyennes (taille 1 à 2) sont généralement possibles, plus rarement des grandes (taille 3) en partant de zones d'accumulation importantes. Des avalanches de fond sont aussi possibles en pentes raides, en partant d'une accumulation encore présente sur le haut du massif, notamment près des fissures et des reptations récentes. Avalanches petites à moyennes possibles (taille 1 à 2), parfois grandes (taille 3).

Autres : Ponts de neige et corniches encore en place fragilisés au soleil.

Qualité de la neige

Enneigement : Encore bon pour la saison, débutant encore vers 1500 à 1600m en nord, 1700 à 1800m en sud. Ces limites remontent progressivement au fil de la journée avec l'ensoleillement et la douceur ambiante.

État de la neige : Neige de printemps en général dans une grande majorité des secteurs. La neige est plutôt bien regelée à dure le matin, ramollissant assez rapidement au soleil. Au-dessus de 2500 à 2600m, dans les versants allant du Nord-Ouest au Nord-Est, la neige est parfois légèrement croûtée en surface, s'humidifiant plus lentement. Sinon, la neige reste encore sèche, meuble et travaillée par le vent, s'humidifiant progressivement en journée et de plus en plus en profondeur dans la douceur. Partout ailleurs, la neige poursuit ensuite son humidification, elle est lourde à parfois gorgée d'eau.

Aperçu météo pour le mercredi 08 avril

	nuit	matin	après-midi	soir
Pluie-Neige				
Iso 0 °C	3 300 m	3 300 m	3 300 m	3 300 m
Vent 2000 m	↑ 20 km/h	↑ 15 km/h	↑ 15 km/h	↑ 10 km/h
Vent 3000 m	↑ 45 km/h	↖ 30 km/h	↖ 30 km/h	↑ 25 km/h

Temps sec et plutôt bien ensoleillé, quelques passages nuageux d'altitude. Développements de quelques nuages l'après-midi sans incidence. Douceur.

Épaisseur de neige hors-piste

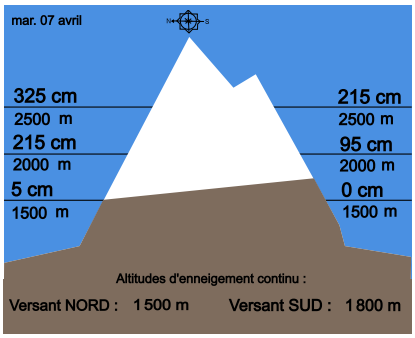

Précipitations à 1800 m

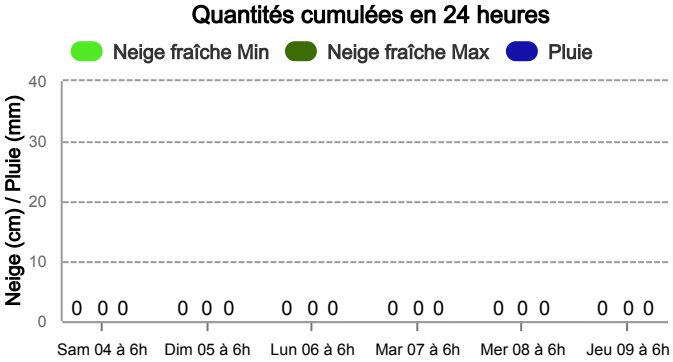

Tendance du jeudi 09 avril

2

Indice de risque limité

Risque stationnaire. Poursuite de l'humidification en profondeur du manteau neigeux avec la douceur ambiante, stabilisation progressive des plaques en altitude des versants allant du Nord-Ouest vers le Nord-Est.

Pour consulter la vigilance en cours, veuillez vous rendre sur le site https://vigilance.meteofrance.fr/fr

Météo-France - 73 avenue de Paris, 94165 Saint-Mandé cedex - Contact : contact@meteo.fr

Bulletin neige & avalanches par téléphone au 0 892 68 10 20 Service 0,35 € / min + prix appel

Rédigé par Météo-France avec la contribution des observateurs du réseau nivo-météorologiques. Partenariat : ANMSM (Maires de Stations de Montagne), DSF (Domaines Skiables de France), ADSP (Directeurs de Pistes et de la Sécurité des Stations de Sports d'Hiver) et autres acteurs de la montagne.

RÉPUBLIQUE FRANÇAISE
Liberté Égalité Fraternité

METEO FRANCE
À VOS CÔTÉS, DANS UN CLIMAT QUI CHANGE

Bulletin d'estimation du risque d'avalanche

(valable en dehors des pistes balisées et ouvertes)

MASSIF : Haute-Bigorre

Rédigé le mardi 7 avril 2026 à 16h

Conditions nivo-météo des 7 derniers jours

	mer. 01/04				jeu. 02/04				ven. 03/04				sam. 04/04				dim. 05/04				lun. 06/04				mar. 07/04			
	03h	09h	15h	21h	03h	09h	15h	21h	03h	09h	15h	21h	03h	09h	15h	21h	03h	09h	15h	21h	03h	09h	15h	21h	03h	09h	15h	21h
Météo																												
Vent (km/h)	75	80	90	90	85	90	80	75	60	50	25	20	15	25	25	30	30	20	20	20	15	25	35	40	45	40	30	45
à 3000m																												
Vent (km/h)	40	40	45	60	50	50	50	45	35	15	20	15	15	10	5	15	5	10	2	5	10	10	15	20	25	20	15	25
à 2000m																												

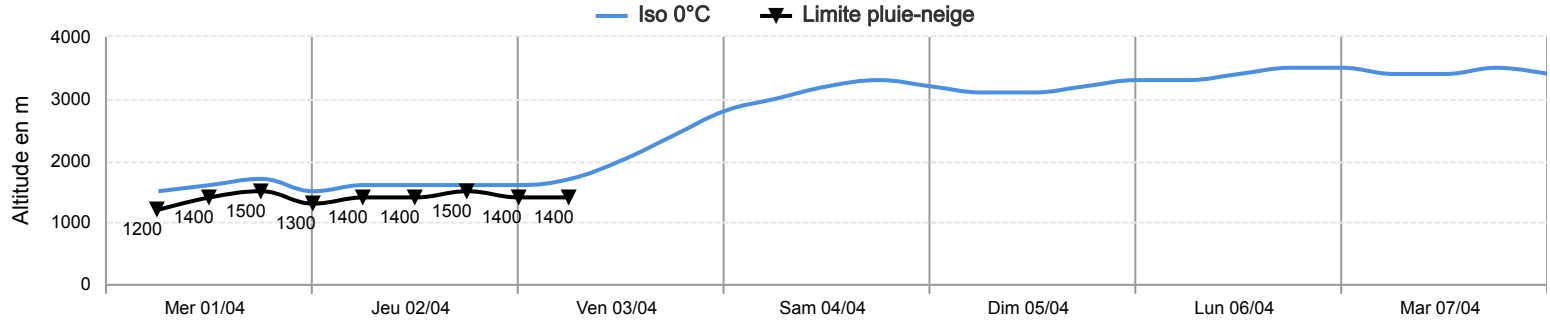

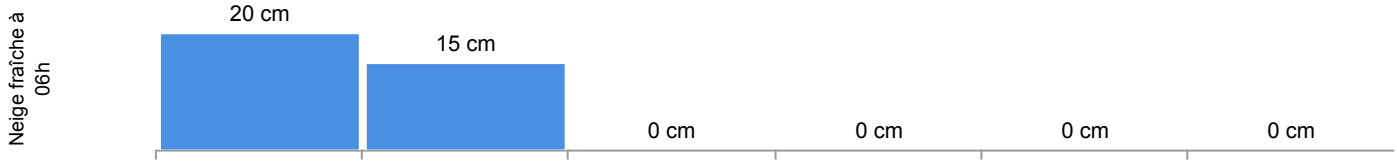

Risque d'avalanche	mer. 01/04	jeu. 02/04	ven. 03/04	sam. 04/04	dim. 05/04	lun. 06/04	mar. 07/04
	4	4	4	3	2	2	2

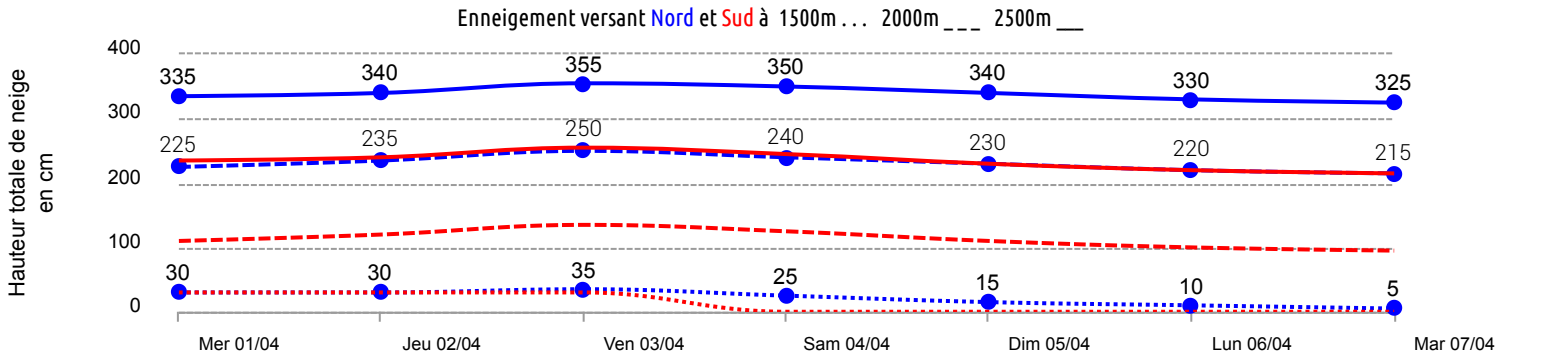

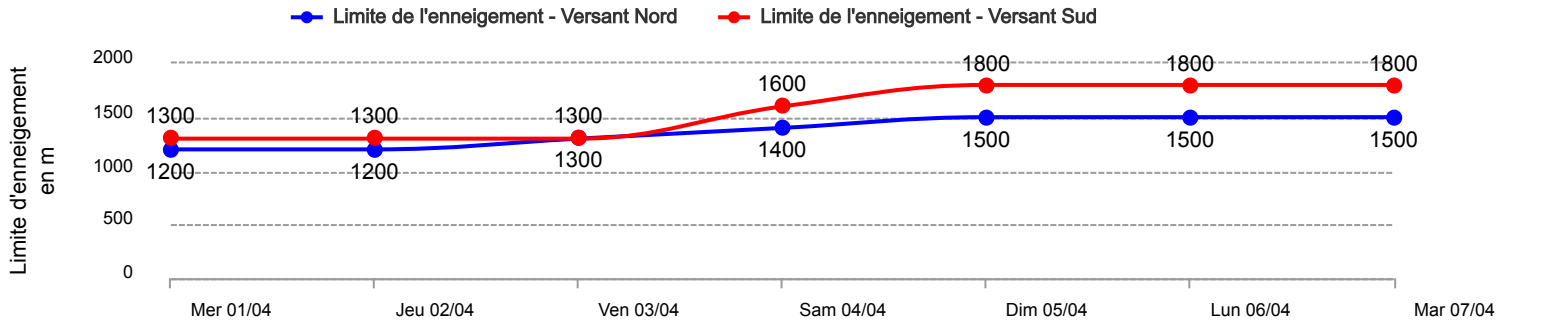

Pour consulter la vigilance en cours, veuillez vous rendre sur le site https://vigilance.meteofrance.fr/fr

Météo-France - 73 avenue de Paris, 94165 Saint-Mandé cedex - Contact : contact@meteo.fr

Bulletin neige & avalanches par téléphone au

0 892 68 10 20 Service 0,35 € / min + prix appel

Rédigé par Météo-France avec la contribution des observateurs du réseau nivo-météorologiques. Partenariat : ANMSM (Maires de Stations de Montagne), DSF (Domaines Skiables de France), ADSP (Directeurs de Pistes et de la Sécurité des Stations de Sports d'Hiver) et autres acteurs de la montagne.