Bulletin d'estimation du risque d'avalanche
(valable en dehors des pistes balisées et ouvertes)

MASSIF : Pays-Basque

Rédigé le mardi 7 avril 2026 à 16h

Estimation des risques pour le : MERCREDI 08 AVRIL

POURSUITE DE L'HUMIDIFICATION DANS LA DOUCEUR AMBIANTE.

2

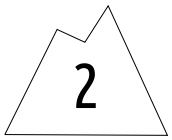

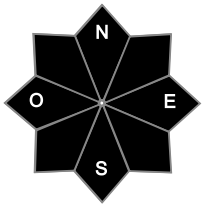

Indice de risque limité.

Départs spontanés : En neige humide au soleil, avalanches de fond possibles.

Déclenchements provoqués : En neige humide.

Indices de risque : 5 très fort - 4 fort - 3 marqué - 2 limité - 1 faible -- En noir : les pentes les plus dangereuses

Stabilité du manteau neigeux

Situation avalancheuse typique : neige humide avalanches de fond

Déclenchements provoqués:
Un simple skieur peut déclencher des départs ponctuels dans la neige humide, dans les pentes raides en tous versants au fil de la journée et de l'ensoleillement. Des avalanches petites à moyennes (taille 1 à 2) sont attendues dès la matinée en sud à sud-est, puis rapidement dans tous les autres versants au fil de la matinée et du déroulement de la journée, dans la douceur ambiante. Un bon regel matinal peut limiter l'activité avalancheuse tôt le matin, mais le risque sera bien présent dès la matinée, l'humidification se faisant rapidement.

Départs spontanés:
Des départs ponctuels sont attendus dans les pentes raides et en tous versants au fil de la journée et de l'ensoleillement. Ils sont peu importants le matin, avec un regel plus ou moins efficace, mais tendent à être plus nombreux ensuite avec l'humidification rapide. Des avalanches petites à moyennes (taille 1 à 2) sont généralement possibles. Des avalanches de fond sont également possibles en pentes raides, en partant d'une accumulation encore présente sur le haut du massif (secteurs Pic d'Anie et Pic d'Orhy), notamment près des fissures et des reptations récentes. Avalanches petites à moyennes possibles (taille 1 à 2), parfois grandes (taille 3).

Autres : Ponts de neige et corniches encore en place fragilisés au soleil.

Qualité de la neige

Enneigement : Encore bon pour la saison même si les limites remontent progressivement en altitude dans la douceur ambiante. Débutant vers 1500 à 1600m en nord, 1800m en sud.
État de la neige : Neige de printemps en général dans une grande majorité des secteurs. La neige est plutôt bien regelée à dure le matin, ramollissant assez rapidement au soleil. La neige poursuit ensuite son humidification, elle est lourde à parfois gorgée d'eau. Humidification un peu plus lente en versants nord mais accentuée et se faisant de plus en plus en profondeur dans la douceur ambiante.

Aperçu météo pour le mercredi 08 avril

	nuit	matin	après-midi	soir

Temps sec et plutôt bien ensoleillé, quelques passages nuageux d'altitude. Développements de quelques nuages l'après-midi sans incidence. Douceur.

Pluie-Neige				
Iso 0 °C	3 300 m	3 300 m	3 300 m	3 300 m
Vent 1000 m	↑ 30 km/h	↑ 15 km/h	↑ 15 km/h	↑ 15 km/h
Vent 2000 m	↖ 50 km/h	↖ 30 km/h	↑ 25 km/h	↖ 35 km/h

Épaisseur de neige hors-piste

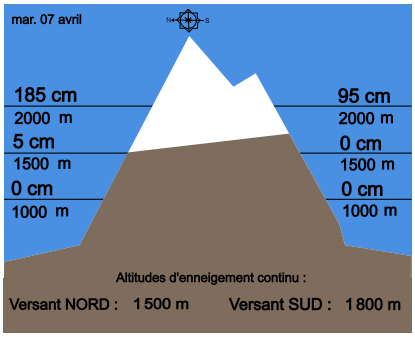

Précipitations à 1800 m

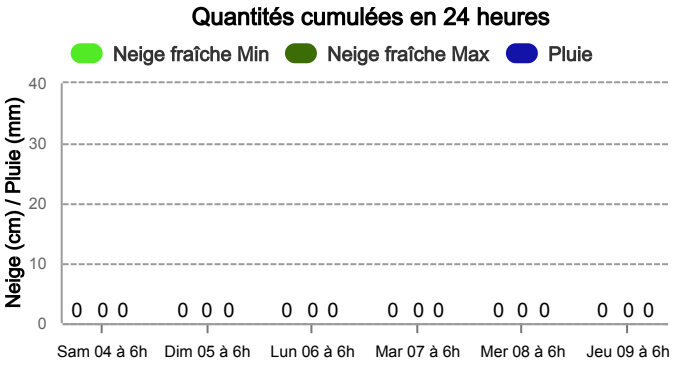

Tendance du jeudi 09 avril

2

Indice de risque limité

Risque stationnaire. Poursuite de l'humidification en profondeur du manteau neigeux avec la douceur ambiante en journée.

Pour consulter la vigilance en cours, veuillez vous rendre sur le site https://vigilance.meteofrance.fr/fr

Météo-France - 73 avenue de Paris, 94165 Saint-Mandé cedex - Contact : contact@meteo.fr

Rédigé par Météo-France avec la contribution des observateurs du réseau nivo-météorologiques. Partenariat : ANMSM (Maires de Stations de Montagne), DSF (Domaines Skiables de France), ADSP (Directeurs de Pistes et de la Sécurité des Stations de Sports d'Hiver) et autres acteurs de la montagne.

Bulletin neige & avalanches par téléphone au
0 892 68 10 20 Service 0,35 € / min + prix appel

RÉPUBLIQUE FRANÇAISE
Liberté Égalité Fraternité

METEO FRANCE
À VOS CÔTÉS, DANS UN CLIMAT QUI CHANGE

Bulletin d'estimation du risque d'avalanche
(valable en dehors des pistes balisées et ouvertes)

MASSIF : Pays-Basque

Rédigé le mardi 7 avril 2026 à 16h

Conditions nivo-météo des 7 derniers jours

	mer. 01/04				jeu. 02/04				ven. 03/04				sam. 04/04				dim. 05/04				lun. 06/04				mar. 07/04			
	03h	09h	15h	21h	03h	09h	15h	21h	03h	09h	15h	21h	03h	09h	15h	21h	03h	09h	15h	21h	03h	09h	15h	21h	03h	09h	15h	21h
Météo																												
Vent (km/h)	60	65	80	65	70	65	65	55	55	35	20	15	10	10	15	20	25	30	30	30	25	25	40	55	60	50	40	55
à 2000m																												
Vent (km/h)	35	35	45	45	45	40	45	35	30	20	10	10	5	5	5	10	10	10	2	10	10	10	10	15	25	25	15	30
à 1000m																												

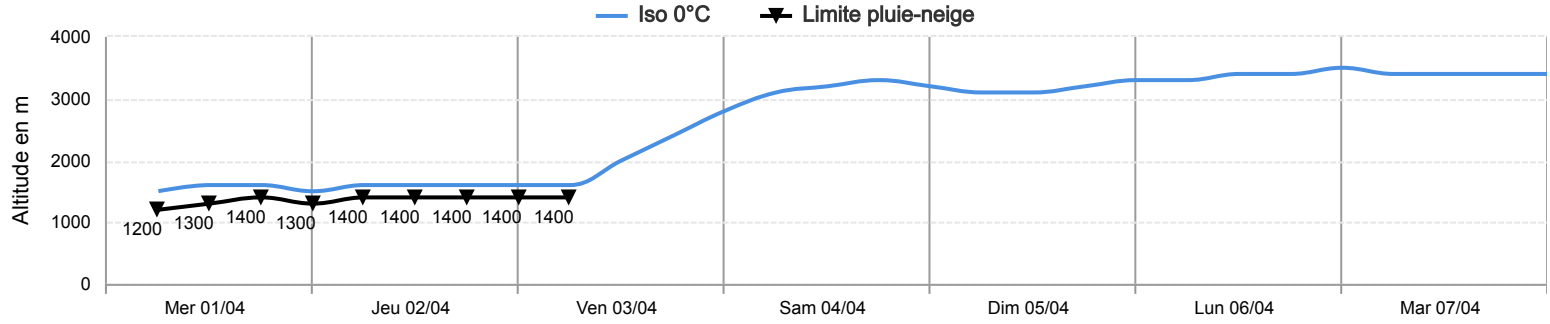

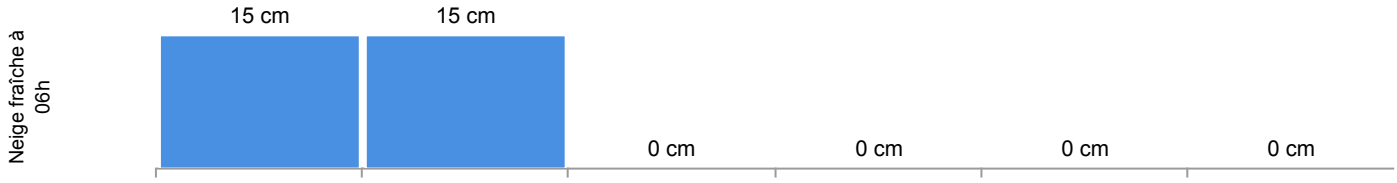

Risque d'avalanche	mer. 01/04	jeu. 02/04	ven. 03/04	sam. 04/04	dim. 05/04	lun. 06/04	mar. 07/04
	3	3	3	2	2	2	2

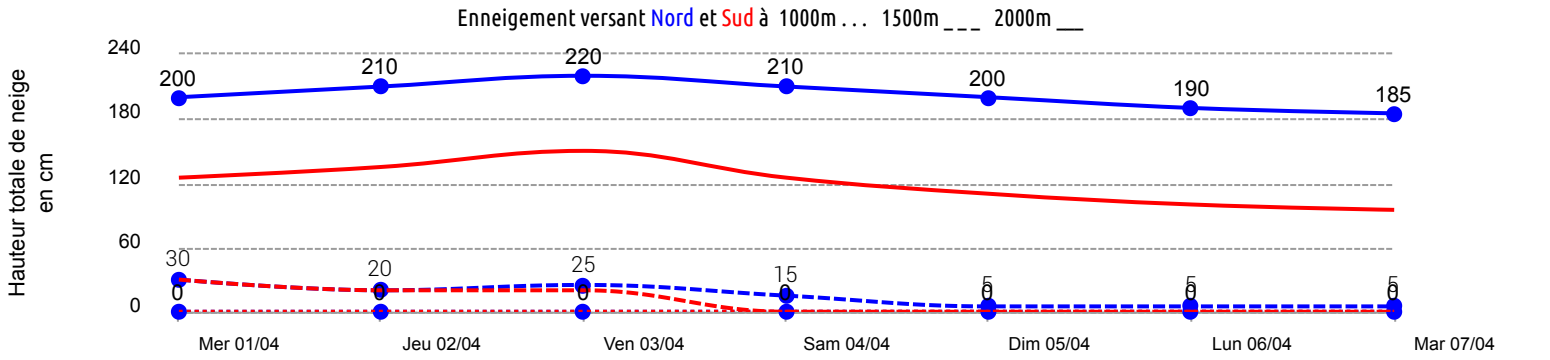

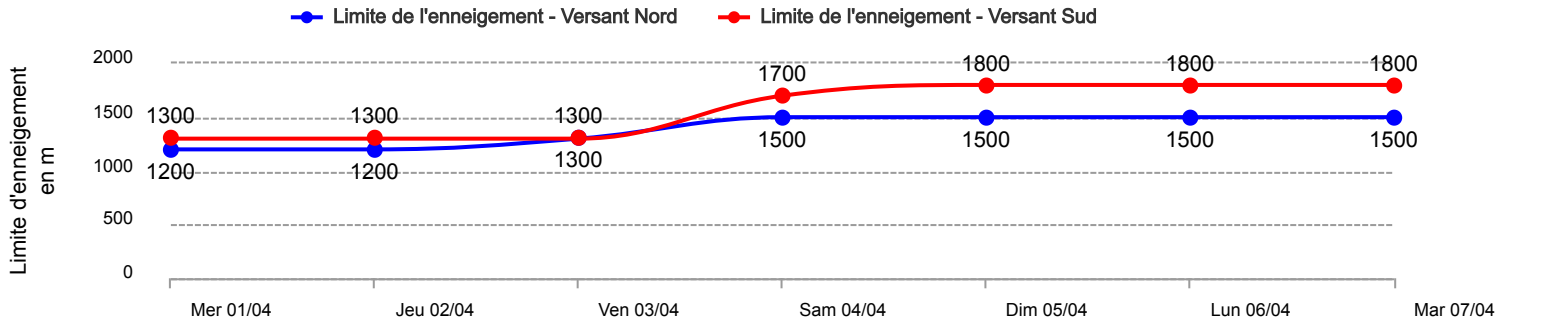

Pour consulter la vigilance en cours, veuillez vous rendre sur le site https://vigilance.meteofrance.fr/fr

Météo-France - 73 avenue de Paris, 94165 Saint-Mandé cedex - Contact : contact@meteo.fr

Bulletin neige & avalanches par téléphone au
0 892 68 10 20 Service 0,35 € / min + prix appel

Rédigé par Météo-France avec la contribution des observateurs du réseau nivo-météorologiques. Partenariat : ANMSM (Maires de Stations de Montagne), DSF (Domaines Skiables de France), ADSP (Directeurs de Pistes et de la Sécurité des Stations de Sports d'Hiver) et autres acteurs de la montagne.