Bulletin d'estimation du risque d'avalanche

(valable en dehors des pistes balisées et ouvertes)

MASSIF : Grandes-Rousses

Rédigé le mardi 7 avril 2026 à 17h

Estimation des risques pour le : MERCREDI 08 AVRIL

HUMIDIFICATION DU MANTEAU NEIGEUX EN TOUS VERSANTS. RARES DÉPARTS VOLUMINEUX POSSIBLES L'APRES-MIDI.

2

1 → 2

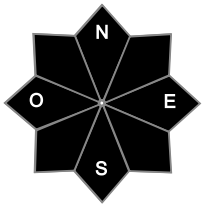

neige humide

Indice de risque faible évoluant en limité.

Départs spontanés : Avalanches humides de taille 1 à 2 en pentes ensoleillées / près des rochers. Rares grandes avalanches de taille 3 non exclues, départ linéaire et/ou au terrain possible.

Déclenchements provoqués : En pente bien humide, coulée ponctuelle sous les skis. Rare plaque en versant Nord d'altitude.

Indices de risque : 5 très fort - 4 fort - 3 marqué - 2 limité - 1 faible -- En noir : les pentes les plus dangereuses

Stabilité du manteau neigeux

Situation avalancheuse typique : neige humide — avalanches de fond

Départs spontanés : - Après un bon regel nocturne, de nouvelles avalanches humides peuvent se produire ce mercredi dès la fin de matinée, notamment dans les pentes réchauffées par le soleil, le plus souvent de taille 1 à 2. Dans un rare cas, une avalanche de glissement plus conséquente, au terrain, atteignant la taille 2 à 3, ne peut être exclue (alpage raide). Ces problématiques augmente au fil des heures au gré du parcours du soleil et du réchauffement des pentes. (Sud-est à Est le matin jusquà Ouest Sud-ouest en fin de journée).

L'humidification gagne en profondeur et on ne peut exclure qu'elle atteigne localement des couches fragiles enfouies dans le manteau, notamment dans les accumulations des versants Est et Ouest, auquel cas une avalanche plus conséquente de taille 3 est envisageable, avec départ linéaire et/ou jusqu'au terrain.

- Une rupture spontanée de corniche est également possible l'après-midi et à surveiller dans les secteurs concernés.

Déclenchements provoqués : En pentes soutenues et bien humidifiées, le pratiquant pourrait faire couler la neige humide sous les skis.

- Très localement en faces Nord d'altitude au-dessus de 2500 m environ, de rares plaques, souvent dures, peuvent subsister dans les zones d'accumulations où la neige récente a été travaillée voire soufflée par la bise de Nord-Est. Elles sont la plupart du temps difficiles à déclencher.

Autres : A l'ombre (le matin surtout) neige souvent très dure ou croutée par le regel. Surfaces glissantes généralisées.

Qualité de la neige

Qualification de l'enneigement : L'enneigement est très bon dès la moyenne montagne peu ensoleillée, et dans les combes d'altitude (ce qui est plus classique)... La fonte a bien débuté aux plus basses altitudes enneigées et dans les versants bien ensoleillés, elle se poursuit et s'accentue encore ce lundi.

Limites skiables : Vers 1300/1500m en plein Nord (hors sapins), 1600/2000m au soleil...

Qualité de la neige mercredi : En large Sud neige transformée, printanière. Après un bon regel nocturne, rapide humidification suivant la course du soleil. Neige encore sèche en plein Nord au dessus de 2400/2600m environ, avec une neige poudreuse dense en couloirs abrités ou bien souvent cartonnée/sculptée, durcie par la bise du début de semaine. En versants intermédiaires neige souvent croutée/cassante jusqu'en fin de journée.

Aperçu météo pour le mercredi 08 avril

	nuit	matin	après-midi	soir
Après une nuit claire, journée ensoleillée et très douce.				
Pluie-Neige				
Iso 0 °C	3 400 m	3 400 m	3 400 m	3 400 m
Vent 2000 m	↙ 10 km/h	↓ 0 km/h	↘ 0 km/h	↙ 5 km/h
Vent 3000 m	↙ 15 km/h	← 5 km/h	↗ 5 km/h	↙ 5 km/h

Épaisseur de neige hors-piste

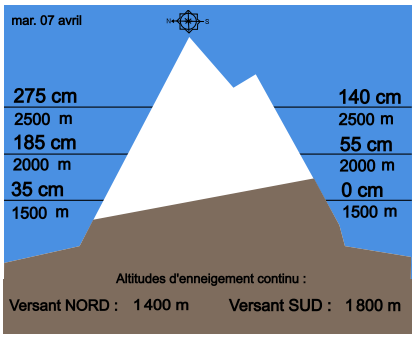

Précipitations à 1800 m

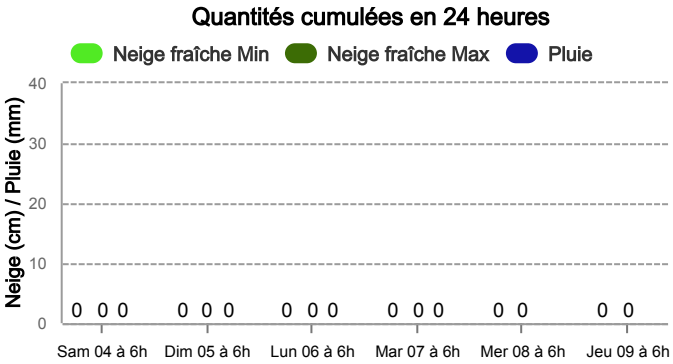

Tendance du jeudi 09 avril

2

Indice de risque limité

Risque sans grande évolution en faveur d'un temps sec et ensoleillé.

Pour consulter la vigilance en cours, veuillez vous rendre sur le site https://vigilance.meteofrance.fr/fr

Météo-France - 73 avenue de Paris, 94165 Saint-Mandé cedex - Contact : contact@meteo.fr

Rédigé par Météo-France avec la contribution des observateurs du réseau nivo-météorologiques. Partenariat : ANMSM (Maires de Stations de Montagne), DSF (Domaines Skiables de France), ADSP (Directeurs de Pistes et de la Sécurité des Stations de Sports d'Hiver) et autres acteurs de la montagne.

Bulletin neige & avalanches par téléphone au 0 892 68 10 20 Service 0,35 € / min + prix appel

RÉPUBLIQUE FRANÇAISE
Liberté Égalité Fraternité

METEO FRANCE
À VOS CÔTÉS, DANS UN CLIMAT QUI CHANGE

Bulletin d'estimation du risque d'avalanche
(valable en dehors des pistes balisées et ouvertes)
MASSIF : Grandes-Rousses

Rédigé le mardi 7 avril 2026 à 17h

Conditions nivo-météo des 7 derniers jours

	mer. 01/04				jeu. 02/04				ven. 03/04				sam. 04/04				dim. 05/04				lun. 06/04				mar. 07/04			
	03h	09h	15h	21h	03h	09h	15h	21h	03h	09h	15h	21h	03h	09h	15h	21h	03h	09h	15h	21h	03h	09h	15h	21h	03h	09h	15h	21h
Météo																												
Vent (km/h)	65	50	30	45	35	30	30	30	35	30	20	25	25	25	10	10	15	20	30	25	25	20	15	5	10	0	5	10
à 3000m																												
Vent (km/h)	45	35	30	15	10	5	5	5	5	5	0	5	15	10	10	5	5	10	15	10	10	10	10	0	5	0	5	5
à 2000m																												

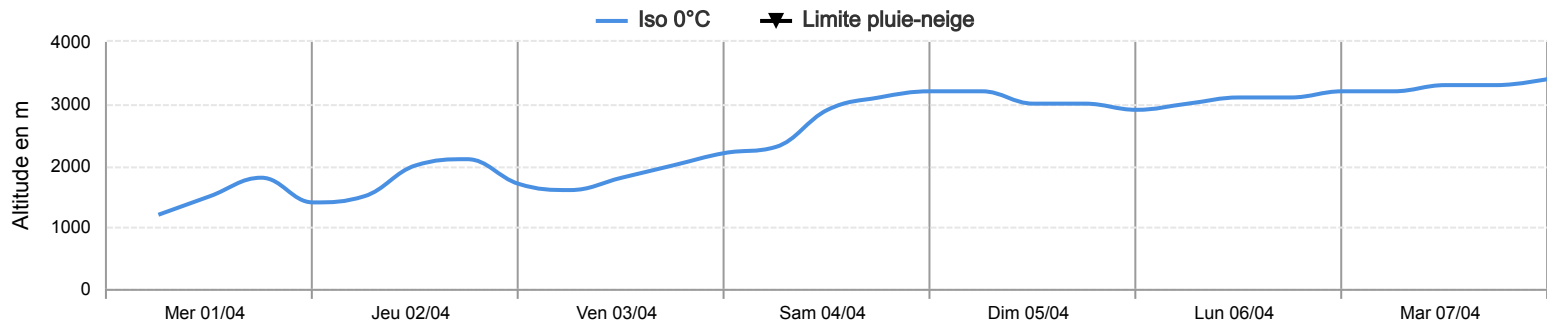

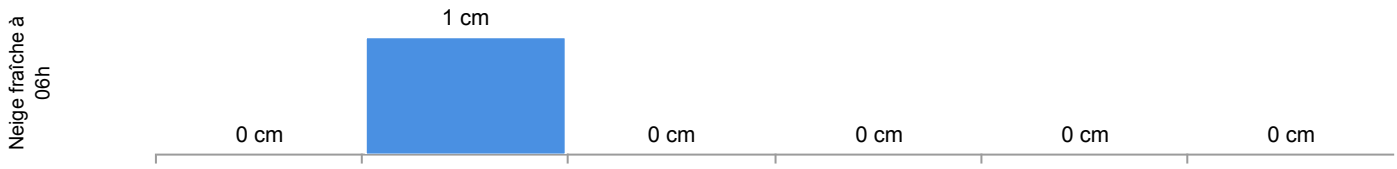

Risque d'avalanche	mer. 01/04	jeu. 02/04	ven. 03/04	sam. 04/04	dim. 05/04	lun. 06/04	mar. 07/04
	3	2	2	2	2	2	2

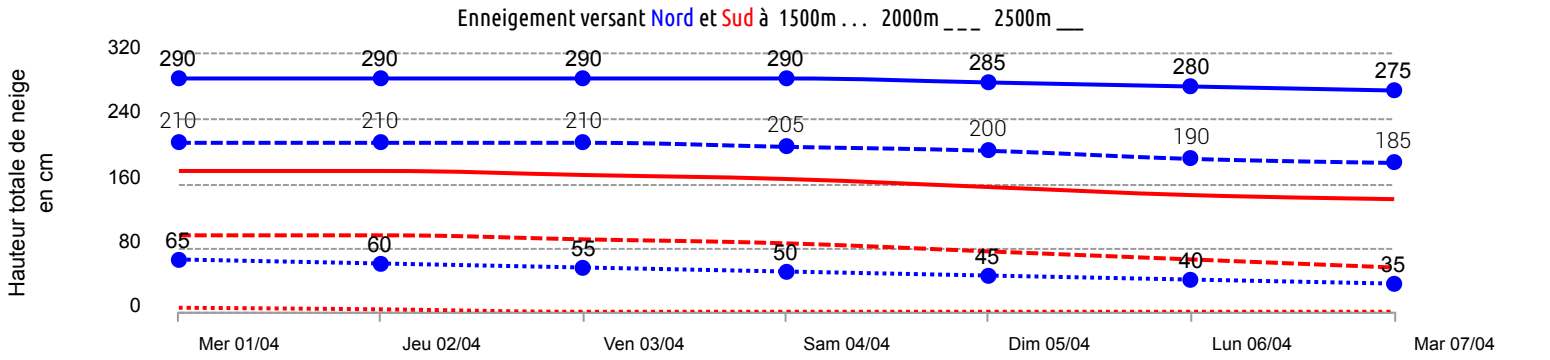

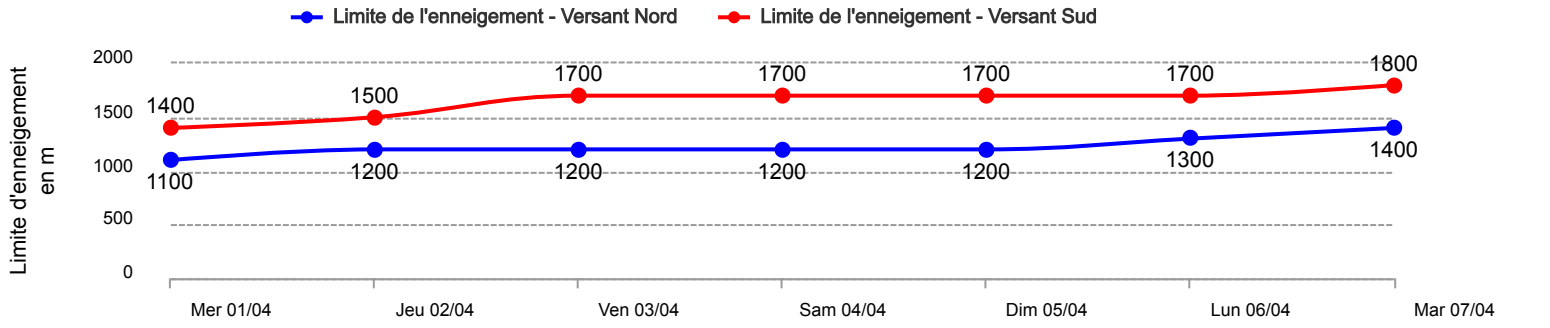

Pour consulter la vigilance en cours, veuillez vous rendre sur le site https://vigilance.meteofrance.fr/fr

Météo-France - 73 avenue de Paris, 94165 Saint-Mandé cedex - Contact : contact@meteo.fr

Rédigé par Météo-France avec la contribution des observateurs du réseau nivo-météorologiques. Partenariat : ANMSM (Maires de Stations de Montagne), DSF (Domaines Skiables de France), ADSP (Directeurs de Pistes et de la Sécurité des Stations de Sports d'Hiver) et autres acteurs de la montagne.

Bulletin neige & avalanches par téléphone au
0 892 68 10 20 Service 0,35 € / min + prix appel