Donnerstag 09.04.2026

Veröffentlicht am 08.04.2026 um 17:00

Vormittag

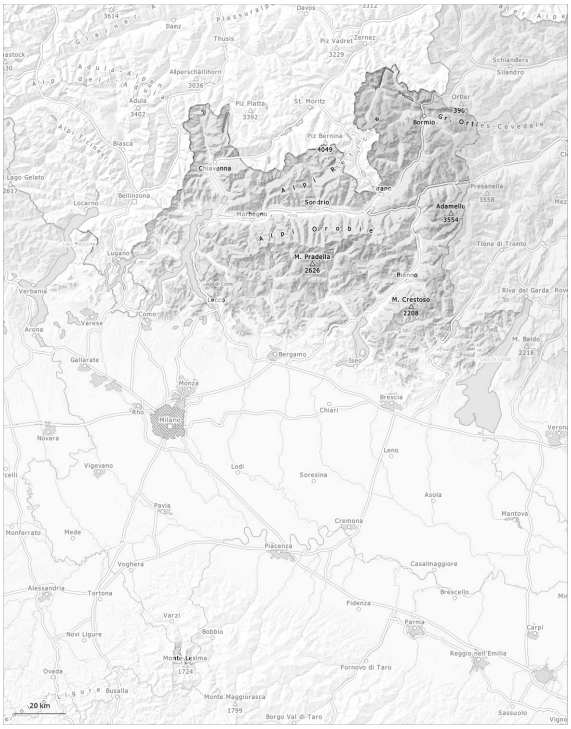

Nachmittag

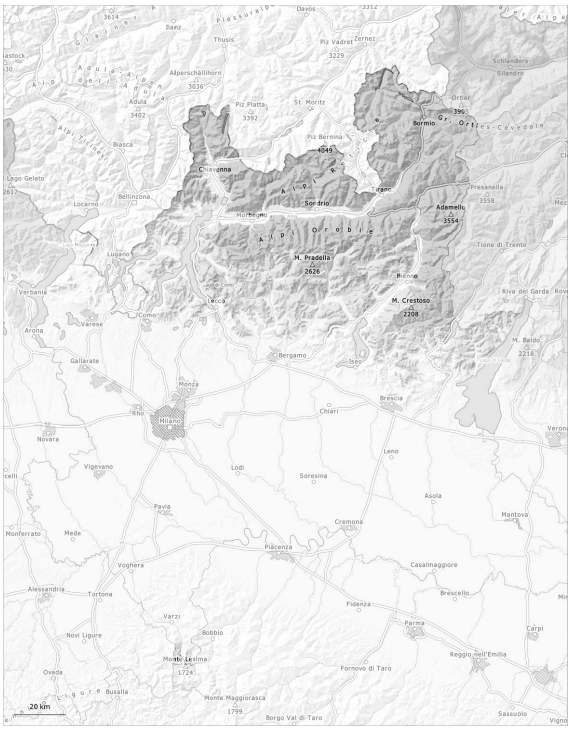

1	2	3	4	5
gering	mäßig	erheblich	groß	sehr groß

Gefahrenstufe 2 - Mäßig

AM:

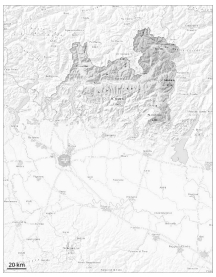

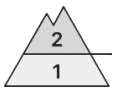

2500m

Tendenz: Lawinengefahr bleibt gleich
am Freitag, den 10.04.2026

Nassschnee

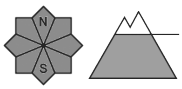

2500m

Altschnee

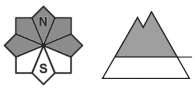

Waldgrenze

PM:

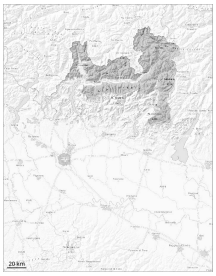

Tendenz: Lawinengefahr bleibt gleich
am Freitag, den 10.04.2026

Nassschnee

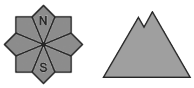

Altschnee

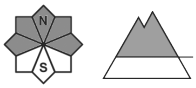

Waldgrenze

Allmählicher Anstieg der Gefahr von feuchten und nassen Lawinen mit der tageszeitlichen Erwärmung und der Sonneneinstrahlung.

Mit der tageszeitlichen Erwärmung und der Sonneneinstrahlung sind in allen Höhenlagen kleine und mittlere feuchte und nasse Lawinen möglich. Frischere Triebschneeansammlungen sind gut erkennbar. Die Triebschneeansammlungen können vor allem an steilen Schattenhängen vor allem mit großer Zusatzbelastung ausgelöst werden. Die Gefahrenstellen liegen vor allem an Felswandfüßen, sowie in Kammlagen, Rinnen und Mulden.
In der Altschneedecke sind an Nordwest-, Nord- und Nordosthängen Schwachschichten vorhanden. Lawinen können im Altschnee anbrechen vor allem an Nordwest-, Nord- und Nordosthängen vereinzelt groß werden.

Schneedecke

Gefahrenmuster gm.6: lockerer schnee und wind | gm.1: bodennahe schwachschicht

Diese frühlingshaften Wetterbedingungen führen ab dem Vormittag an allen Expositionen zu einer Anfeuchtung der Schneedecke. Die verschiedenen Triebschneeansammlungen sind miteinander und mit dem Altschnee verbunden.
In der Altschneedecke sind besonders an Schattenhängen einzelne Schwachschichten vorhanden.

> Stellenweise können Lawinen vor allem an Nordwest-, Nord- und Nordosthängen in tiefen Schichten ausgelöst werden.

Gefahrenstufe 2 - Mäßig

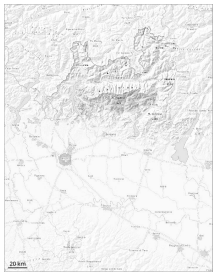

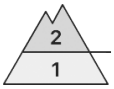

Waldgrenze

Tendenz: Lawinengefahr bleibt gleich
am Freitag, den 10.04.2026

Nassschnee

Waldgrenze

Nasse Lockerschneelawinen an allen Expositionen.

Die Schneeoberfläche ist tragfähig gefroren und weicht im Tagesverlauf auf. Mit der tageszeitlichen Erwärmung und der Sonneneinstrahlung sind im Tagesverlauf feuchte und nasse Lawinen möglich, aber meist nur kleine. Die frischeren Triebschneeansammlungen sind gut erkennbar und vor allem mit großer Belastung in ihren Randbereichen auslösbar.
Lawinen können bis auf den Boden durchreißen und teils mittlere Größe erreichen.

Schneedecke

Gefahrenmuster gm.10: frühjahrssituation gm.6: lockerer schnee und wind

Der wenige Neuschnee und insbesondere die mit dem starken Wind entstandenen Triebschneeansammlungen liegen auf einer ungünstigen Altschneeoberfläche.
Die Wärme führt ab dem Vormittag vor allem an Sonnenhängen teilweise zu einer zunehmenden Aufweichung der Schneedecke.

Gefahrenstufe 1 - Gering

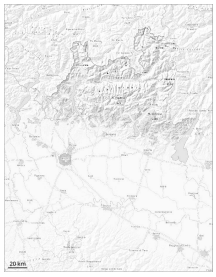

1

Tendenz: Lawinengefahr bleibt gleich
am Freitag, den 10.04.2026

Nassschnee

N
S

Waldgrenze

Triebschnee und Nassschnee sind die Hauptgefahr.

In Gipfellagen lokal mehrheitlich günstige Lawinensituation. Mit der tageszeitlichen Erwärmung steigt die Gefahr von nassen Lawinen im Tagesverlauf an. Oberhalb von rund 1500 m sind kleine kleine Lawinen möglich.

Schneedecke

Gefahrenmuster gm.10: frühjahrssituation

Mit der Erwärmung steigt die Auslösebereitschaft von nassen Rutschen und Lawinen an allen Expositionen in allen Höhenlagen an.