Jeudi 09.04.2026

Publié 08 04 2026, 17:00

Matin

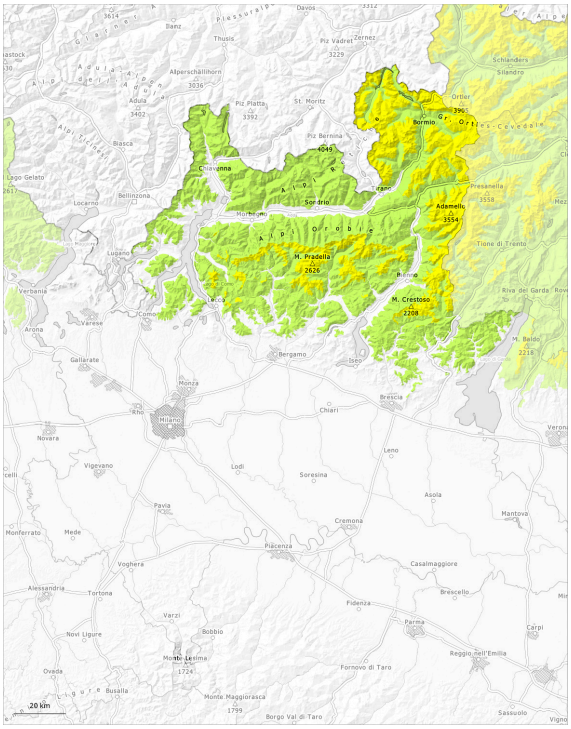
Davos
Piz Vadret
3229
Zernez
Thusis
Alpe Bella
Alpe Adula
Alpe Cadera
Alpe Cavaliera
Alpe Cadlas
Alpe Cadlas
Alpe Cadlas

Degré de danger 2 - Limité

AM:

2500m

Tendance: danger d'avalanche constant
leVendredi 10 04 2026

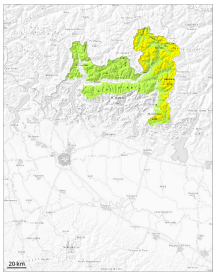

Avalanches mouillées (Neige humide)

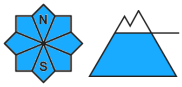

2500m

Neige ancienne (Sous-couche fragile persistante)

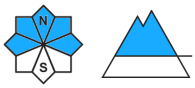

Limite de la forêt

PM:

Tendance: danger d'avalanche constant
leVendredi 10 04 2026

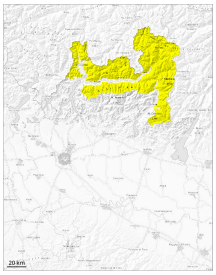

Avalanches mouillées (Neige humide)

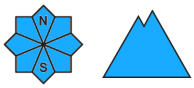

Neige ancienne (Sous-couche fragile persistante)

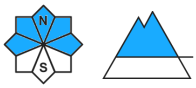

Limite de la forêt

Augmentation progressive du danger d'avalanches humides et mouillées avec le réchauffement diurne et le rayonnement solaire.

Des avalanches humides et mouillées de petite et moyenne taille sont possibles avec le réchauffement diurne et le rayonnement solaire à toutes les altitudes. Des accumulations plus récentes de neige soufflée sont facilement reconnaissables. Les accumulations de neige soufflée peuvent être déclenchées surtout avec une surcharge importante surtout sur les pentes raides à l'ombre. Les endroits dangereux se situent surtout au pied des parois rocheuses, ainsi que près des crêtes, combes et couloirs.
Dans le manteau neigeux ancien des couches fragiles sont présentes sur les pentes exposées au nord-

ouest, au nord et au nord-est. Des avalanches peuvent se déclencher dans la neige ancienne surtout sur les pentes exposées au nord-ouest, au nord et au nord-est atteindre une grande taille de manière isolée.

Manteau neigeux

Modèles de danger md.6: froid, neige légère et vent | md.1: sous-couche fragile persistante

Ces conditions météorologiques printanières entraînent à partir de la matinée à toutes les expositions une humidification du manteau neigeux. Les différentes accumulations de neige soufflée sont liées entre elles et avec la neige ancienne.
Dans le manteau neigeux ancien des couches fragiles isolées sont présentes, spécialement sur les pentes à l'ombre. Des avalanches peuvent par endroits être déclenchées surtout sur les pentes exposées au nord-ouest, au nord et au nord-est dans les couches profondes du manteau neigeux.

Degré de danger 2 - Limité

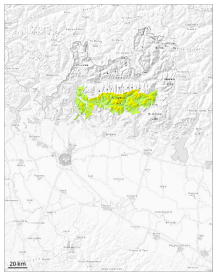

Limite de la forêt

Tendance: danger d'avalanche constant
leVendredi 10 04 2026

Avalanches mouillées (Neige humide)

Limite de la forêt

Des avalanches de neige meuble mouillée à toutes les expositions.

La surface de la neige est gelée et porteuse et se ramollit en cours de journée. Avec le réchauffement diurne et le rayonnement solaire en cours de journée des avalanches humides et mouillées sont possibles, mais en général uniquement de petite taille. Les accumulations plus récentes de neige soufflée sont détectables facilement et surtout déclenchables avec une surcharge importante à leur périphérie.
Des avalanches peuvent entraîner le manteau jusqu'au sol et atteindre parfois une taille moyenne.

Manteau neigeux

Modèles de danger md.10: situation de printemps | md.6: froid, neige légère et vent

La neige fraîche peu abondante et en particulier les accumulations de neige soufflée qui se sont formées avec le vent fort reposent sur une surface de neige ancienne défavorable.
La chaleur entraîne à partir de la matinée surtout sur les pentes au soleil partiellement un ramollissement croissant du manteau neigeux.

Degré de danger 1 - Faible

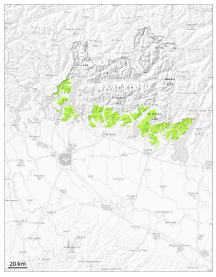

1

Tendance: danger d'avalanche constant
leVendredi 10 04 2026

Avalanches mouillées (Neige humide)

Limite de la forêt

Neige soufflée et neige mouillée constituant le danger principal.

À proximité des sommets situation avalancheuse majoritairement favorable localement. Avec le réchauffement diurne le danger d'avalanches mouillées augmente en cours de journée. Au-dessus d'environ 1500 m des petites avalanches de petite taille sont possibles.

Manteau neigeux

Modèles de danger md.10: situation de printemps

Avec le réchauffement la probabilité de déclenchement de coulées et avalanches mouillées augmente à toutes les expositions à toutes les altitudes.