Giovedì 09.04.2026

Pubblicato il 08.04.2026 alle ore 17:00

Mattina

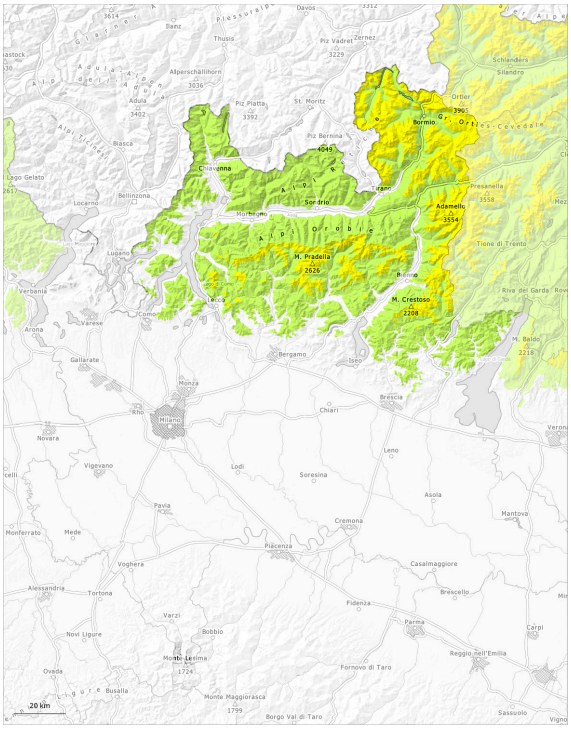
Davos
Thusis
Piz Vadret
3229
Zernez
Alpe
Schlanders
Silandro
Alpe Bernina
Alpe Adula
Alpe Albula
Alpe Livigno
Alpe Ortler-Cevedale
Alpe Orobie
Alpe Lepontine
Alpe Pennine
Alpe Lepontine
Alpe Pennine
Alpe Lepontine
Alpe Pennine

Grado di pericolo 2 - Moderato

AM:

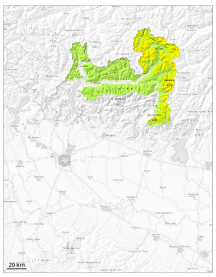

2500m

Tendenza: pericolo valanghe stabile
per Venerdì il 10.04.2026

Neve bagnata

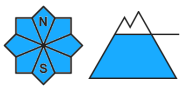

2500m

Strati deboli persistenti

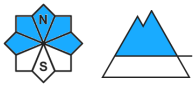

Limite del bosco

PM:

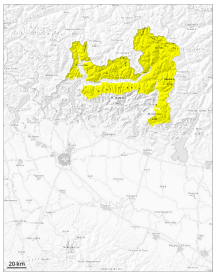

Tendenza: pericolo valanghe stabile
per Venerdì il 10.04.2026

Neve bagnata

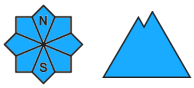

Strati deboli persistenti

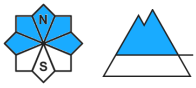

Limite del bosco

Con il rialzo termico e l'irradiazione solare diurni, progressivo aumento del pericolo di valanghe umide e bagnate.

Con il rialzo termico e l'irradiazione solare diurni, sono possibili valanghe umide e bagnate di piccole e medie dimensioni a tutte le altitudini. Gli ultimi accumuli di neve ventata sono ben individuabili. Gli accumuli di neve ventata possono subire un distacco soprattutto in caso di forte sovraccarico soprattutto sui pendii ripidi ombreggiati. I punti pericolosi si trovano soprattutto nelle basi di pareti rocciose, come pure nelle zone in prossimità delle creste, nei canaloni e nelle conche.
Sui pendii esposti a nord ovest, nord e nord est, all'interno del manto di neve vecchia si trovano strati fragili. Le valanghe possono coinvolgere il manto di neve vecchia, soprattutto sui pendii esposti a nord ovest, nord e nord est, raggiungere grandi dimensioni a livello isolato.

Manto nevoso

Situazione tipo st.6: neve a debole coesione e vento | st.1: strato debole persistente basale

A partire dalla mattinata queste condizioni meteo primaverili causeranno a tutte le esposizioni un inumidimento del manto nevoso. Il legame tra i vari accumuli di neve ventata e quello tra i vari accumuli di neve ventata e la neve vecchia è in corso.

Principalmente sui pendii ombreggiati, all'interno del manto di neve vecchia si trovano isolati strati fragili. In alcuni punti, le valanghe possono subire un distacco negli strati profondi del manto nevoso soprattutto sui pendii esposti a nord ovest, nord e nord est.

Grado di pericolo 2 - Moderato

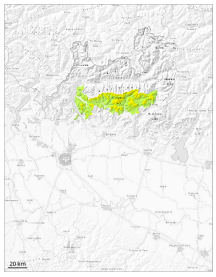

Limite del bosco

Tendenza: pericolo valanghe stabile
per Venerdì il 10.04.2026

Neve bagnata

Limite del bosco

Valanghe bagnate di neve a debole coesione a tutte le esposizioni.

La superficie del manto nevoso si è rigelata ed è portante e si ammorbidirà nel corso della giornata. Con il rialzo termico e l'irradiazione solare diurni, nel corso della giornata sono possibili valanghe umide e bagnate, ma per lo più solo di piccole dimensioni. Gli ultimi accumuli di neve ventata sono ben individuabili e possono subire un distacco soprattutto in seguito a un forte sovraccarico nelle zone marginali.
Le valanghe possono trascinare l'interno manto nevoso e in parte raggiungere dimensioni medie.

Manto nevoso

Situazione tipo st.10: situazione primaverile | st.6: neve a debole coesione e vento

La poca neve fresca e soprattutto gli accumuli di neve ventata che si sono formati con il vento di forte intensità poggiano su una sfavorevole superficie del manto di neve vecchia.
A partire dalla mattinata il calore causerà soprattutto sui pendii soleggiati in parte un progressivo ammorbidimento del manto nevoso.

Grado di pericolo 1 - Debole

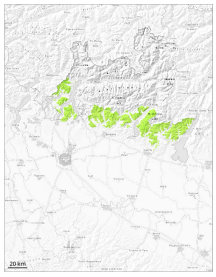

1

Tendenza: pericolo valanghe stabile
per Venerdì il 10.04.2026

Neve bagnata

Limite del bosco

Neve ventata e neve bagnata sono la principale fonte di pericolo.

In prossimità delle cime, la situazione valanghiva è a livello locale per lo più favorevole. Con il rialzo termico diurno, nel corso della giornata il pericolo di valanghe bagnate aumenterà. Al di sopra dei 1500 m circa sono possibili piccole valanghe di piccole dimensioni.

Manto nevoso

Situazione tipo st.10: situazione primaverile

Con il rialzo termico, la probabilità di distacco di colate e valanghe bagnate aumenterà a tutte le esposizioni a tutte le altitudini.