ICGC Institut Cartogràfic i Geològic de Catalunya

Servei Meteorològic de Catalunya meteo.cat

Boletín de peligro de aludes para el Pirineo de Catalunya
Del 08/04/2026 al 09/04/2026

(Válido fuera pistas de esquí y zonas no controladas)

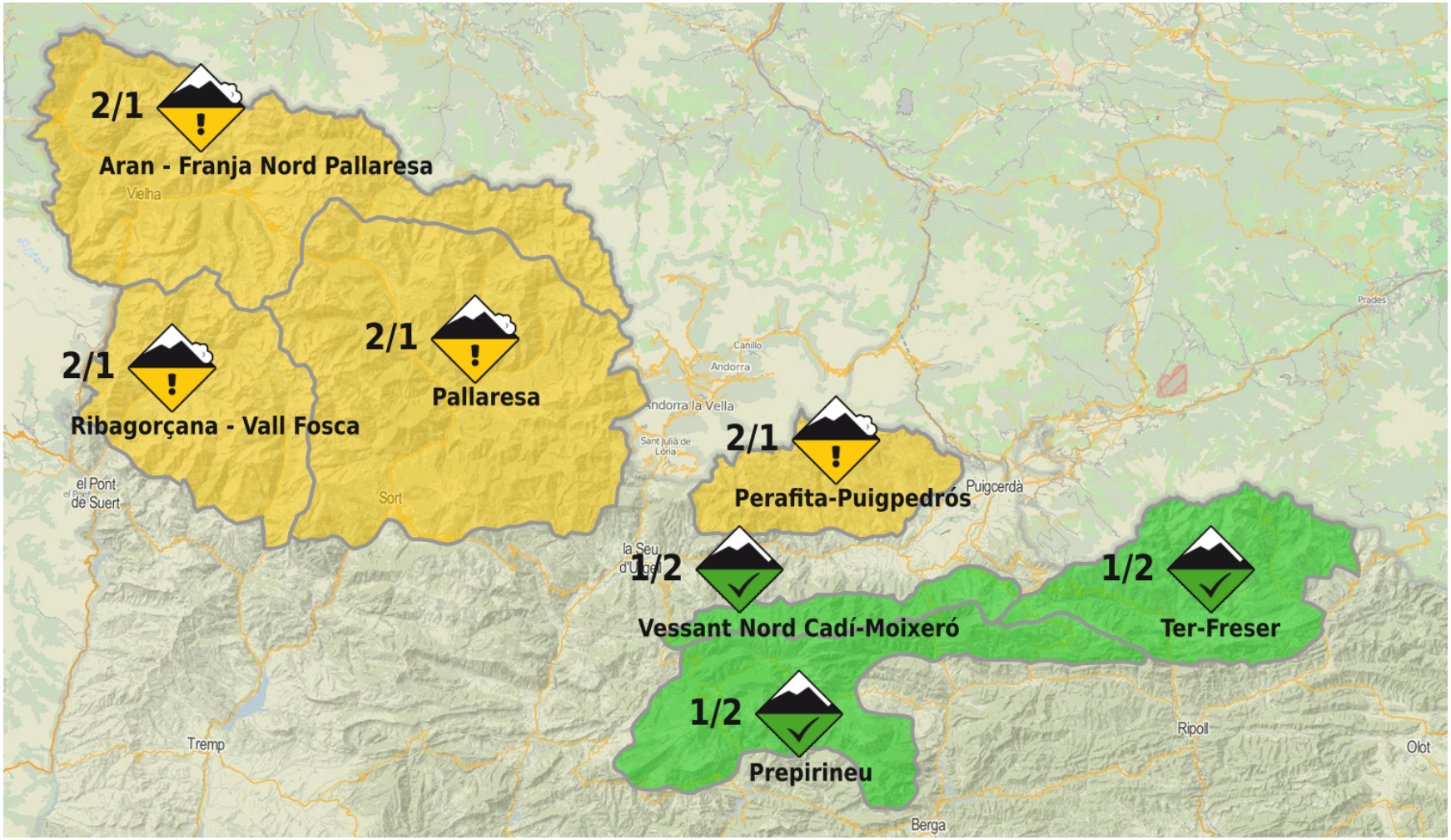

5 MUY FUERTE	4 FUERTE	3 NOTABLE	2 LIMITADO	1 DÉBIL

ICGC Institut Cartogràfic i Geològic de Catalunya

Servei Meteorològic de Catalunya

Boletín de peligro de aludes Aran - Franja Nord Pallaresa Del 08/04/2026 al 09/04/2026

(Válido fuera pistas de esquí y zonas no controladas)

LIMITADO (2) desde media mañana. DÉBIL (1) durante el resto.

Situación primaria

Nieve húmeda

Distribución

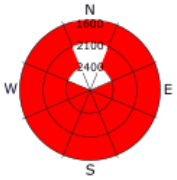

Tamaño

Origen

Tendencia

Situación secundaria

Capas débiles persistentes

Distribución

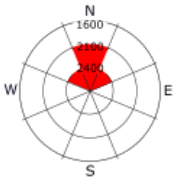

Tamaño

Origen

Tendencia

Estado del manto nivoso

Ha disminuido la caída de aludes naturales de placa de tamaños 2 y 3 (suficiente para enterrar a un grupo de personas) por encima de capas débiles persistentes. Los aludes accidentales todavía son posibles por encima de 2.300 m en terreno umbrío por sobrecarga débil, allí donde encontramos la nieve ligeramente placada, en sectores protegidos del viento, aunque superficialmente esté un poco humedecida. Tras el rehielo nocturno, a partir de media mañana aumentará el humedecimiento respecto a días pasados, ya que por la tarde puede haber nubes bajas enganchadas a las cimas. A partir de media mañana habrá aludes de nieve húmeda de tamaños 1 y 2 (suficiente para enterrar a una persona). Serán más frecuentes en las cotas más bajas y en el terreno más soleado, cerca de puntos oscuros como rocas y árboles. También se espera la caída natural de deslizamientos basales de tamaño 2 en terreno propicio.

Distribución del manto nivoso

Los espesores a unos 2.200 m rondan los 150-220 cm. Tras la disminución de los grosores por el fuerte asentamiento de días pasados, actualmente los grosores menguan a razón de unos 4 cm por día. Sin embargo, los valores están muy por encima de los normales para la época.

Tendencia para las próximas 48-72h

Continuará el problema de nieve húmeda, así como los deslizamientos basales, que en terreno propicio irán ganando protagonismo. Peligro: SIN CAMBIOS.

El próximo boletín será emitido el día 2026-04-09

5 MUY FUERTE	4 FUERTE	3 NOTABLE	2 LIMITADO	1 DÉBIL

EAWS EUROPEAN AVALANCHE WARNING SERVICES

ICGC Institut Cartogràfic i Geològic de Catalunya

Servei Meteorològic de Catalunya

Boletín de peligro de aludes Ribagorçana - Vall Fosca Del 08/04/2026 al 09/04/2026

(Válido fuera pistas de esquí y zonas no controladas)

LIMITADO (2) en el extremo norte a partir de media mañana. DÉBIL (1) en el resto.

Situación primaria

Nieve húmeda

Distribución

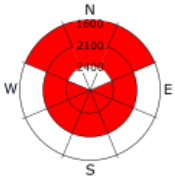

Tamaño

Origen

Tendencia

Situación secundaria

Capas débiles persistentes

Distribución

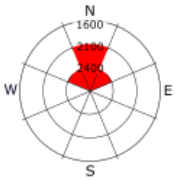

Tamaño

Origen

Tendencia

Estado del manto nivoso

El manto seguirá húmedo durante las horas diurnas y se enfría y rehiela con facilidad a lo largo de la noche. A partir de media mañana podrán caer aludes de nieve húmeda en terreno muy pendiente soleado; serán de tamaño 1 (pequeña, pero suficiente para arrastrarnos), especialmente en torno a puntos rocosos y afectando principalmente a la nieve superficial de los últimos episodios. Hay que evitar el terreno donde la penetración de la bota o el esquí sean profundas, así como laderas en las que observamos caídas de purgas. En la mitad norte, en terreno muy umbrío las placas de viento formadas en la última nevada reposan sobre niveles de nieve granulada; además pueden seguir creciendo niveles de facetas por debajo de las placas. Al paso de un grupo de personas se podrían desencadenar aludes de placa de hasta tamaño 2 (suficiente para enterrar a una persona). Los puntos sensibles están allí donde la nieve no se encuentre encostrada.

Distribución del manto nivoso

La nieve es continua a partir de 1.700 m en terreno umbrío y de 1.900 m en solanas. Los grosores alcanzan los 100-120 cm a unos 2.200 m, con frecuentes deflaciones y acumulaciones por encima del nivel del bosque. Estos valores están algo por debajo de los normales para la época. Debido a la fusión, van disminuyendo a razón de unos 4 cm por día.

Tendencia para las próximas 48-72h

Aparte de la mitad norte, donde hay que tener cuidado en las umbrías, a lo largo de la semana el humedecimiento durante las horas de máxima insolación seguirá siendo el principal problema a tener en cuenta. Peligro SIN CAMBIOS.

El próximo boletín será emitido el día 2026-04-09

5 MUY FUERTE	4 FUERTE	3 NOTABLE	2 LIMITADO	1 DÉBIL

EAWS EUROPEAN AVALANCHE WARNING SERVICES

ICGC Institut Cartogràfic i Geològic de Catalunya

Servei Meteorològic de Catalunya

Boletín de peligro de aludes Pallaresa
Del 08/04/2026 al 09/04/2026

(Válido fuera pistas de esquí y zonas no controladas)

LIMITADO (2) en el extremo norte a partir de media mañana. DÉBIL (1) en el resto.

Situación primaria

Nieve húmeda

Distribución

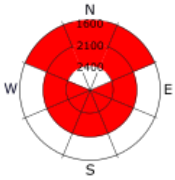

Tamaño

Origen

Tendencia

Situación secundaria

Capas débiles persistentes

Distribución

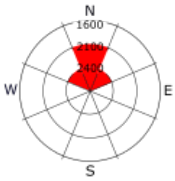

Tamaño

Origen

Tendencia

Estado del manto nivoso

El manto seguirá húmedo durante las horas diurnas y se enfría y rehiela con facilidad a lo largo de la noche. A partir de media mañana podrán caer aludes de nieve húmeda en terreno muy pendiente soleado; serán de tamaño 1 (pequeña, pero suficiente para arrastrarnos), especialmente en torno a puntos rocosos y afectando principalmente a la nieve superficial de los últimos episodios. Hay que evitar el terreno donde la penetración de la bota o el esquí sean profundas, así como laderas en las que observamos caídas de purgas. En la mitad norte, en terreno muy umbrío las placas de viento formadas en la última nevada reposan sobre niveles de nieve granulada; además pueden seguir creciendo niveles de facetas por debajo de las placas. Al paso de un grupo de personas se podrían desencadenar aludes de placa de hasta tamaño 2 (suficiente para enterrar a una persona). Los puntos sensibles están allí donde la nieve no se encuentre encostrada.

Distribución del manto nivoso

La nieve es continúa a partir de 1.700 m en terreno umbrío y de 1.900 m en solanas. Los grosores alcanzan los 100-120 cm a unos 2.200 m, con frecuentes deflaciones y acumulaciones por encima del nivel del bosque. Debido a la fusión, los grosores disminuyen a razón de 4 cm por día.

Tendencia para las próximas 48-72h

Aparte de la mitad norte, donde hay que tener cuidado en las umbrías, a lo largo de la semana el humedecimiento durante las horas de máxima insolación seguirá siendo el principal problema a tener en cuenta. Peligro SIN CAMBIOS.

El próximo boletín será emitido el día 2026-04-09

5 MUY FUERTE	4 FUERTE	3 NOTABLE	2 LIMITADO	1 DÉBIL

EAWS EUROPEAN AVALANCHE WARNING SERVICES

ICGC Institut Cartogràfic i Geològic de Catalunya

Servei Meteorològic de Catalunya

Boletín de peligro de aludes Perafita-Puigpedrós Del 08/04/2026 al 09/04/2026

(Válido fuera pistas de esquí y zonas no controladas)

LIMITADO (2) en el extremo norte a partir de media mañana. DÉBIL (1) en el resto.

Situación primaria

Nieve húmeda

Distribución

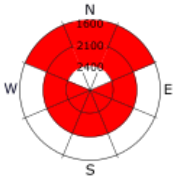

Tamaño

Origen

Tendencia

Situación secundaria

Capas débiles persistentes

Distribución

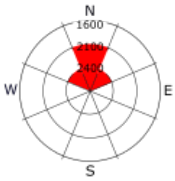

Tamaño

Origen

Tendencia

Estado del manto nivoso

El manto seguirá húmedo durante las horas diurnas y se enfría y rehiela con facilidad a lo largo de la noche. A partir de media mañana podrán caer aludes de nieve húmeda en terreno muy pendiente soleado; serán de tamaño 1 (pequeña, suficiente para arrastrarnos), especialmente en puntos rocosos y afectando principalmente a la nieve superficial de los últimos episodios. El humedecimiento se puede alargar hasta el anochecer por nubes bajas en la cima. Hay que evitar el terreno donde la penetración de la bota o el esquí sean profundas, así como laderas en las que observamos caídas de purgas. En el extremo norte, en terreno umbrío las placas de viento formadas en la última nevada reposan sobre niveles de nieve granulada; además se pueden formar niveles de facetas por debajo de las placas. Al paso de un grupo de personas se podrían desencadenar aludes de placa hasta tamaño 2 (suficiente para enterrar a una persona). Los puntos sensibles están allí donde la nieve no se encuentre encostrada.

Distribución del manto nivoso

Hay nieve en el suelo por encima de 1.900 m en terreno umbrío, y de 2.200 m en solanas. Es esquiable a partir de 2.000 m en N. Los espesores, aunque irregulares, rondan los 60-100 cm en umbrías, a 2.300 m; existen deflaciones y acumulaciones por encima del nivel del bosque. Son grosores por encima de los habituales Debido a la fusión, disminuye a razón de unos 6 cm por día en vertientes soleadas.

Tendencia para las próximas 48-72h

Aparte del extremo norte, donde hay que ir con cuidado a las umbrías, a lo largo de la semana el humedecimiento durante las horas de máxima insolación seguirá siendo el principal problema a tener en cuenta. Peligro SIN CAMBIOS.

El próximo boletín será emitido el día 2026-04-09

5 MUY FUERTE	4 FUERTE	3 NOTABLE	2 LIMITADO	1 DÉBIL

EAWS EUROPEAN AVALANCHE WARNING SERVICES

ICGC Institut Cartogràfic i Geològic de Catalunya

Servei Meteorològic de Catalunya

Boletín de peligro de aludes Vessant Nord Cadí-Moixeró Del 08/04/2026 al 09/04/2026

(Válido fuera pistas de esquí y zonas no controladas)

DÉBIL (1). LIMITADO (2) a partir de media mañana.

Situación primaria

Nieve húmeda

Distribución

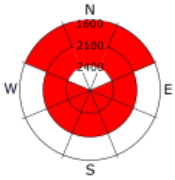

Tamaño

Origen

Tendencia

Situación secundaria

Capas débiles persistentes

Distribución

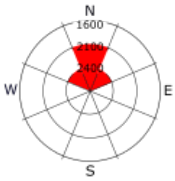

Tamaño

Origen

Tendencia

Estado del manto nivoso

El manto seguirá húmedo durante las horas diurnas y se enfría y rehiela con facilidad a lo largo de la noche. A partir de media mañana podrán caer aludes de nieve húmeda en terreno muy pendiente soleado; serán de tamaño 1 (pequeña, pero suficiente para arrastrarnos), especialmente en torno a puntos rocosos y afectando principalmente a la nieve superficial de los últimos episodios. Hay que evitar el terreno donde la penetración de la bota o el esquí sean profundas, así como laderas en las que observamos caídas de purgas. En terreno muy umbrío las placas de viento formadas en la última nevada reposan sobre niveles de nieve granulada; además pueden crecer los niveles de facetas que hay por debajo de las placas. Al paso de un grupo de personas se podrían desencadenar aludes de placa de hasta tamaño 2 (mediano, suficiente para enterrar a una persona). Los puntos sensibles están allí donde la nieve no se encuentre encostrada.

Distribución del manto nivoso

En umbrías hay nieve por encima de unos 1.600 m; en solanas por encima de unos 2.000 m. Los grosores están alrededor de 150-170 cm a 2.200 m, con algunas acumulaciones y deflaciones por encima del nivel del bosque. Estos valores son muy excedentarios para la época del año. Debido a la fusión, van disminuyendo a razón de unos 4 cm por día.

Tendencia para las próximas 48-72h

A lo largo de la semana el humedecimiento durante las horas de máxima insolación seguirá siendo el principal problema a tener en cuenta. Peligro SIN CAMBIOS.

El próximo boletín será emitido el día 2026-04-09

5 MUY FUERTE	4 FUERTE	3 NOTABLE	2 LIMITADO	1 DÉBIL

EAWS EUROPEAN AVALANCHE WARNING SERVICES

ICGC Institut Cartogràfic i Geològic de Catalunya

Servei Meteorològic de Catalunya

Boletín de peligro de aludes Prepirineu
Del 08/04/2026 al 09/04/2026

(Válido fuera pistas de esquí y zonas no controladas)

DÉBIL (1). LIMITADO (2) a partir de media mañana.

Situación primaria

Nieve húmeda

Distribución

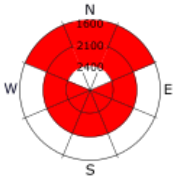

Tamaño

Origen

Tendencia

Estado del manto nivoso

El manto seguirá húmedo durante las horas diurnas y se enfría y rehiela con facilidad a lo largo de la noche. A partir de media mañana podrán caer aludes de nieve húmeda en terreno muy pendiente soleado; serán de tamaño 1 (pequeña, pero suficiente para arrastrarnos), especialmente en torno a puntos rocosos y afectando principalmente a la nieve superficial de los últimos episodios. Hay que evitar el terreno donde la penetración de la bota o el esquí sean profundas, así como laderas en las que observamos caídas de purgas. Los puntos sensibles están allí donde la nieve no se encuentre encostrada.

Distribución del manto nivoso

El manto es continuo por encima de unos 1.800 m en terreno umbrío y de unos 2.000 m en solanas. Los espesores, aunque irregulares, rondan los 80-110 cm a 2.300 m. Debido a la fusión, van disminuyendo a razón de unos 4 cm por día.

Tendencia para las próximas 48-72h

A lo largo de la semana el humedecimiento durante las horas de máxima insolación seguirá siendo el principal problema a tener en cuenta. Peligro SIN CAMBIOS.

El próximo boletín será emitido el día 2026-04-09

5 MUY FUERTE	4 FUERTE	3 NOTABLE	2 LIMITADO	1 DÉBIL

EAWS EUROPEAN AVALANCHE WARNING SERVICES

ICGC Institut Cartogràfic i Geològic de Catalunya

Servei Meteorològic de Catalunya meteo.cat

Boletín de peligro de aludes Ter-Freser
Del 08/04/2026 al 09/04/2026

(Válido fuera pistas de esquí y zonas no controladas)

DÉBIL (1). LIMITADO (2) a partir de media mañana.

Situación primaria

Nieve húmeda

Distribución

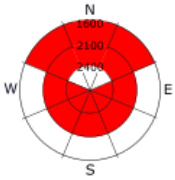

Tamaño

Origen

Tendencia

Situación secundaria

Capas débiles persistentes

Distribución

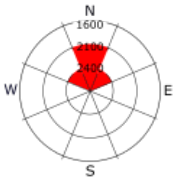

Tamaño

Origen

Tendencia

Estado del manto nivoso

El manto seguirá húmedo durante las horas diurnas y se enfría y rehiela con facilidad a lo largo de la noche. A partir de media mañana podrán caer aludes de nieve húmeda en terreno muy pendiente soleado; serán de tamaño 1 (pequeña, pero suficiente para arrastrarnos), especialmente en puntos rocosos y afectando principalmente la nieve superficial de los últimos episodios. El humedecimiento se puede alargar hasta el anochecer por nubes bajas pegadas a las cimas. Hay que evitar el terreno donde la penetración de la bota o el esquí sean profundas, así como laderas en las que observamos caídas de purgas. En terreno muy umbrío las placas de viento formadas en la última nevada reposan sobre niveles de nieve granulada; además se pueden formar niveles de facetas por debajo de las placas. Al paso de un grupo de personas se podrían desencadenar aludes de placa de hasta tamaño 2 (suficiente para enterrar a una persona). Los puntos sensibles están allí donde la nieve no se encuentre encostrada.

Distribución del manto nivoso

El manto es esquiable a umbrías a partir de unos 1.800 m en umbrías. Los grosores son muy excedentarios para la época del año y en lugares no afectados por el viento oscilan entre 70-100 cm a unos 2.000 m, y más de 150 cm por encima de 2.400 m, muy variable por los efectos del viento. Debido a la fusión, van disminuyendo a razón de unos 4 cm por día.

Tendencia para las próximas 48-72h

A lo largo de la semana el humedecimiento durante las horas de máxima insolación seguirá siendo el principal problema a tener en cuenta. Peligro SIN CAMBIOS.

El próximo boletín será emitido el día 2026-04-09

5 MUY FUERTE	4 FUERTE	3 NOTABLE	2 LIMITADO	1 DÉBIL

EAWS EUROPEAN AVALANCHE WARNING SERVICES