Bulletin d'estimation du risque d'avalanche
(valable en dehors des pistes balisées et ouvertes)

MASSIF : Mercantour

Rédigé le mercredi 8 avril 2026 à 14h

Estimation des risques pour le : JEUDI 09 AVRIL

CONDITIONS PRINTANIÈRES. DÉPARTS EN NEIGE HUMIDE PARFOIS TRÈS VOLUMINEUX

3

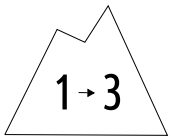

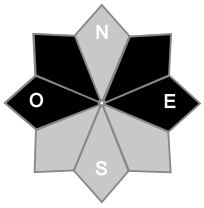

Indice de risque faible évoluant en marqué.

Départs spontanés : en neige humide, parfois de grande taille

Déclenchements provoqués : en neige humide sous les skis, parfois linéaires

Indices de risque : 5 très fort - 4 fort - 3 marqué - 2 limité - 1 faible -- En noir : les pentes les plus dangereuses

Stabilité du manteau neigeux

Situation avalancheuse typique : neige humide

Déclenchements provoqués : le manteau neigeux est bien stable le matin. Les déclenchements d'avalanches concernent les pentes raides ensoleillées. Elles peuvent être déclenchées par un seul skieur, et générer des avalanches de taille moyenne à grande (taille 2 à 3) en orientations ouest, nord-ouest, nord-est et est d'altitude, avec une cassure linéaire relativement large.
Les pentes plein nord de haute altitude sont moins dangereuses, l'humidification restant superficielle. Les pentes d'un large secteur sud sont en neige transformée jusqu'au fond, les déclenchements provoqués restent de petite taille.

Départs spontanés : peu probables au lever du jour avec le bon regel nocturne, puis activité en neige humide au fil de la journée en suivant la course du soleil. Départs nombreux au soleil, parfois linéaires et de taille moyenne à grande (taille 2 à 3) en orientations ouest ou est de haute altitude.

Qualité de la neige

Enneigement encore légèrement excédentaire pour un début avril.

Enneigement skiable généralement à partir de 1700 m en terrain favorable et 2200 m en adrets peu pentus.

État de la neige en surface : manteau neigeux printanier avec un bon regel nocturne le matin, s'humidifiant rapidement en journée. Neige restée sèche seulement en orientations raides et plein nord de haute altitude, mais généralement fortement durcie par le vent.

Aperçu météo pour le jeudi 09 avril

	nuit	matin	après-midi	soir
Toujours chaud, sec et très ensoleillé. Vent de nord-ouest faible à modéré.				
Pluie-Neige				
Iso 0 °C	3 500 m	3 400 m	3 400 m	3 500 m
Vent 2000 m	→ 10 km/h	↑ 10 km/h	↘ 15 km/h	↘ 20 km/h
Vent 3000 m	↘ 15 km/h	→ 20 km/h	→ 25 km/h	↘ 25 km/h

Épaisseur de neige hors-piste

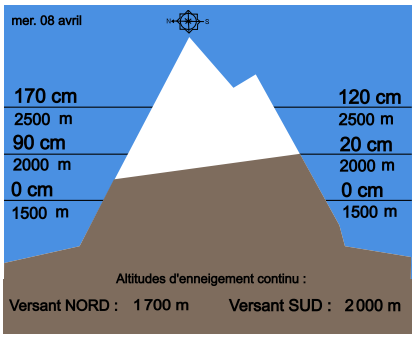

Précipitations à 1800 m

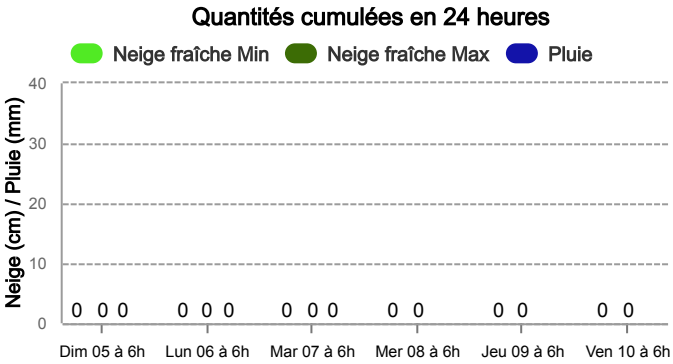

Tendance du vendredi 10 avril

3

Indice de risque marqué

Poursuite de conditions printanières et de l'humidification en profondeur du manteau neigeux. Grandes avalanches possibles. Risque restant marqué.

Pour consulter la vigilance en cours, veuillez vous rendre sur le site https://vigilance.meteofrance.fr/fr

Météo-France - 73 avenue de Paris, 94165 Saint-Mandé cedex - Contact : contact@meteo.fr

Rédigé par Météo-France avec la contribution des observateurs du réseau nivo-météorologiques. Partenariat : ANMSM (Maires de Stations de Montagne), DSF (Domaines Skiables de France), ADSP (Directeurs de Pistes et de la Sécurité des Stations de Sports d'Hiver) et autres acteurs de la montagne.

Bulletin neige & avalanches par téléphone au **0 892 68 10 20** Service 0,35 € / min + prix appel

RÉPUBLIQUE FRANÇAISE
Liberté Égalité Fraternité

METEO FRANCE
À VOS CÔTÉS, DANS UN CLIMAT QUI CHANGE

Bulletin d'estimation du risque d'avalanche

(valable en dehors des pistes balisées et ouvertes)

MASSIF : Mercantour

Rédigé le mercredi 8 avril 2026 à 14h

Conditions nivo-météo des 7 derniers jours

	jeu. 02/04				ven. 03/04				sam. 04/04				dim. 05/04				lun. 06/04				mar. 07/04				mer. 08/04			
	03h	09h	15h	21h	03h	09h	15h	21h	03h	09h	15h	21h	03h	09h	15h	21h	03h	09h	15h	21h	03h	09h	15h	21h	03h	09h	15h	21h
Météo																												
Vent (km/h)	55	35	35	30	25	25	40	35	15	10	20	10	20	25	30	35	30	20	20	15	20	20	25	10	10	15	15	10
à 3000m																												
Vent (km/h)	40	30	20	25	30	20	25	20	15	10	15	10	10	10	20	10	15	10	15	10	10	10	20	10	10	10	20	10
à 2000m																												

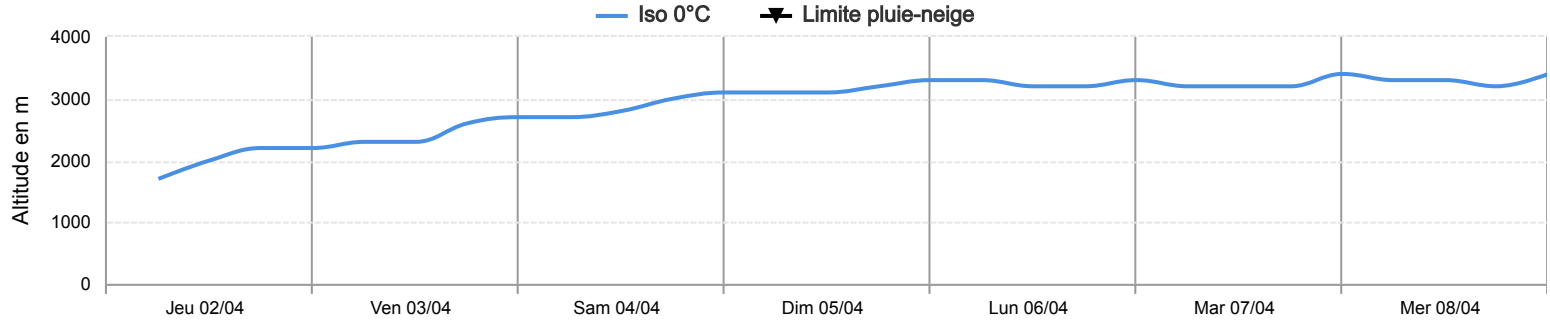

Neige fraîche à 06h

Jeu 02/04	Ven 03/04	Sam 04/04	Dim 05/04	Lun 06/04	Mar 07/04
0 cm	0 cm	0 cm	0 cm	0 cm	0 cm

Risque d'avalanche	jeu. 02/04	ven. 03/04	sam. 04/04	dim. 05/04	lun. 06/04	mar. 07/04	mer. 08/04
	2	1	2	2	2	2	2

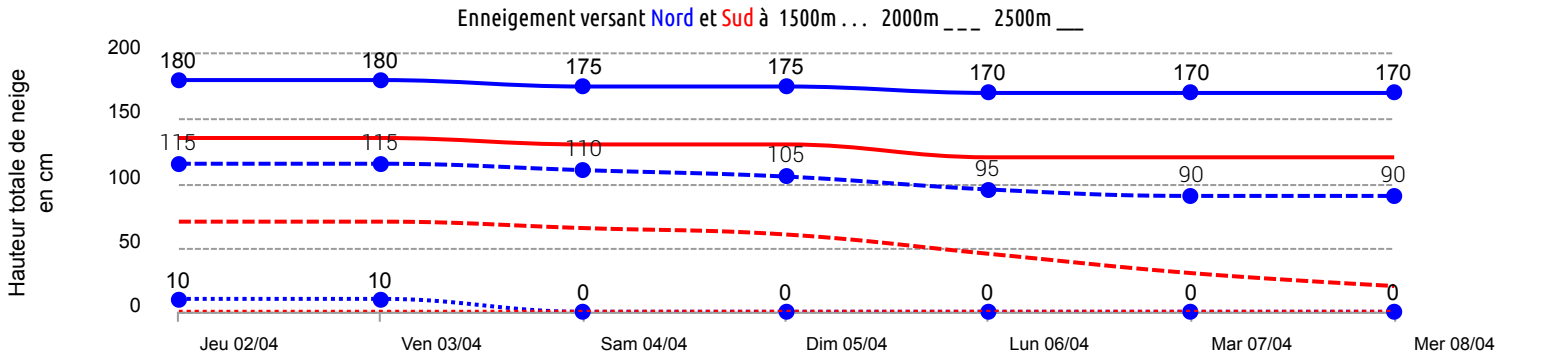

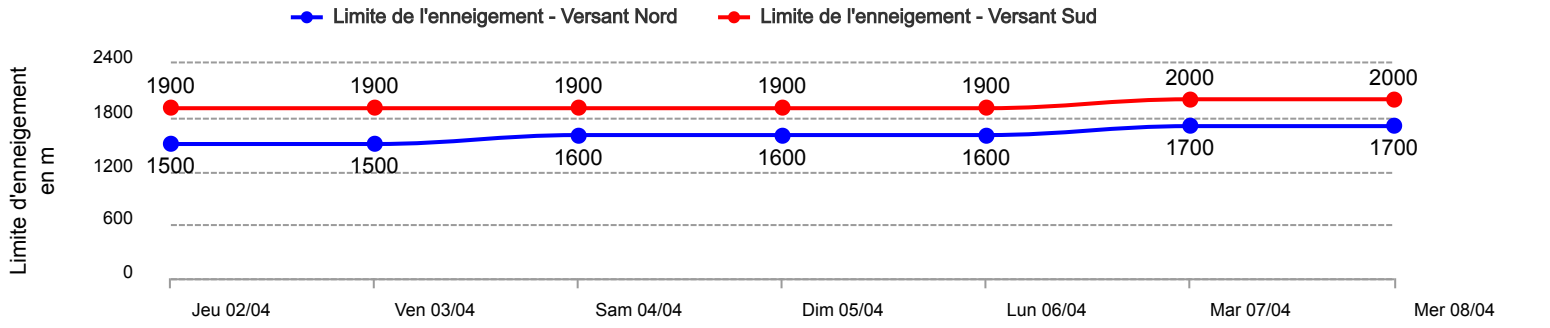

Pour consulter la vigilance en cours, veuillez vous rendre sur le site https://vigilance.meteofrance.fr/fr

Météo-France - 73 avenue de Paris, 94165 Saint-Mandé cedex - Contact : contact@meteo.fr

Rédigé par Météo-France avec la contribution des observateurs du réseau nivo-météorologiques. Partenariat : ANMSM (Maires de Stations de Montagne), DSF (Domaines Skiables de France), ADSP (Directeurs de Pistes et de la Sécurité des Stations de Sports d'Hiver) et autres acteurs de la montagne.

Bulletin neige & avalanches par téléphone au
0 892 68 10 20 Service 0,35 € / min + prix appel