Bulletin d'estimation du risque d'avalanche
(valable en dehors des pistes balisées et ouvertes)

MASSIF : Bauges

Rédigé le mercredi 8 avril 2026 à 16h

Estimation des risques pour le : JEUDI 09 AVRIL

LE PRINTEMPS S'INSTALLE

2

1 → 2

N O E S

Indice de risque faible évoluant en limité.

Départs spontanés : avalanches de neige humide

Déclenchements provoqués : avalanches de neige humide

Indices de risque : 5 très fort - 4 fort - 3 marqué - 2 limité - 1 faible -- En noir : les pentes les plus dangereuses

Stabilité du manteau neigeux

Situation avalancheuse typique : neige humide — avalanches de fond

Départs spontanés :
* **avalanches de neige humide**, rares au lever du jour, puis de plus en **plus nombreuses au fil du réchauffement** et du rayonnement solaire. En toutes orientations et altitudes, en particulier dans les zones près des rochers ou des falaises. Taille 1 à 2 (petite à moyenne) et rarement 3 (grande).
Observable : enfoncement piéton important, boulettes, escargots.
* quelques **plaques de fond** dans les zones herbeuses ou les dalles rocheuses, à toute heure du jour ou de la nuit. À toutes altitudes et orientations. Taille 2 (moyenne).

Déclenchements provoqués :
* **avalanches de neige humide**. Facile à déclencher au soleil. Départ ponctuel sous les skis, pouvant parfois déclencher, en cascade, une petite plaque. Taille 1 à 2 (petite à moyenne). Causé par le réchauffement et le rayonnement solaire.

Qualité de la neige

Enneigement :
Pour la saison, l'enneigement est correct.
On peut chausser les skis au-dessus de 1700/1800 m en sud et 1400/1500 m en nord.
Corniches fragilisées par le redoux.

Qualité de la neige ce jeudi :
En sud et en dessous de 2000 m en nord, manteau neigeux printanier. Humidification rapide et profonde au soleil.
Au-dessus de 2000 m en nord, croute de regel portante sur de la vielle neige dense, s'humidifiant un peu au soleil.

Aperçu météo pour le jeudi 09 avril

nuit	matin	après-midi	soir

Ensoleillé. Formation de quelques cumulus l'après-midi au dessus du relief. Températures maximales : à 2000 m 11°C et 14°C à 1500 m

Pluie-Neige				
Iso 0 °C	3 400 m	3 200 m	3 100 m	3 000 m
Vent 1500 m	5 km/h	5 km/h	10 km/h	15 km/h
Vent 2000 m	10 km/h	10 km/h	10 km/h	20 km/h

Épaisseur de neige hors-piste

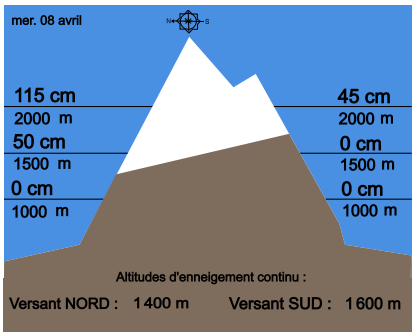

Précipitations à 1800 m

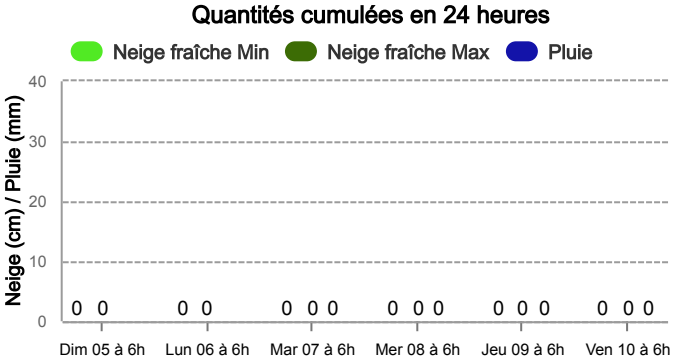

Tendance du vendredi 10 avril

2

Indice de risque limité

Vendredi : ciel voilé le matin et nombreux cumulus l'après-midi. Isotherme 0°C en baisse vers 2800 m.
⇒ le manteau neigeux continue de s'humidifier en profondeur. Encore des avalanches de neige humide et des départs en plaque de fond.

Pour consulter la vigilance en cours, veuillez vous rendre sur le site https://vigilance.meteofrance.fr/fr

Météo-France - 73 avenue de Paris, 94165 Saint-Mandé cedex - Contact : contact@meteo.fr

Rédigé par Météo-France avec la contribution des observateurs du réseau nivo-météorologiques. Partenariat : ANMSM (Maires de Stations de Montagne), DSF (Domaines Skiables de France), ADSP (Directeurs de Pistes et de la Sécurité des Stations de Sports d'Hiver) et autres acteurs de la montagne.

Bulletin neige & avalanches par téléphone au 0 892 68 10 20 Service 0,35 € / min + prix appel

RÉPUBLIQUE FRANÇAISE
Liberté Égalité Fraternité

METEO FRANCE
À VOS CÔTÉS, DANS UN CLIMAT QUI CHANGE

Bulletin d'estimation du risque d'avalanche

(valable en dehors des pistes balisées et ouvertes)

MASSIF : Bauges

Rédigé le mercredi 8 avril 2026 à 16h

Conditions nivo-météo des 7 derniers jours

	jeu. 02/04				ven. 03/04				sam. 04/04				dim. 05/04				lun. 06/04				mar. 07/04				mer. 08/04			
	03h	09h	15h	21h	03h	09h	15h	21h	03h	09h	15h	21h	03h	09h	15h	21h	03h	09h	15h	21h	03h	09h	15h	21h	03h	09h	15h	21h
Météo																												
Vent (km/h)	40	50	50	50	40	30	20	15	20	20	10	15	15	20	35	25	25	20	15	10	10	5	10	10	20	20	5	5
à 2000m																												
Vent (km/h)	20	30	40	40	30	20	15	10	15	10	5	5	10	15	20	15	15	10	10	5	10	0	5	10	10	15	5	5
à 1500m																												

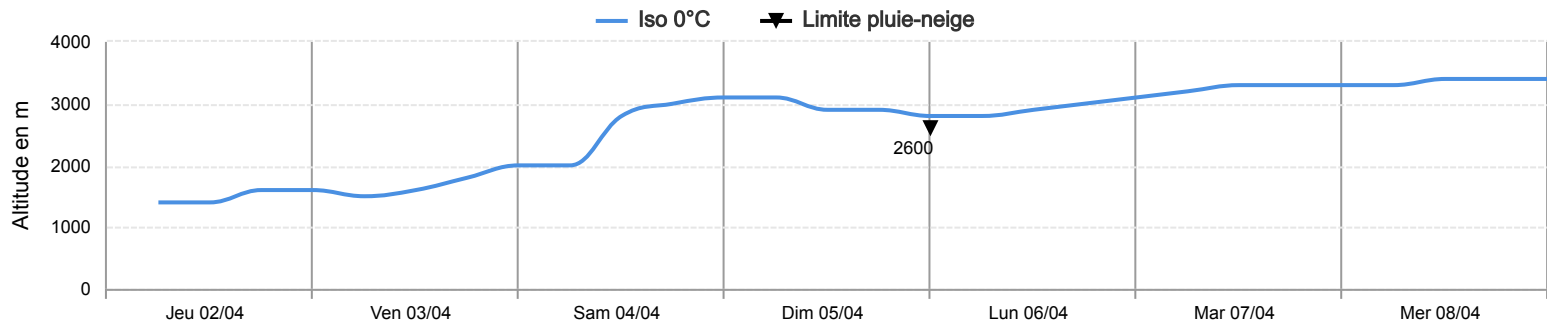

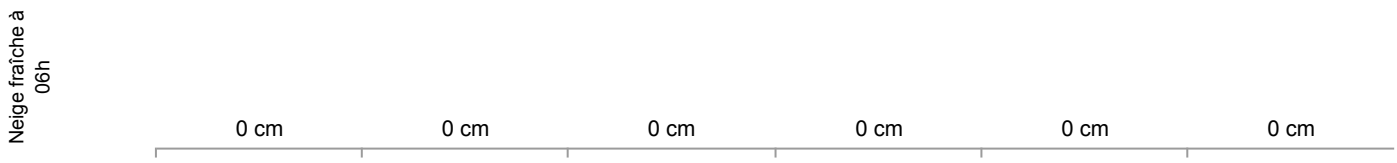

Risque d'avalanche	jeu. 02/04	ven. 03/04	sam. 04/04	dim. 05/04	lun. 06/04	mar. 07/04	mer. 08/04
	2	2	2	2	2	2	2

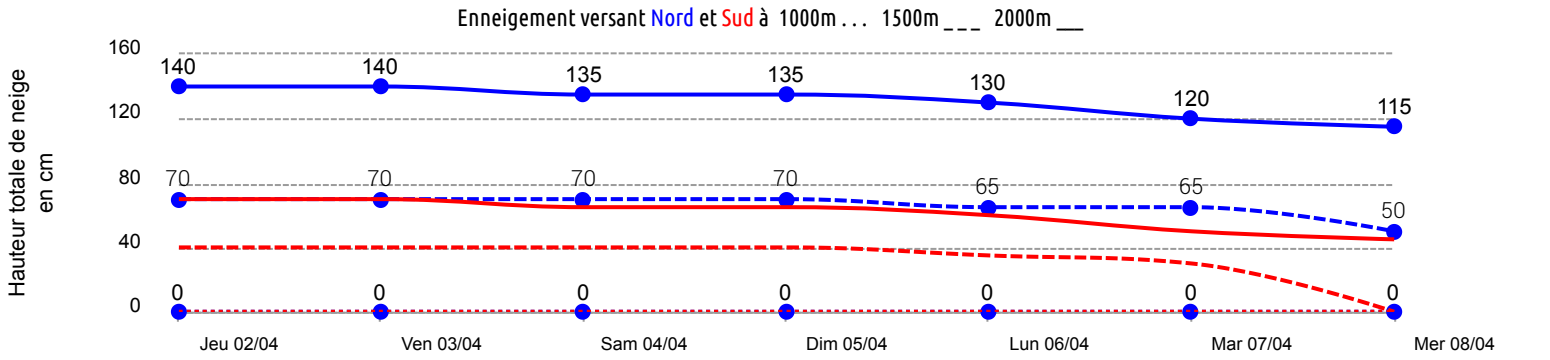

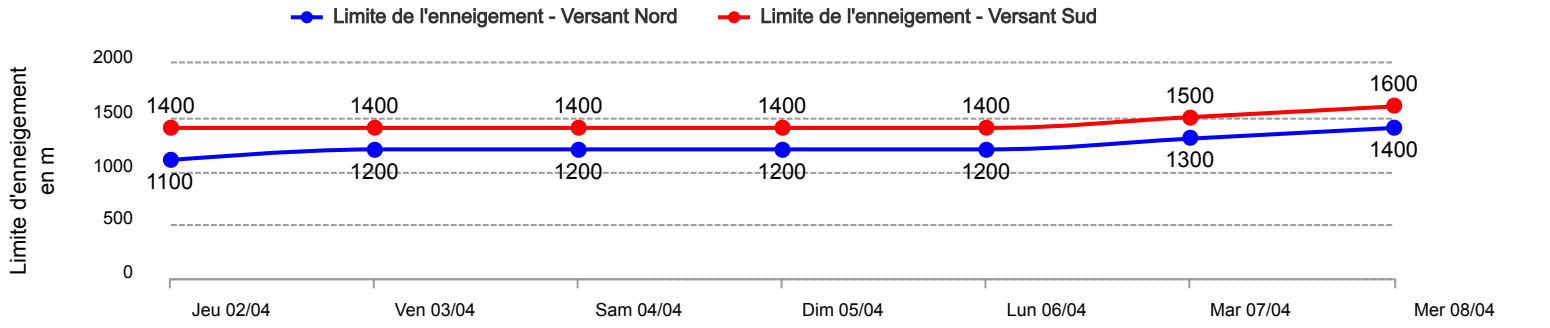

Pour consulter la vigilance en cours, veuillez vous rendre sur le site https://vigilance.meteofrance.fr/fr

Météo-France - 73 avenue de Paris, 94165 Saint-Mandé cedex - Contact : contact@meteo.fr

Rédigé par Météo-France avec la contribution des observateurs du réseau nivo-météorologiques. Partenariat : ANMSM (Maires de Stations de Montagne), DSF (Domaines Skiables de France), ADSP (Directeurs de Pistes et de la Sécurité des Stations de Sports d'Hiver) et autres acteurs de la montagne.

Bulletin neige & avalanches par téléphone au
0 892 68 10 20 Service 0,35 € / min + prix appel