# Bulletin d'estimation du risque d'avalanche

(valable en dehors des pistes balisées et ouvertes)

# MASSIF : Champsaur

Rédigé le mercredi 8 avril 2026 à 16h

## Estimation des risques pour le : JEUDI 09 AVRIL

**DÉPARTS DE NEIGE HUMIDE AU SOLEIL, GRANDES AVALANCHES POSSIBLES EN COURS DE JOURNÉE**

3

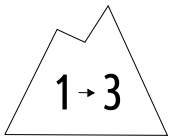


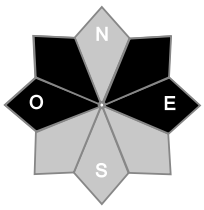


Indice de risque faible évoluant en marqué.

**Départs spontanés :** en neige humide au fil de l'ensoleillement, parfois volumineux.

**Déclenchements provoqués :** en neige humide sous les skis, parfois volumineux.

Indices de risque : 5 très fort - 4 fort - 3 marqué - 2 limité - 1 faible -- En noir : les pentes les plus dangereuses

## Stabilité du manteau neigeux

**Situation avalancheuse typique :** neige humide couche fragile persistante

**Départs spontanés** : peu probables en tout début de journée après un bon regel nocturne, puis reprise rapide de l'activité en neige humide au fil de la course du soleil. Départs généralement ponctuels en particulier en pentes raides près des rochers, engendrant des avalanches petites à moyennes (taille 1 à 2).
- des départs linéaires de grande taille sont possibles (taille 3), notamment dans les orientations est et ouest au-dessus de 2200/2400 m environ, quand l'humidification gagne en profondeur et atteint pour la première fois les couches fragiles persistantes enfouies à la base du manteau neigeux.

**Déclenchements provoqués** :
- Un skieur évoluant tardivement en pentes raides fortement humidifiées, peut provoquer des départs de neige humide sous les skis, engendrant des avalanches en poires de taille petites à moyennes (taille 1 à 2).
- Un départ linéaire de grande taille est possible (taille 3), notamment dans les orientations est et ouest au-dessus de 2200/2400 m environ, en cas de sollicitation de couches fragiles persistantes enfouies à la base du manteau neigeux. Départs avec cassures linéaires larges et épaisses, possibles au passage d'un skieur, notamment après un premier départ de surface.

## Qualité de la neige

**L'enneigement** est proche des normales ou excédentaire pour un début avril.
Hauteurs de neige observées : 105 cm à la Nivôse d'Orcières à 2280 m.

**Limite d'enneigement skiable** : vers 1400/1500 m en ubacs favorables (terrains herbeux, pistes forestières), 1800/1900 m en adrets pas trop raides.

**État de la neige de surface** : neige en cycle printanier. Après un bon regel nocturne, reprise rapide de l'humidification au soleil. Dans les ubacs raides au-dessus de 2500/2700 m, neige encore froide, souvent durcie ou travaillée par le vent dans les secteurs exposés, parfois plus légère dans les combes ou pentes abritées. Sur les crêtes, d'épaisses corniches côtoient des zones pelées par le vent.

## Aperçu météo pour le jeudi 09 avril

| | nuit | matin | après-midi | soir |
|---|---|---|---|---|
| | | | | |

Temps doux et ensoleillé, quelques cumulus bourgeonnent sur le relief l'après-midi.

| Pluie-Neige | | | | |
|---|---|---|---|---|
| Iso 0 °C | 3 500 m | 3 500 m | 3 400 m | 3 400 m |
| Vent 2000 m | ← 5 km/h | ↘ 5 km/h | ↘ 15 km/h | ↓ 15 km/h |
| Vent 3000 m | ↘ 10 km/h | ↘ 10 km/h | ↓ 20 km/h | ↓ 25 km/h |

## Épaisseur de neige hors-piste

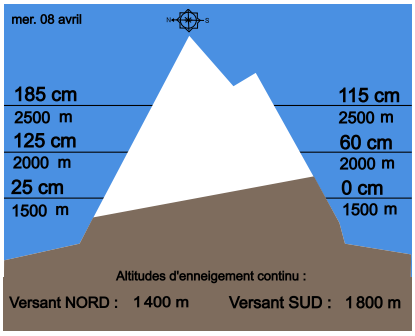


## Précipitations à 1800 m

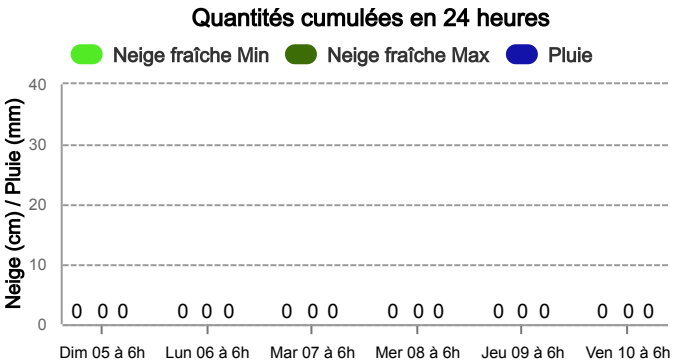


## Tendance du vendredi 10 avril

3

**Indice de risque marqué**

Le manteau neigeux printanier continue de s'humidifier de plus en plus profondément. Avalanches de grande taille possibles l'après-midi, notamment en versant est et ouest.

Pour consulter la vigilance en cours, veuillez vous rendre sur le site https://vigilance.meteofrance.fr/fr

Météo-France - 73 avenue de Paris, 94165 Saint-Mandé cedex - Contact : contact@meteo.fr

Rédigé par Météo-France avec la contribution des observateurs du réseau nivo-météorologiques. Partenariat : ANMSM (Maires de Stations de Montagne), DSF (Domaines Skiables de France), ADSP (Directeurs de Pistes et de la Sécurité des Stations de Sports d'Hiver) et autres acteurs de la montagne.

Bulletin neige & avalanches par téléphone au

**0 892 68 10 20** Service 0,35 € / min + prix appel

# Bulletin d'estimation du risque d'avalanche

(valable en dehors des pistes balisées et ouvertes)

# MASSIF : Champsaur

Rédigé le mercredi 8 avril 2026 à 16h

## Conditions nivo-météo des 7 derniers jours

| | jeu. 02/04 | | | | ven. 03/04 | | | | sam. 04/04 | | | | dim. 05/04 | | | | lun. 06/04 | | | | mar. 07/04 | | | | mer. 08/04 | | | |
|---|---|---|---|---|---|---|---|---|---|---|---|---|---|---|---|---|---|---|---|---|---|---|---|---|---|---|---|---|
| | 03h | 09h | 15h | 21h | 03h | 09h | 15h | 21h | 03h | 09h | 15h | 21h | 03h | 09h | 15h | 21h | 03h | 09h | 15h | 21h | 03h | 09h | 15h | 21h | 03h | 09h | 15h | 21h |
| Météo | | | | | | | | | | | | | | | | | | | | | | | | | | | | |
| Vent (km/h) | 50 | 20 | 30 | 30 | 30 | 20 | 20 | 15 | 20 | 10 | 10 | 10 | 10 | 10 | 20 | 25 | 25 | 15 | 15 | 10 | 10 | 10 | 10 | 10 | 10 | 10 | 10 | 10 |
| à 3000m | | | | | | | | | | | | | | | | | | | | | | | | | | | | |
| Vent (km/h) | 25 | 15 | 20 | 15 | 10 | 15 | 15 | 10 | 5 | 5 | 10 | 5 | 5 | 5 | 10 | 10 | 10 | 10 | 10 | 5 | 5 | 5 | 10 | 5 | 5 | 5 | 10 | 5 |
| à 2000m | | | | | | | | | | | | | | | | | | | | | | | | | | | | |

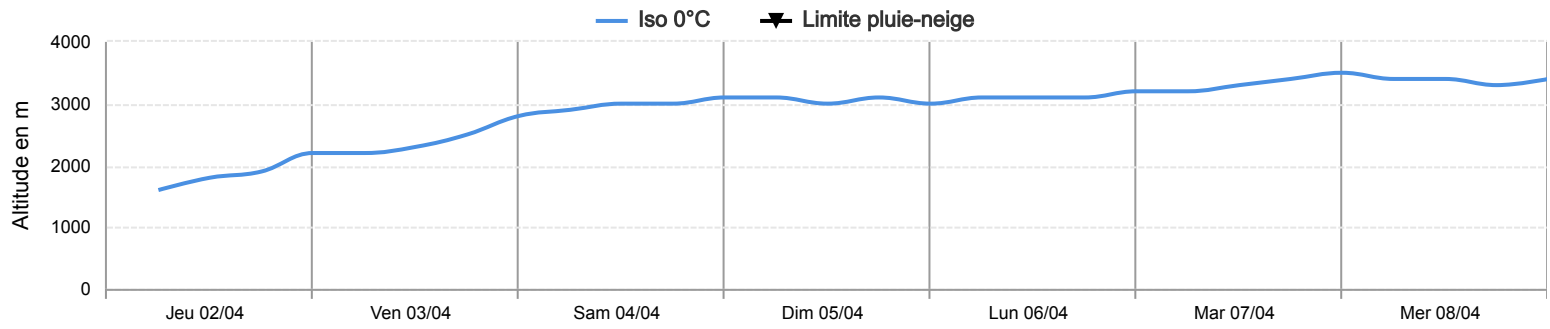


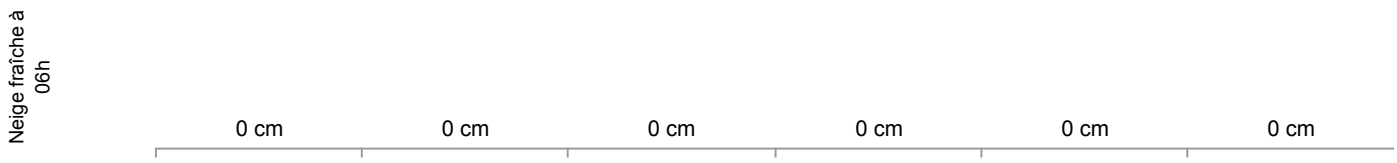


| Risque d'avalanche | jeu. 02/04 | ven. 03/04 | sam. 04/04 | dim. 05/04 | lun. 06/04 | mar. 07/04 | mer. 08/04 |
|---|---|---|---|---|---|---|---|
| | 2 | 2 | 2 | 2 | 2 | 2 | 2 |

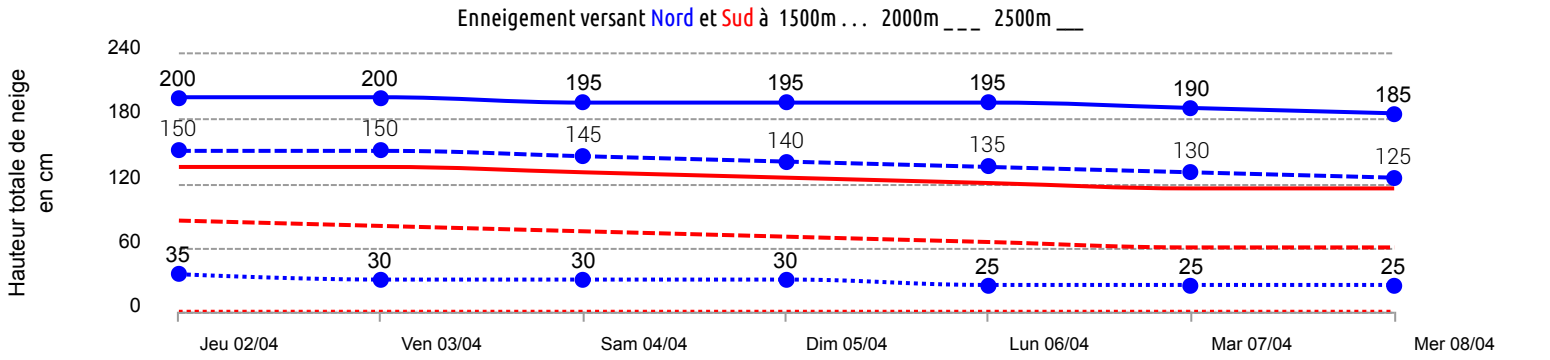


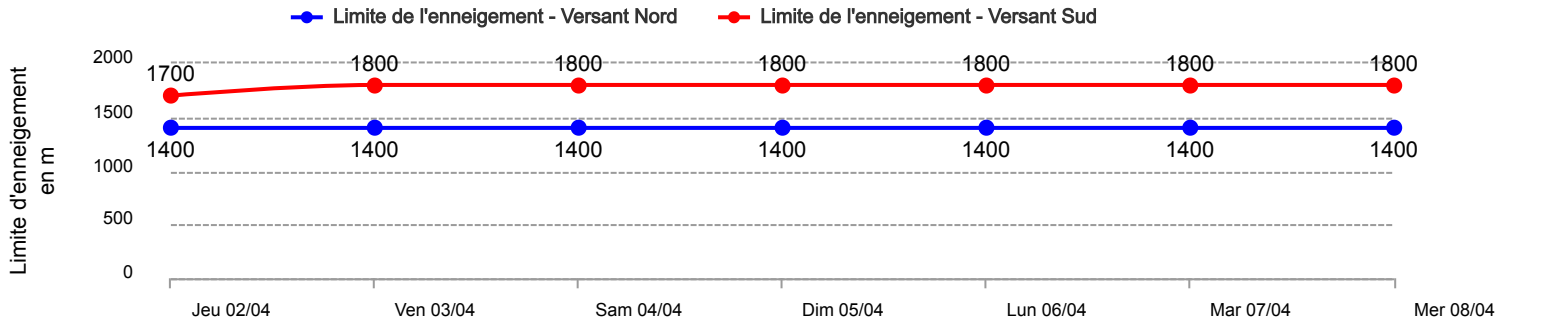


Pour consulter la vigilance en cours, veuillez vous rendre sur le site https://vigilance.meteofrance.fr/fr


Météo-France - 73 avenue de Paris, 94165 Saint-Mandé cedex - Contact : contact@meteo.fr


Bulletin neige & avalanches par téléphone au

0 892 68 10 20 Service 0,35 € / min + prix appel


Rédigé par Météo-France avec la contribution des observateurs du réseau nivo-météorologiques. Partenariat : ANMSM (Maires de Stations de Montagne), DSF (Domaines Skiables de France), ADSP (Directeurs de Pistes et de la Sécurité des Stations de Sports d'Hiver) et autres acteurs de la montagne.