Bulletin d'estimation du risque d'avalanche
(valable en dehors des pistes balisées et ouvertes)

MASSIF : Embrunais Parpaillon

Rédigé le mercredi 8 avril 2026 à 16h

Estimation des risques pour le : JEUDI 09 AVRIL

DÉPARTS DE NEIGE HUMIDE AU SOLEIL, GRANDES AVALANCHES POSSIBLES EN COURS DE JOURNÉE

3

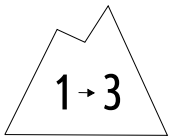

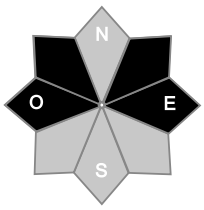

Indice de risque faible évoluant en marqué.

Départs spontanés : en neige humide au fil de l'ensoleillement, parfois volumineux.

Déclenchements provoqués : en neige humide sous les skis, parfois volumineux.

Indices de risque : 5 très fort - 4 fort - 3 marqué - 2 limité - 1 faible -- En noir : les pentes les plus dangereuses

Stabilité du manteau neigeux

Situation avalancheuse typique : neige humide couche fragile persistante

Départs spontanés : peu probables en tout début de journée après un bon regel nocturne, puis reprise rapide de l'activité en neige humide au fil de la course du soleil. Départs généralement ponctuels en particulier en pentes raides près des rochers, engendrant des avalanches petites à moyennes (taille 1 à 2).
- des départs linéaires de grande taille sont possibles (taille 3), notamment dans les orientations est et ouest au-dessus de 2200/2400 m environ, quand l'humidification gagne en profondeur et atteint pour la première fois les couches fragiles persistantes enfouies à la base du manteau neigeux.

Déclenchements provoqués :
- Un skieur évoluant tardivement en pentes raides fortement humidifiées, peut provoquer des départs de neige humide sous les skis, engendrant des avalanches en poires de taille petites à moyennes (taille 1 à 2).
- Un départ linéaire de grande taille est possible (taille 3), notamment dans les orientations est et ouest au-dessus de 2200/2400 m environ, en cas de sollicitation de couches fragiles persistantes enfouies à la base du manteau neigeux. Départs avec cassures linéaires larges et épaisses, possibles au passage d'un skieur, notamment après un premier départ de surface.

Qualité de la neige

L'enneigement est proche des normales pour un début avril.
Hauteurs de neige observées : 92 cm à la Nivôse du Parpaillon à 2500 m.

Limite d'enneigement skiable : au plus bas à 1500/1600 m en ubacs bien protégés ou sur pistes forestières, plutôt 2000/2100 m en adrets.

État de la neige de surface : neige en cycle printanier. Après un bon regel nocturne, reprise rapide de l'humidification au soleil. Dans les ubacs raides au-dessus de 2500/2700 m, neige encore froide, souvent durcie ou travaillée par le vent dans les secteurs exposés, parfois plus légère dans les combes ou pentes abritées. Sur les crêtes, d'épaisses corniches côtoient des zones pelées par le vent.

Aperçu météo pour le jeudi 09 avril

	nuit	matin	après-midi	soir
Temps doux et ensoleillé, quelques cumulus bourgeonnent sur le relief l'après-midi.				
Pluie-Neige				
Iso 0 °C	3 500 m	3 400 m	3 400 m	3 400 m
Vent 2000 m	↖ 10 km/h	← 5 km/h	↗ 20 km/h	← 15 km/h
Vent 3000 m	↓ 10 km/h	↘ 20 km/h	↘ 20 km/h	↓ 20 km/h

Épaisseur de neige hors-piste

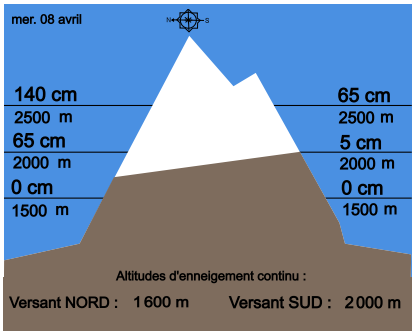

Précipitations à 1800 m

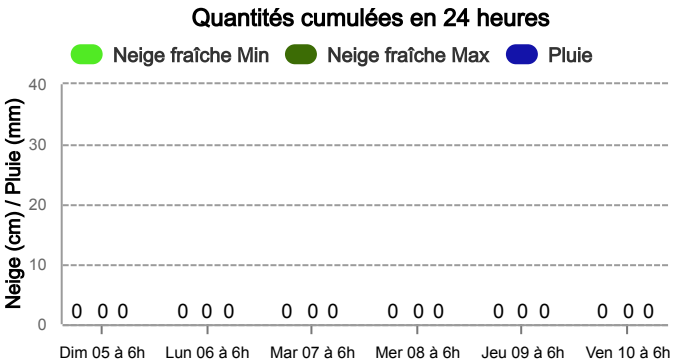

Tendance du vendredi 10 avril

3

Indice de risque marqué

Le manteau neigeux printanier continue de s'humidifier de plus en plus profondément. Avalanches de grande taille possibles l'après-midi, notamment en versant est et ouest.

Pour consulter la vigilance en cours, veuillez vous rendre sur le site https://vigilance.meteofrance.fr/fr

Météo-France - 73 avenue de Paris, 94165 Saint-Mandé cedex - Contact : contact@meteo.fr

Rédigé par Météo-France avec la contribution des observateurs du réseau nivo-météorologiques. Partenariat : ANMSM (Maires de Stations de Montagne), DSF (Domaines Skiables de France), ADSP (Directeurs de Pistes et de la Sécurité des Stations de Sports d'Hiver) et autres acteurs de la montagne.

Bulletin neige & avalanches par téléphone au
0 892 68 10 20 Service 0,35 € / min + prix appel

RÉPUBLIQUE FRANÇAISE
Liberté Égalité Fraternité

METEO FRANCE
À VOS CÔTÉS, DANS UN CLIMAT QUI CHANGE

Bulletin d'estimation du risque d'avalanche

(valable en dehors des pistes balisées et ouvertes)

MASSIF : Embrunais Parpaillon

Rédigé le mercredi 8 avril 2026 à 16h

Conditions nivo-météo des 7 derniers jours

	jeu. 02/04				ven. 03/04				sam. 04/04				dim. 05/04				lun. 06/04				mar. 07/04				mer. 08/04			
	03h	09h	15h	21h	03h	09h	15h	21h	03h	09h	15h	21h	03h	09h	15h	21h	03h	09h	15h	21h	03h	09h	15h	21h	03h	09h	15h	21h
Météo																												
Vent (km/h)	50	30	25	15	25	40	30	30	20	20	10	10	10	15	20	25	30	20	15	10	10	5	10	15	10	10	5	10
à 3000m																												
Vent (km/h)	25	15	25	15	15	15	15	10	10	10	15	10	5	10	20	10	10	10	20	10	10	5	20	10	5	10	15	10
à 2000m																												

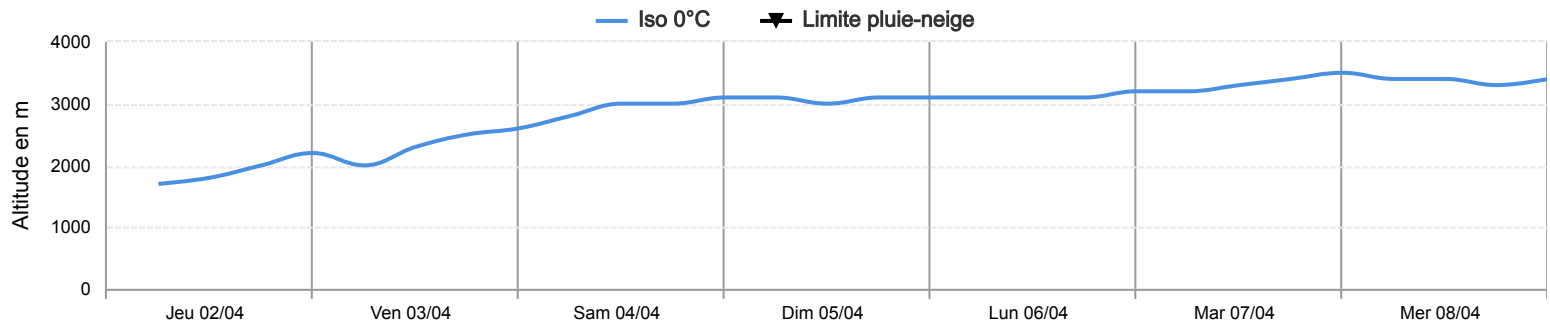

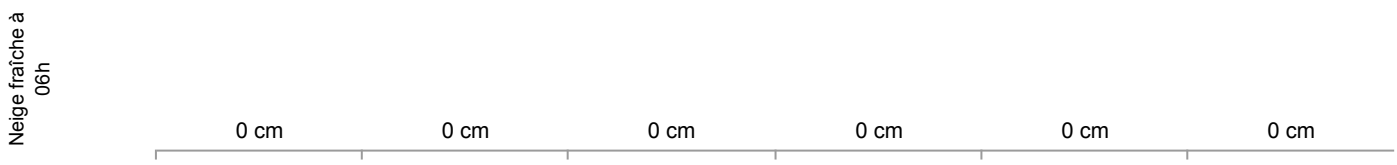

Risque d'avalanche	jeu. 02/04	ven. 03/04	sam. 04/04	dim. 05/04	lun. 06/04	mar. 07/04	mer. 08/04
	2	1	2	2	2	2	2

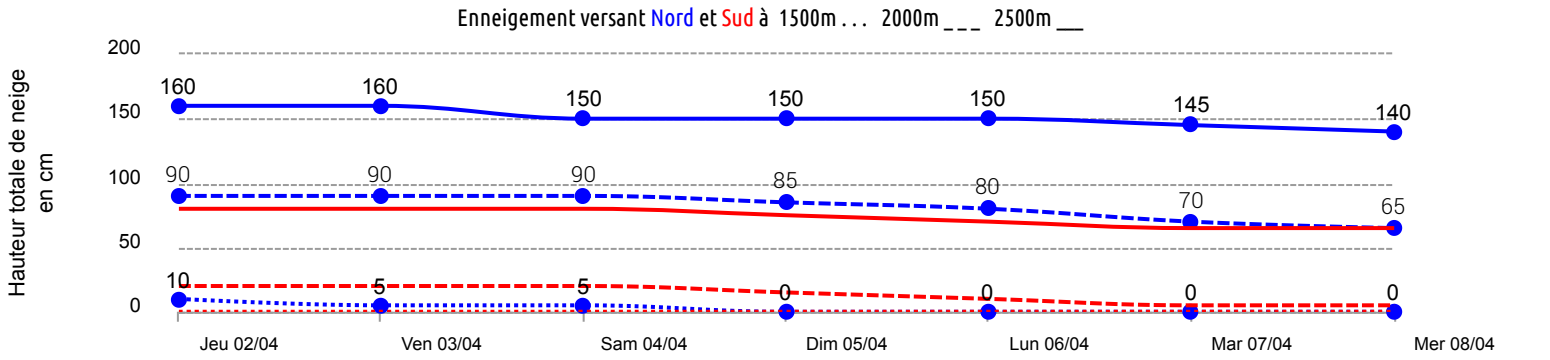

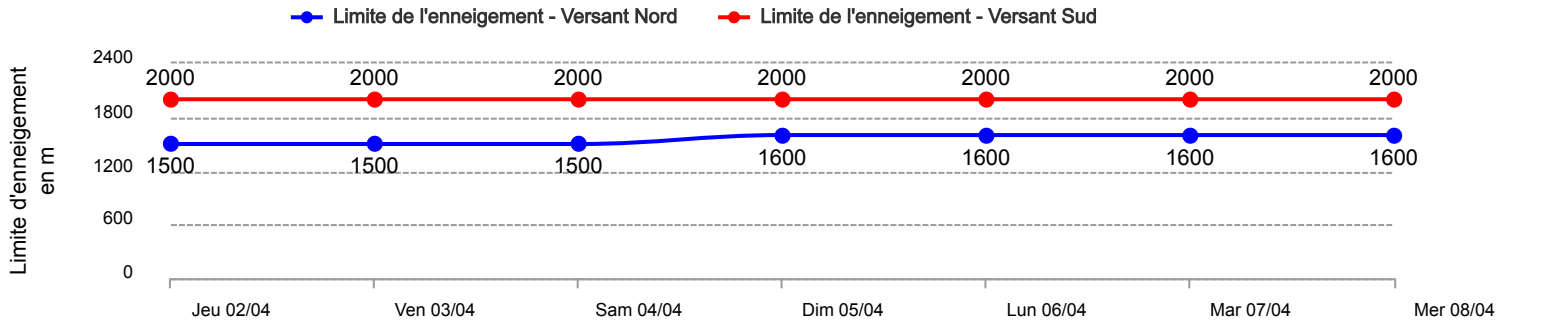

Pour consulter la vigilance en cours, veuillez vous rendre sur le site https://vigilance.meteofrance.fr/fr

Météo-France - 73 avenue de Paris, 94165 Saint-Mandé cedex - Contact : contact@meteo.fr

Bulletin neige & avalanches par téléphone au

0 892 68 10 20 Service 0,35 € / min + prix appel

Rédigé par Météo-France avec la contribution des observateurs du réseau nivo-météorologiques. Partenariat : ANMSM (Maires de Stations de Montagne), DSF (Domaines Skiables de France), ADSP (Directeurs de Pistes et de la Sécurité des Stations de Sports d'Hiver) et autres acteurs de la montagne.