RÉPUBLIQUE FRANÇAISE
Liberté Égalité Fraternité

METEO FRANCE
À VOS CÔTÉS, DANS UN CLIMAT QUI CHANGE

Bulletin d'estimation du risque d'avalanche
(valable en dehors des pistes balisées et ouvertes)
MASSIF : Haute-Ariege

Rédigé le mercredi 8 avril 2026 à 16h

Estimation des risques pour le : JEUDI 09 AVRIL

PROGRESSION DE L'HUMIDIFICATION; QUELQUES PLAQUES ENCORE PRÉSENTES EN VERSANTS FROIDS.

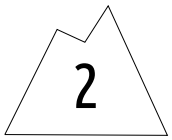

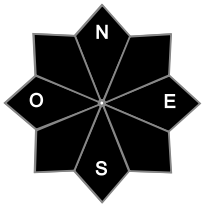

Indice de risque limité.

Départs spontanés : Reprise de l'activité en neige humide au fil de l'ensoleillement

Déclenchements provoqués : Plaques en versants froids d'altitude, en voie de stabilisation

Indices de risque : 5 très fort - 4 fort - 3 marqué - 2 limité - 1 faible -- En noir : les pentes les plus dangereuses

Stabilité du manteau neigeux

Situation avalancheuse typique : neige humide couche fragile persistante

Départs spontanés :
- Départs ponctuels en neige humide de taille petite à moyenne au fil de la journée et de l'ensoleillement dans presque toutes les orientations et jusqu'en altitude. Seules les faces nord raides de très haute montagne sont susceptibles encore d'y échapper.
Observables : boulettes, 'escargots', enfoncement du ski en profondeur.
- Des avalanches de fond de taille petite à moyenne sont possibles dans les pentes herbeuses ou sur des dalles rocheuses lisses en toutes orientations, plutôt l'après-midi.
Observables : fissures, reptations récentes.

Déclenchements provoqués :
- Dans les versants froids d'altitude (nord-ouest, nord, nord-est, au dessus de 2500/2600m), peuvent subsister quelques structures de plaques encore localement déclenchables au passage d'un pratiquant. Pas encore totalement stabilisées, elles peuvent occasionner des avalanches moyennes, voire grandes dans les zones de plus fortes accumulations.
Observables : Avalanches récentes, aspect venté de la surface et accumulations locales.
- Ailleurs, un pratiquant peut provoquer un départ ponctuel en surface dans la neige humide en coupant une pente raide déjà bien humidifiée.

Autre : Corniches et ponts de neige encore présents fragilisés en journée par l'humidification.

Qualité de la neige

Enneigement :
L'enneigement est excellent pour la saison, un des meilleurs des 30 dernières années. Les derniers cumuls conséquents en altitude côtoient des crêtes et sommets exposés au vent d'ouest à nord-ouest souvent assez dégarnis. La neige fond progressivement avec la douceur, mais la neige est visible dès 1400/1500 m dans certains secteurs ombragés et en fond de vallée. On chausse le plus souvent à partir de 1500/1600 m en nord, 1600/1700 m en sud sur une couche de neige rapidement plus épaisse.

Qualité de la neige :
Jeudi matin, le regel devrait être efficace avec une neige dure et portante au-dessus de 2200m environ, plus aléatoire en dessous, avec une croute parfois peu épaisse et non portante. On doit encore pouvoir trouver de la neige poudreuse dans de rares combes d'altitude abritées du vent plutôt en nord-est. Là où le vent a soufflé, la neige est plus dure et bien tassée.
En journée, reprise de l'humidification pratiquement jusqu'en haut des massifs. Au fil de l'ensoleillement, on trouvera une couche profonde de neige humide et gorgée d'eau au soleil dans les versants Est à Ouest en passant par le Sud, ainsi que dans les versants Nord en dessous de 2500 m environ.

Aperçu météo pour le jeudi 09 avril

	nuit	matin	après-midi	soir
Poursuite du beau temps				
Pluie-Neige				
Iso 0 °C	3300 m	3300 m	3300 m	3200 m
Vent 2000 m	↗ 10 km/h	↓ 10 km/h	↘ 10 km/h	↗ 15 km/h
Vent 3000 m	↑ 20 km/h	↙ 15 km/h	↓ 15 km/h	↓ 10 km/h

Pour consulter la vigilance en cours, veuillez vous rendre sur le site https://vigilance.meteofrance.fr/fr

Météo-France - 73 avenue de Paris, 94165 Saint-Mandé cedex - Contact : contact@meteo.fr

Rédigé par Météo-France avec la contribution des observateurs du réseau nivo-météorologiques. Partenariat : ANMSM (Maires de Stations de Montagne), DSF (Domaines Skiables de France), ADSP (Directeurs de Pistes et de la Sécurité des Stations de Sports d'Hiver) et autres acteurs de la montagne.

Bulletin neige & avalanches par téléphone au
0 892 68 10 20 Service 0,35 € / min + prix appel

RÉPUBLIQUE FRANÇAISE
Liberté Égalité Fraternité

METEO FRANCE
À VOS CÔTÉS, DANS UN CLIMAT QUI CHANGE

Bulletin d'estimation du risque d'avalanche

(valable en dehors des pistes balisées et ouvertes)

MASSIF : Haute-Ariege

Rédigé le mercredi 8 avril 2026 à 16h

Épaisseur de neige hors-piste

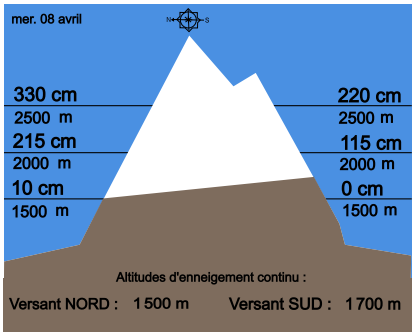

Précipitations à 1800 m

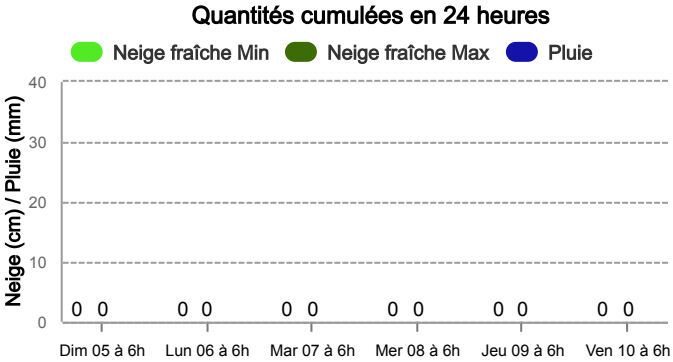

Tendance du vendredi 10 avril

Indice de risque limité

Peu d'évolution pour vendredi avec des journées qui se ressemblent.

Pour consulter la vigilance en cours, veuillez vous rendre sur le site https://vigilance.meteofrance.fr/fr

Météo-France - 73 avenue de Paris, 94165 Saint-Mandé cedex - Contact : contact@meteo.fr

Rédigé par Météo-France avec la contribution des observateurs du réseau nivo-météorologiques. Partenariat : ANMSM (Maires de Stations de Montagne), DSF (Domaines Skiables de France), ADSP (Directeurs de Pistes et de la Sécurité des Stations de Sports d'Hiver) et autres acteurs de la montagne.

Bulletin neige & avalanches par téléphone au

0 892 68 10 20 Service 0,35 € / min + prix appel

RÉPUBLIQUE FRANÇAISE
Liberté Égalité Fraternité

METEO FRANCE
À VOS CÔTÉS, DANS UN CLIMAT QUI CHANGE

Bulletin d'estimation du risque d'avalanche

(valable en dehors des pistes balisées et ouvertes)

MASSIF : Haute-Ariege

Rédigé le mercredi 8 avril 2026 à 16h

Conditions nivo-météo des 7 derniers jours

	jeu. 02/04				ven. 03/04				sam. 04/04				dim. 05/04				lun. 06/04				mar. 07/04				mer. 08/04			
	03h	09h	15h	21h	03h	09h	15h	21h	03h	09h	15h	21h	03h	09h	15h	21h	03h	09h	15h	21h	03h	09h	15h	21h	03h	09h	15h	21h
Météo																												
Vent (km/h)	75	70	75	75	55	40	35	40	40	35	25	20	15	10	15	15	15	20	35	30	30	25	20	20	30	35	35	25
à 3000m																												
Vent (km/h)	60	50	55	50	30	15	15	10	20	15	15	15	10	5	10	10	10	15	25	20	20	15	15	10	20	20	20	15
à 2000m																												

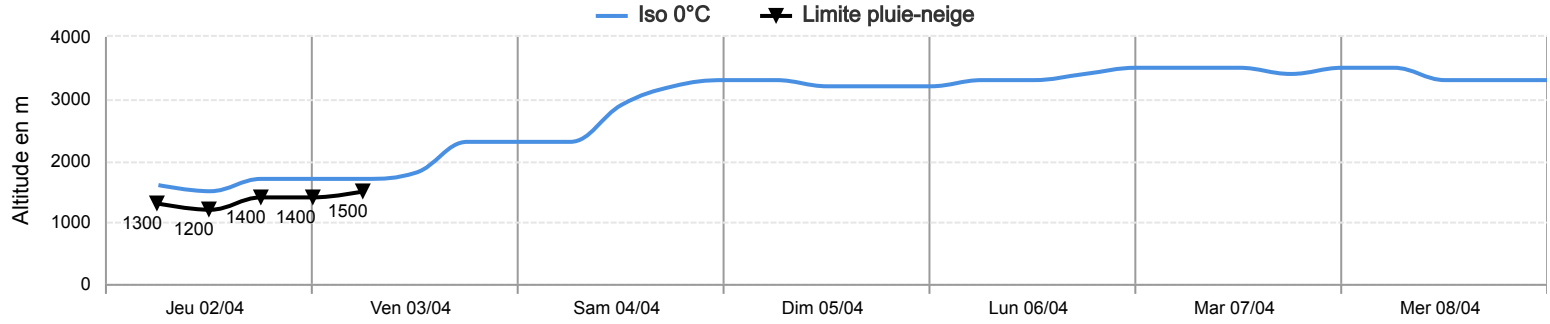

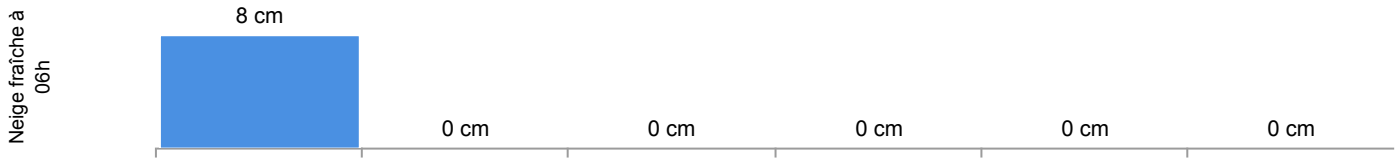

Risque d'avalanche	jeu. 02/04	ven. 03/04	sam. 04/04	dim. 05/04	lun. 06/04	mar. 07/04	mer. 08/04
	4	4	3	2	2	2	2

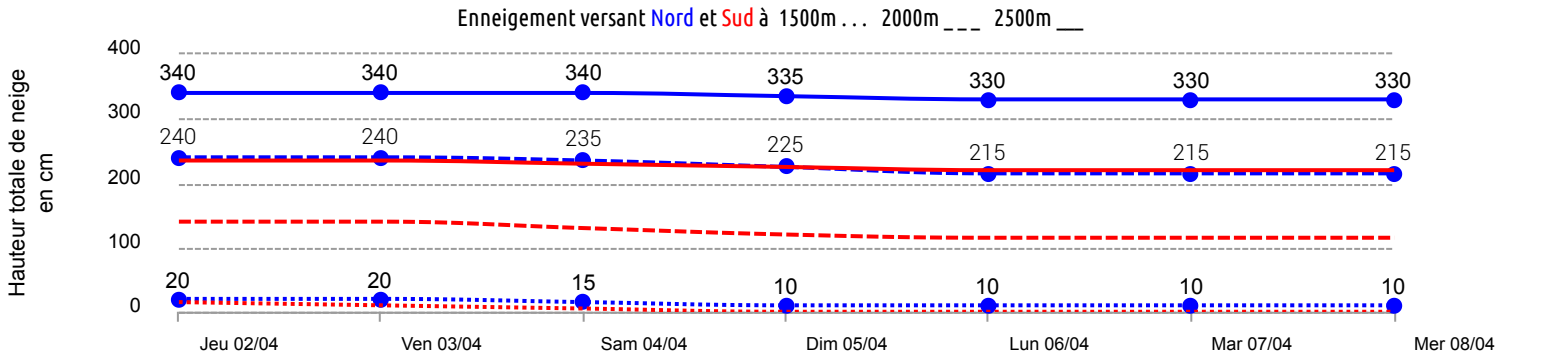

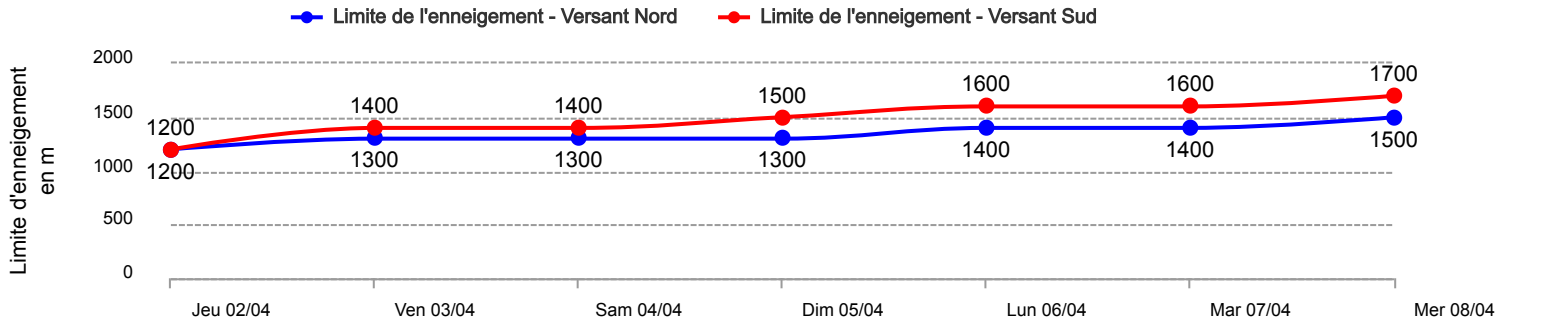

Pour consulter la vigilance en cours, veuillez vous rendre sur le site https://vigilance.meteofrance.fr/fr

Météo-France - 73 avenue de Paris, 94165 Saint-Mandé cedex - Contact : contact@meteo.fr

Bulletin neige & avalanches par téléphone au

0 892 68 10 20 Service 0,35 € / min + prix appel

Rédigé par Météo-France avec la contribution des observateurs du réseau nivo-météorologiques. Partenariat : ANMSM (Maires de Stations de Montagne), DSF (Domaines Skiables de France), ADSP (Directeurs de Pistes et de la Sécurité des Stations de Sports d'Hiver) et autres acteurs de la montagne.