Bulletin d'estimation du risque d'avalanche
(valable en dehors des pistes balisées et ouvertes)

MASSIF : Chartreuse

Rédigé le mercredi 8 avril 2026 à 17h

Estimation des risques pour le : JEUDI 09 AVRIL

HUMIDIFICATION DU MANTEAU NEIGEUX EN TOUS VERSANTS

2

2

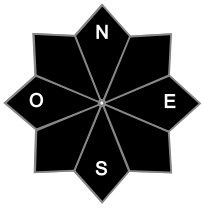

neige humide

Indice de risque limité.

Départs spontanés : Possibles avalanches en pentes raides/humidifiées, possibles en toutes orientations même en secteur Nord. Rare avalanche de glissement de taille 2 à 3 non exclue.

Déclenchements provoqués : En versants ensoleillés, possibles coulées ponctuelles sous les skis.

Indices de risque : 5 très fort - 4 fort - 3 marqué - 2 limité - 1 faible -- En noir : les pentes les plus dangereuses

Stabilité du manteau neigeux

Situation avalancheuse typique : neige humide — avalanches de fond

Départs spontanés : - Après un bon regel nocturne, de nouvelles avalanches humides peuvent se produire ce jeudi dès la matinée, notamment dans les pentes réchauffées par le soleil, le plus souvent de taille 1 à 2. Dans un rare cas, une avalanche de glissement plus conséquente, au terrain, atteignant la taille 2 à 3, ne peut être exclue (alpage raide). Ces problématiques augmente au fil des heures au gré du parcours du soleil et du réchauffement des pentes. (Sud-est à Est le matin jusquà Ouest Sud-ouest en fin de journée).
- Une rupture spontanée de corniche est également possible l'après-midi et à surveiller dans les secteurs concernés.

Déclenchements provoqués : En pentes soutenues et bien humidifiées, le pratiquant pourrait faire couler la neige humide sous les skis.

Autres : A l'ombre (le matin surtout) neige souvent très dure ou croutée par le regel. Surfaces glissantes généralisées.

Qualité de la neige

Qualification de l'enneigement : La fonte s'accélère, mais l'enneigement reste encore correct dès la moyenne altitude, et même très bon vers les hauteurs.

Limites skiables : Vers 1300/1500m en Nord, 1700/2100m au soleil...

Qualité de la neige jeudi : Neige printanière, bon regel nocturne, puis rapide humidification en journée, dans tous les versants. En Nord d'altitude toutefois, la neige peut encore être croutée/cassante le matin avec des restes de congères/effets du vent..

Aperçu météo pour le jeudi 09 avril

	nuit	matin	après-midi	soir

Encore une journée très ensoleillée et douce après un bon regel cette nuit.

Pluie-Neige				
Iso 0 °C	3 500 m	3 400 m	3 300 m	3 100 m
Vent 1500 m	5 km/h	5 km/h	15 km/h	20 km/h
Vent 2000 m	10 km/h	10 km/h	20 km/h	30 km/h

Épaisseur de neige hors-piste

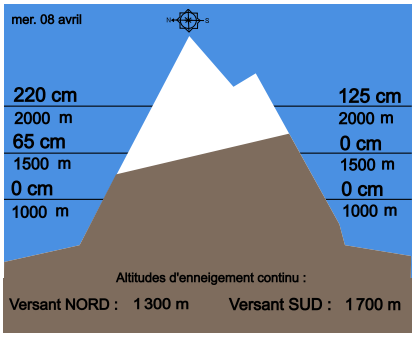

Précipitations à 1800 m

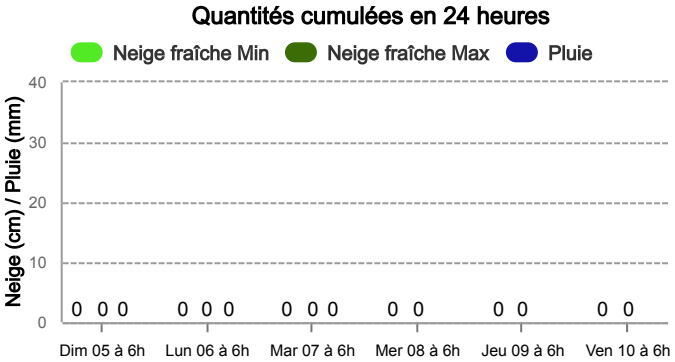

Tendance du vendredi 10 avril

2

Indice de risque limité

Peu d'évolutions avec un météo toujours stabble et une humidification progressive du manteau.

Pour consulter la vigilance en cours, veuillez vous rendre sur le site https://vigilance.meteofrance.fr/fr

Météo-France - 73 avenue de Paris, 94165 Saint-Mandé cedex - Contact : contact@meteo.fr

Rédigé par Météo-France avec la contribution des observateurs du réseau nivo-météorologiques. Partenariat : ANMSM (Maires de Stations de Montagne), DSF (Domaines Skiables de France), ADSP (Directeurs de Pistes et de la Sécurité des Stations de Sports d'Hiver) et autres acteurs de la montagne.

Bulletin neige & avalanches par téléphone au 0 892 68 10 20 Service 0,35 € / min + prix appel

RÉPUBLIQUE FRANÇAISE
Liberté Égalité Fraternité

METEO FRANCE
À VOS CÔTÉS, DANS UN CLIMAT QUI CHANGE

Bulletin d'estimation du risque d'avalanche

(valable en dehors des pistes balisées et ouvertes)

MASSIF : Chartreuse

Rédigé le mercredi 8 avril 2026 à 17h

Conditions nivo-météo des 7 derniers jours

	jeu. 02/04				ven. 03/04				sam. 04/04				dim. 05/04				lun. 06/04				mar. 07/04				mer. 08/04			
	03h	09h	15h	21h	03h	09h	15h	21h	03h	09h	15h	21h	03h	09h	15h	21h	03h	09h	15h	21h	03h	09h	15h	21h	03h	09h	15h	21h
Météo																												
Vent (km/h)	25	35	45	40	40	30	20	20	35	30	15	15	15	15	25	25	20	15	15	5	10	10	5	10	10	10	0	5
à 2000m	↓	↓	↓	↙	↓	↙	↙	↓	↙	↙	↙	↗	↗	↗	↗	→	↗	→	↗	↑	↘	↑	↑	↙	↙	↙	↑	↙
Vent (km/h)	15	15	30	30	30	15	15	10	15	15	10	10	15	15	20	20	10	10	10	0	0	10	5	5	5	5	5	5
à 1500m	↓	↙	↓	↓	↓	↓	↓	↓	↙	↓	→	↖	↖	↑	↗	↗	↑	↖	→	↑	↑	↗	←	↙	↙	↙	↘	↻

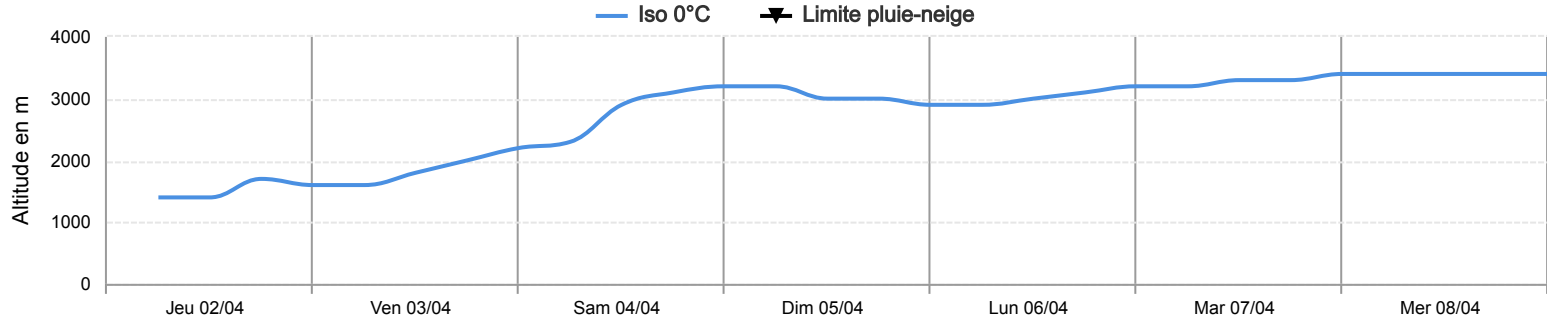

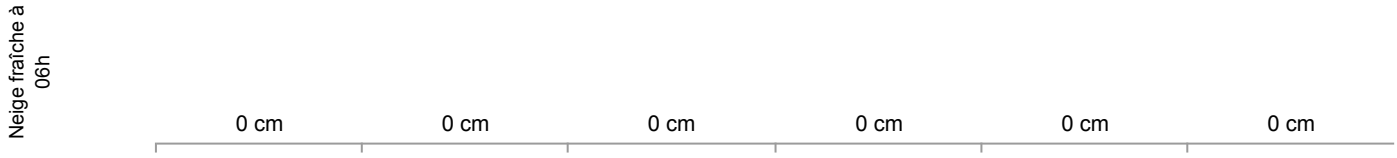

Risque d'avalanche	jeu. 02/04	ven. 03/04	sam. 04/04	dim. 05/04	lun. 06/04	mar. 07/04	mer. 08/04
	2	2	2	2	2	2	2

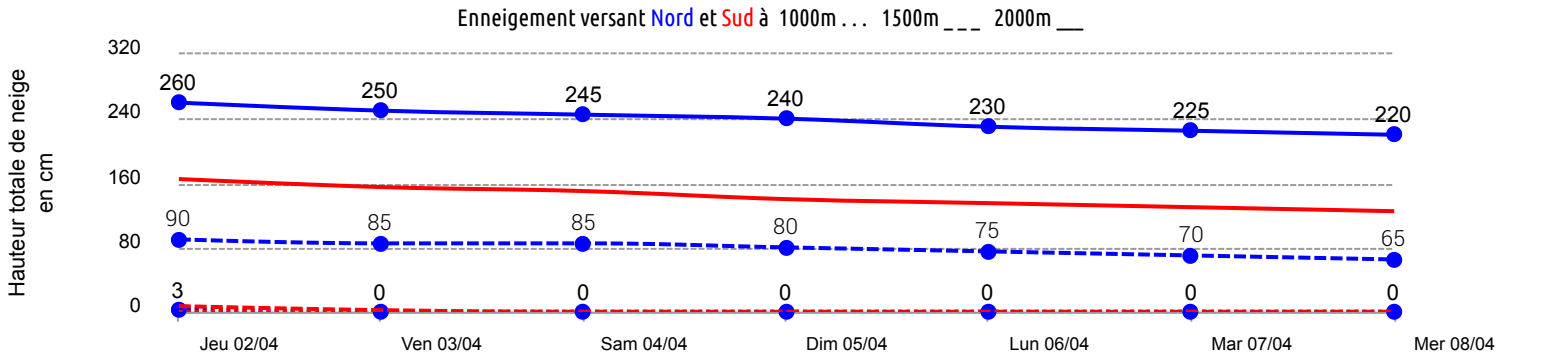

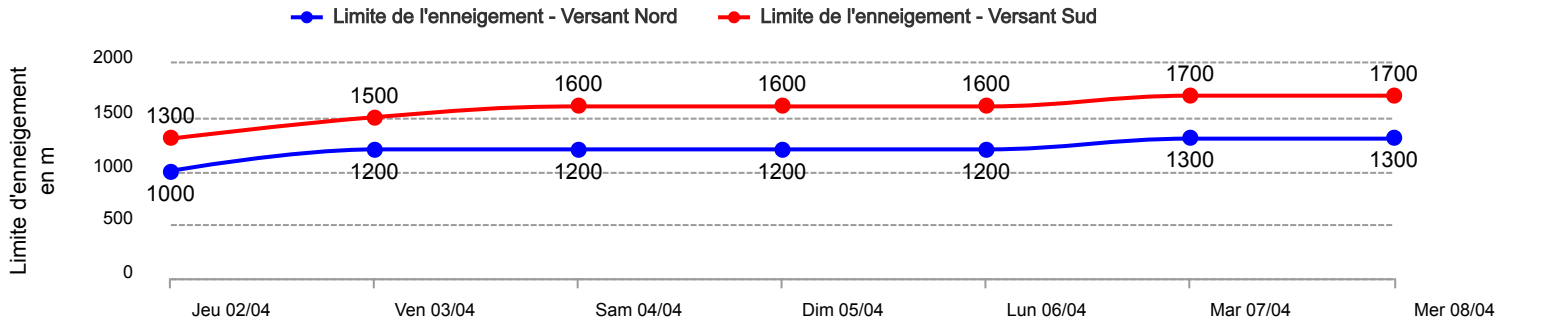

Pour consulter la vigilance en cours, veuillez vous rendre sur le site https://vigilance.meteofrance.fr/fr

Météo-France - 73 avenue de Paris, 94165 Saint-Mandé cedex - Contact : contact@meteo.fr

Rédigé par Météo-France avec la contribution des observateurs du réseau nivo-météorologiques. Partenariat : ANMSM (Maires de Stations de Montagne), DSF (Domaines Skiables de France), ADSP (Directeurs de Pistes et de la Sécurité des Stations de Sports d'Hiver) et autres acteurs de la montagne.

Bulletin neige & avalanches par téléphone au
0 892 68 10 20 Service 0,35 € / min + prix appel