GOBIERNO DE ESPAÑA
VICEPRESIDENCIA TERCERA DEL GOBIERNO
MINISTERIO PARA LA TRANSICIÓN ECOLÓGICA Y EL RETO DEMOGRÁFICO

Boletín de información nivológica y de peligro de aludes

Pirineo Navarro y Aragonés

aemet Agencia Estatal de Meteorología

jueves, 9 de abril de 2026

Pronóstico hasta las 24 horas del viernes, día 10 de abril

(Válido fuera de pistas de esquí balizadas y abiertas)

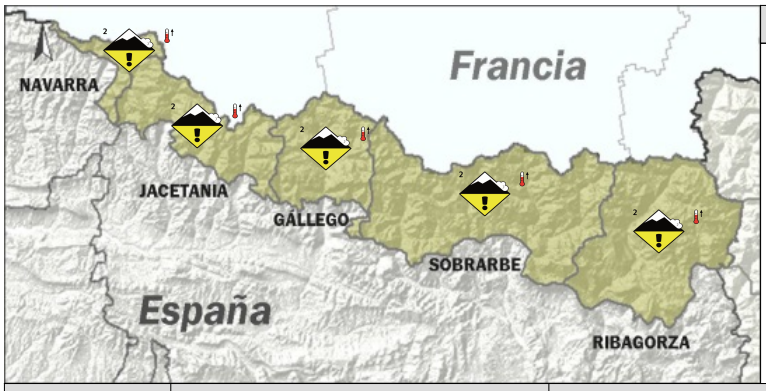

Problemas de aludes

Nieve húmeda

Capas débiles persistentes

Macizo	Peligro	Problemas de aludes, cota, orientación, tamaño	Innivación observada (m)
Navarra	2 Limitado; 1→2	Nieve húmeda: N O E S; 2	2026-04-09: N S; Cota más baja caras N
Jacetania	2 Limitado; 2	Nieve húmeda: N O E S; 2 Capas débiles persistentes: 2400; N O E S; 2	2026-04-09: N S; Cota más baja caras N
Gállego	2 Limitado; 2	Nieve húmeda: N O E S; 2 Capas débiles persistentes: 2400; N O E S; 2	2026-04-09: N S; Cota más baja caras N
Sobrarbe	2 Limitado; 2	Nieve húmeda: N O E S; 2 Capas débiles persistentes: 2400; N O E S; 2	2026-04-09: N S; Cota más baja caras N

AEMET. Se autoriza la reproducción de su contenido citando la fuente.

Boletín de información nivológica y de peligro de aludes

Pirineo Navarro y Aragonés

Ribagorza	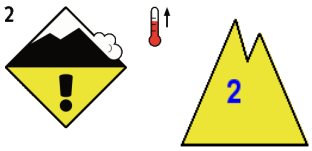 **Limitado**	**Nieve húmeda** 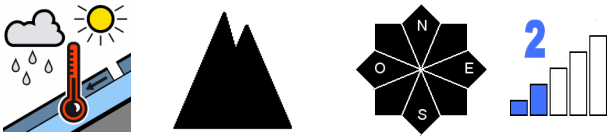 **Capas débiles persistentes** 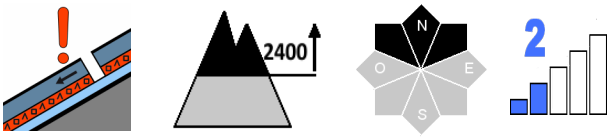	2026-04-09 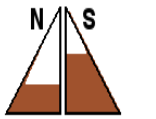 Cota más baja caras N

Estado del manto y observaciones recientes

El manto continúa menguando día a día, debido a la abundante insolación y a las temperaturas elevadas de las últimas jornadas. Así, los procesos de humidificación y compactación de este siguen intensificándose, y en la red de observación se han registrado pérdidas de 5-7 cm en las últimas 24 horas. El manto es continuo a partir de unos 1700-1900 metros y se observa gran asimetría norte-sur, con pérdidas notables en las solanas. A pesar de ello, los espesores siguen estando por encima de lo que sería habitual a estas alturas de la temporada. A unos 2100-2200 metros se alcanzan los 80-170 cm en la red de observación, valores que se pueden superar en ventisqueros y otras zonas propensas a la acumulación.

El manto está húmedo y presenta perfil primaveral, sobre todo en las solanas. El rehielo nocturno está restringido a cotas altas y es poco efectivo, pues las costras tienden a fundirse rápidamente con el calentamiento diurno. Las placas de viento han ido estabilizándose, pero todavía podrían quedar activas en las altas umbrías, donde también persisten algunas capas débiles a distintas profundidades que podrían mostrar cierta reactividad.
No se han reportado aludes desde los puestos de observación en las últimas 24h.

Evolución del manto y peligro de aludes para el viernes, día 10

Problema de nieve húmeda y deslizamientos basales. Problema de placas de viento y capas débiles persistentes en umbrías de cotas altas.

Mañana la insolación seguirá siendo abundante y las temperaturas continuarán siendo elevadas para la época. Por tanto, serán probables los aludes espontáneos de nieve húmeda, por lo general de tamaño pequeño (riesgo de caída) o mediano (capaz de enterrar a una persona), sobre todo en solanas y a partir del mediodía. Además, en zonas de manto grueso homogéneo o con pocas capas sobre laderas herbosas o de roca lisa, son posibles los deslizamientos basales que, en caso de producirse, podrían alcanzar dimensiones mayores.

Las placas de viento generadas durante el pasado episodio han ido estabilizándose, aunque todavía podrán mantenerse frágiles en umbrías por encima de unos 2300-2400 metros. Generalmente, se necesitará una sobrecarga fuerte (paso de varios esquiadores sin respetar la distancia de seguridad) para colapsarlas, provocando aludes de tamaño mediano, que podrían llegar a ser grandes (capaz de enterrar un vehículo) en las zonas de mayor acumulación o si se ve afectada alguna capa débil persistente situada a cierta profundidad.

AEMET. Se autoriza la reproducción de su contenido citando la fuente.

Predicción meteorológica para el viernes, día 10

Pirineo navarro:
Poco nuboso o despejado. Probable polvo en suspensión.
Temperaturas mínimas en ligero o moderado descenso. Máximas en ligero o moderado ascenso.
Viento con predominio de la componente sur, flojo aumentando a moderado con intervalos de fuerte al final del día.

Pirineo aragonés:
Poco nuboso o despejado. Por la tarde podrán crecer algunas nubes de evolución diurna. Probable polvo en suspensión. No se esperan precipitaciones.
Temperaturas con pocos cambios. Algunas heladas débiles en las cumbres de mayor altitud.
Viento con predominio de la componente sur, flojo aumentando a moderado al final del día. Del oeste y sudoeste en cotas altas, moderado con intervalos de fuerte por la tarde.

Datos en la atmósfera libre:

Altitud de la isoterma de 0 ºC: 3400 m
Altitud de la isoterma de -10 ºC: 2700 m

Viento a 1500 m: S 10 km/h
Viento a 3000 m: SW 30 km/h

Evolución para el sábado día 11

El sábado, nivel de peligro en ascenso en la segunda mitad del día.

(Información elaborada a partir de los datos recibidos de los refugios de Linza, Lizara, Panticosa, Bachimaña, Góriz, Pineta, Estós, Angel Orús, La Renclusa, Cap de Llauset y Belagua, de las estaciones de esquí de Astún y Panticosa (lagos) y de Ordesa Pradera)

Escala europea de peligro de aludes

Débil | Limitado | Notable | Fuerte | Muy Fuerte

Problemas de aludes

Nieve reciente | Placas de viento | Capas débiles persistentes | Nieve húmeda | Deslizamientos basales | Sin problema evidente

Nota1: Se recuerda que, siempre que haya nieve, la ausencia total de peligro no existe. Hay que tener presente que en circunstancias desfavorables, con aludes de tamaño 1 (alud pequeño o colada) y tamaño 2 (alud mediano), se pueden sufrir severos daños personales.

Nota2: Los BPA se elaboran en base a información meteorológica así como al estado del manto nivoso a través de sondeos puntuales. Se advierte a los usuarios de la variabilidad de esta información al extrapolarla a zonas extensas de montaña. Por ello, AEMET no se hace responsable de su uso para la toma de decisiones que conciernen a la seguridad personal, ni de los riesgos físicos o materiales de ellas derivadas.

AEMET. Se autoriza la reproducción de su contenido citando la fuente.