aineva.it

Freitag 10.04.2026

Veröffentlicht am 09.04.2026 um 17:00

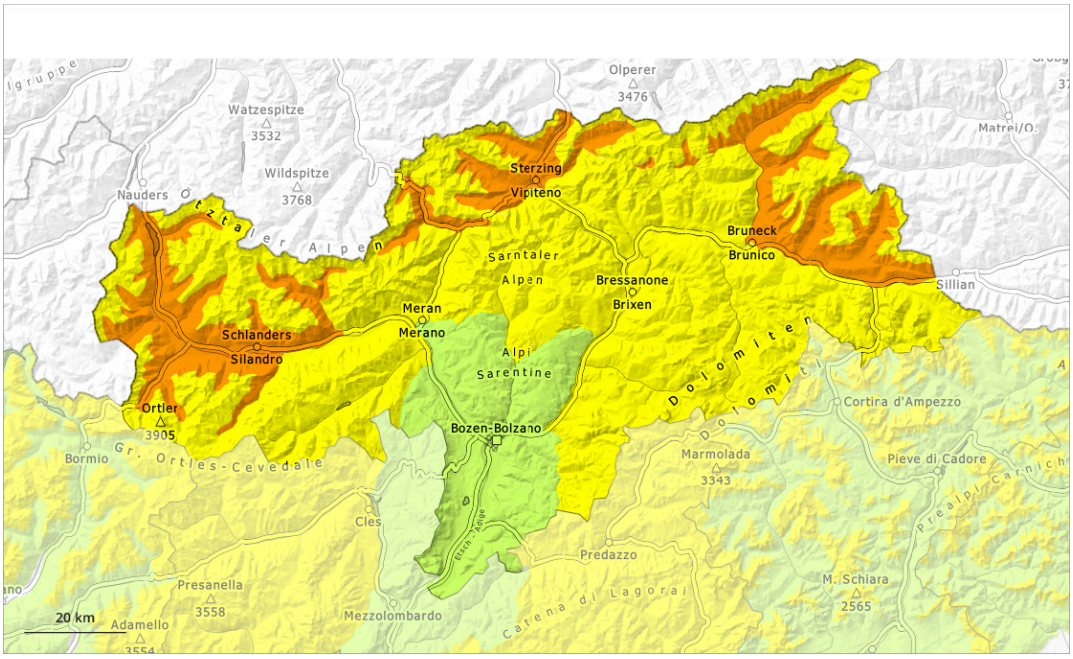

1	2	3	4	5
gering	mäßig	erheblich	groß	sehr groß

Gefahrenstufe 3 - Erheblich

2400m

Tendenz: Lawinengefahr bleibt gleich
am Samstag, den 11.04.2026

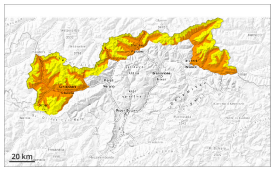

Nassschnee

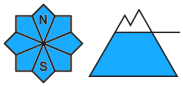

2400m

Altschnee

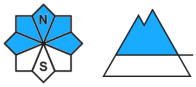

2400m

Die Gefahr von feuchten und nassen Lawinen ist schon am Morgen erhöht. Schwachschichten im Altschnee können stellenweise von einzelnen Wintersportlern ausgelöst werden.

Die Gefahr von feuchten und nassen Lawinen ist schon am Morgen erhöht. Lawinen können in tiefe Schichten durchreißen und vereinzelt groß werden. Dies an allen Expositionen v.a. unterhalb von rund 2400 m.

Zudem können stellenweise Lawinen leicht im schwachen Altschnee ausgelöst werden. Solche Gefahrenstellen liegen vor allem an sehr steilen West- und Osthängen zwischen etwa 2400 und 2800 m sowie an sehr steilen Schattenhängen oberhalb von rund 2400 m. Die Gefahrenstellen sind schwer zu erkennen. Wummgeräusche und Risse beim Betreten der Schneedecke können auf die Gefahr hinweisen.

Auf der harten Schneeoberfläche besteht im Steilgelände Absturzgefahr. Dies an extrem steilen Sonnenhängen in der Höhe.

Schneedecke

Gefahrenmuster gm.3: regen auf schnee | gm.1: bodennahe schwachschicht

Die nächtliche Abstrahlung ist reduziert. Die Schneeoberfläche gefriert kaum. Es fällt etwas Regen. Die Schneedecke wird zunehmend durchnässt. Dies an allen Expositionen unterhalb von rund 2400 m.

Im oberen Teil der Altschneedecke sind vereinzelt störanfällige Schwachschichten vorhanden. Der untere Teil der Schneedecke ist aufbauend umgewandelt. Dies vor allem an West-, Nord- und Osthängen in hohen Lagen sowie an steilen Sonnenhängen im Hochgebirge.

Tendenz

Anstieg der Gefahr von feuchten und nassen Lawinen mit der tageszeitlichen Erwärmung und der Sonneneinstrahlung.

Gefahrenstufe 2 - Mäßig

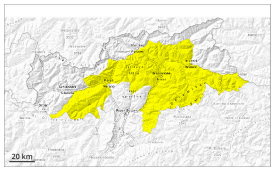

Tendenz: Lawinengefahr bleibt gleich
am Samstag, den 11.04.2026

Nassschnee

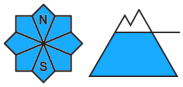

Altschnee

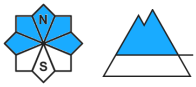

Die Gefahr von feuchten und nassen Lawinen besteht schon am Morgen. Schwachschichten im Altschnee können stellenweise von einzelnen Wintersportlern ausgelöst werden.

Die Gefahr von feuchten und nassen Lawinen besteht schon am Morgen. Lawinen können in tiefe Schichten durchreißen und mittlere Größe erreichen. Dies an allen Expositionen v.a. unterhalb von rund 2400 m, auch an sehr steilen Sonnenhängen in hohen Lagen.

Gefahrenstellen für trockene Lawinen liegen vor allem an sehr steilen Schattenhängen oberhalb von rund 2400 m. Die Gefahrenstellen sind schwer zu erkennen. Ungünstig sind besonders Übergänge von wenig zu viel Schnee.

Auf der harten Schneeoberfläche besteht im Steilgelände Absturzgefahr.

Schneedecke

Gefahrenmuster gm.10: frühjahrssituation | gm.1: bodennahe schwachschicht

Die nächtliche Abstrahlung ist reduziert. Die Schneeoberfläche gefriert kaum und weicht schon am Vormittag auf. Die Schneedecke wird zunehmend durchnässt. Dies an allen Expositionen unterhalb von rund 2400 m sowie an steilen Sonnenhängen in hohen Lagen.

Die alten Triebschneeansammlungen überlagern vor allem an West-, Nord- und Osthängen in hohen Lagen eine schwache Altschneedecke. Die Schneedecke ist kleinräumig sehr unterschiedlich.

An steilen Sonnenhängen in tiefen und mittleren Lagen liegt kaum Schnee.

Tendenz

Anstieg der Gefahr von feuchten und nassen Lawinen mit der tageszeitlichen Erwärmung und der Sonneneinstrahlung.

Gefahrenstufe 1 - Gering

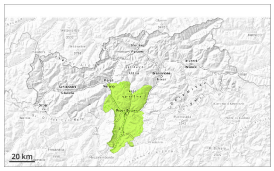

1

Tendenz: Lawinengefahr nimmt ab
am Samstag, den 11.04.2026

Geringe Lawinengefahr.

Im Tagesverlauf steigt die Auslösebereitschaft von nassen Lawinen besonders an extrem steilen Ost- und Westhängen an. Lawinen können sehr vereinzelt in tiefe Schichten durchreißen und vereinzelt mittlere Größe erreichen.
Auf der harten Schneeoberfläche besteht im Steilgelände Absturzgefahr.

Schneedecke

Gefahrenmuster gm.10: frühjahrssituation

Die Schneedecke ist kleinräumig sehr unterschiedlich. Vor allem an steilen Sonnenhängen in tiefen und mittleren Lagen liegt kaum Schnee. Sonne und Wärme führen zu einer zunehmenden Durchnässung der Schneedecke.

Tendenz

Geringe Lawinengefahr.