ICGC Institut Cartogràfic i Geològic de Catalunya

Servei Meteorològic de Catalunya meteo.cat

Boletín de peligro de aludes para el Pirineo de Catalunya
Del 09/04/2026 al 10/04/2026

(Válido fuera pistas de esquí y zonas no controladas)

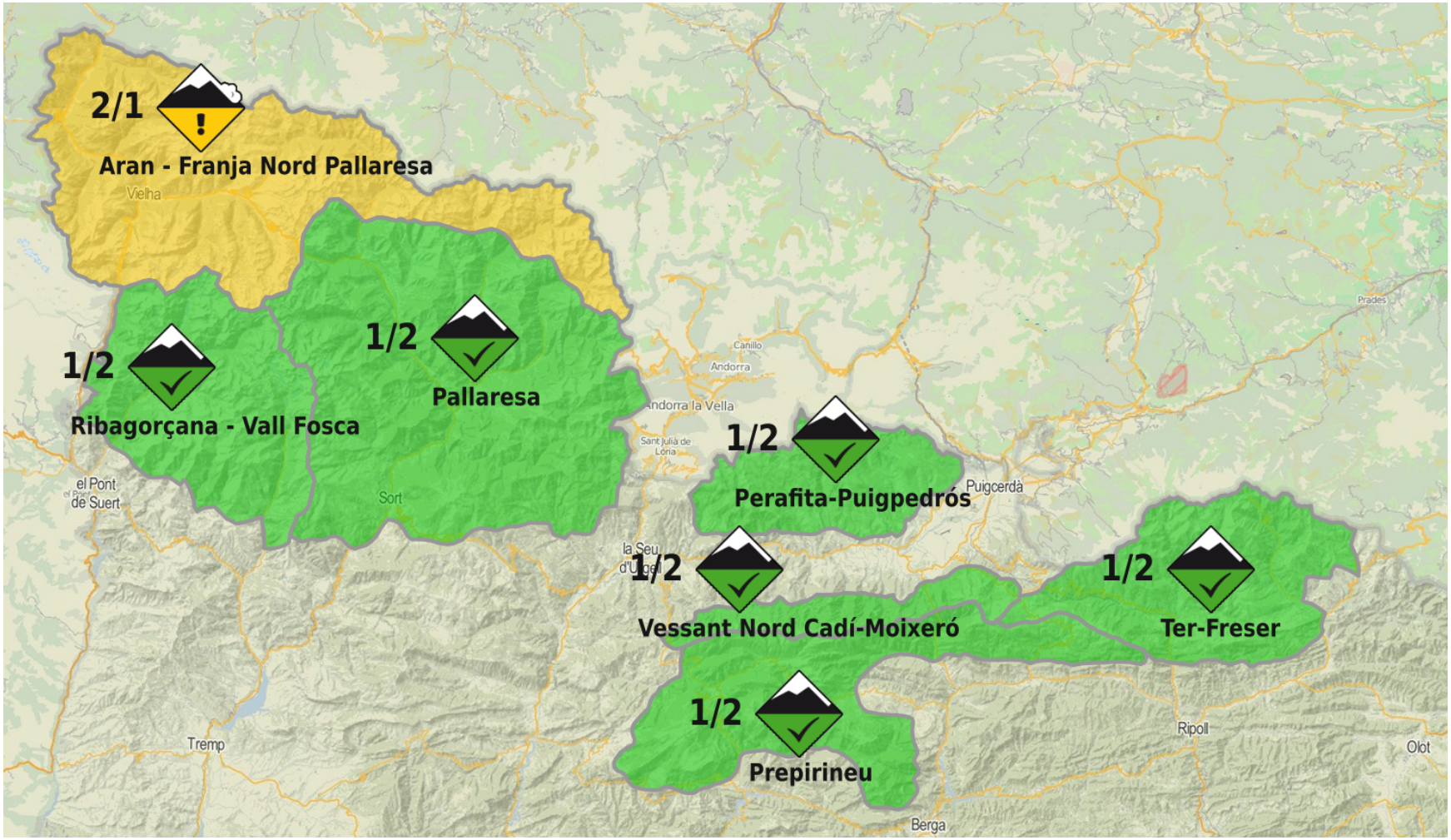

5 MUY FUERTE	4 FUERTE	3 NOTABLE	2 LIMITADO	1 DÉBIL

ICGC Institut Cartogràfic i Geològic de Catalunya

Servei Meteorològic de Catalunya meteo.cat

Boletín de peligro de aludes Aran - Franja Nord Pallaresa Del 09/04/2026 al 10/04/2026

(Válido fuera pistas de esquí y zonas no controladas)

LIMITADO (2) desde media mañana. DÉBIL (1).

Situación primaria

Nieve húmeda

Distribución

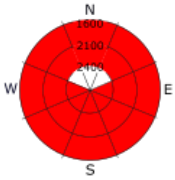

Tamaño

Origen

Tendencia

Situación secundaria

Capas débiles persistentes

Distribución

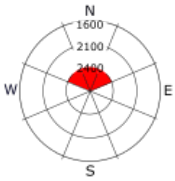

Tamaño

Origen

Tendencia

Estado del manto nivoso

Tras el rehielo nocturno, desde media mañana aumentará el humedecimiento respecto a días pasados, ya que por la tarde puede haber nubes bajas enganchadas a las cimas y algún chubasco de agua hasta las cimas. A partir de media mañana habrá aludes de nieve húmeda de tamaño 1 y 2 (suficiente para enterrar a una persona). En terreno soleado se darán en todas las cotas; arrancarán cerca de puntos oscuros como rocas y árboles. También se espera la caída natural de deslizamientos basales de tamaño 2 en terreno propicio. Ha disminuido la caída de aludes naturales de placa de tamaños 2 y 3 (suficiente para enterrar a un grupo de personas) por encima de las capas débiles persistentes. Sin embargo, los aludes accidentales son aún posibles por encima de 2.400 m en terreno umbrío por sobrecarga fuerte, allí donde encontramos la nieve ligeramente placada, en sectores protegidos del viento, aunque superficialmente esté un poco húmeda. Se recomienda haber finalizado las actividades antes del mediodía.

Distribución del manto nivoso

Los espesores a unos 2.200 m rondan los 150-220 cm. Tras la disminución de los grosores por el fuerte asentamiento de días pasados, actualmente los grosores menguan a razón de unos 5 cm por día. Sin embargo, los valores están muy por encima de los normales para la época.

Tendencia para las próximas 48-72h

Irá aumentando la probabilidad de aludes de nieve húmeda por efecto del calor hasta el sábado-domingo, en el que podría, primero, llover y, después, nevar de nuevo. Peligro EN LIGERO AUMENTO.

El próximo boletín será emitido el día 2026-04-10

5 MUY FUERTE	4 FUERTE	3 NOTABLE	2 LIMITADO	1 DÉBIL

EAWS EUROPEAN AVALANCHE WARNING SERVICES

ICGC Institut Cartogràfic i Geològic de Catalunya

Servei Meteorològic de Catalunya

Boletín de peligro de aludes Ribagorçana - Vall Fosca Del 09/04/2026 al 10/04/2026

(Válido fuera pistas de esquí y zonas no controladas)

DÉBIL (1). LIMITADO (2) en mitad norte desde media mañana.

Situación primaria

Nieve húmeda

Distribución

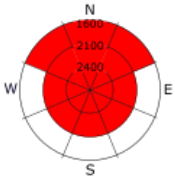

Tamaño

Origen

Tendencia

Situación secundaria

Capas débiles persistentes

Distribución

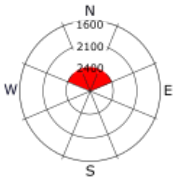

Tamaño

Origen

Tendencia

Estado del manto nivoso

El manto continuará estando muy húmedo desde media mañana y se enfría y rehiela con facilidad a lo largo de la noche. A partir de media mañana podrán caer aludes de nieve húmeda en terreno muy pendiente soleado; serán de tamaño 1 (pequeña, pero suficiente para arrastrarnos), especialmente en torno a puntos rocosos. El humedecimiento y la actividad de algún alud de nieve húmeda se puede alargar hasta el anochecer debido a nubes bajas de evolución diurna enganchadas a las cimas. Hay que evitar el terreno donde la penetración de la bota o el esquí sean profundas, así como laderas en las que observamos caídas de purgas. En la mitad norte del sector, en terreno muy umbrío y elevado, difícilmente se podría desencadenar todavía algún alud de placa al paso de un grupo de personas de hasta tamaño 2 (suficiente para enterrar a una persona) a partir de media mañana.

Distribución del manto nivoso

La nieve es continua a partir de 1.700 m en terreno umbrío y de 2.000 m en solanas. Los grosores alcanzan los 100-120 cm a unos 2.200 m, con frecuentes deflaciones y acumulaciones por encima del nivel del bosque. Estos valores están algo por debajo de los normales para la época. Debido a la fusión, van disminuyendo a razón de unos 5 cm por día.

Tendencia para las próximas 48-72h

Irá aumentando la probabilidad de aludes de nieve húmeda por efecto del calor hasta el sábado-domingo, en el que podría, primero, llover y, después, nevar de nuevo. Peligro EN LIGERO AUMENTO.

El próximo boletín será emitido el día 2026-04-10

5 MUY FUERTE	4 FUERTE	3 NOTABLE	2 LIMITADO	1 DÉBIL

EAWS EUROPEAN AVALANCHE WARNING SERVICES

ICGC Institut Cartogràfic i Geològic de Catalunya

Servei Meteorològic de Catalunya meteo.cat

Boletín de peligro de aludes Pallaresa
Del 09/04/2026 al 10/04/2026

(Válido fuera pistas de esquí y zonas no controladas)

DÉBIL (1). LIMITADO (2) en mitad norte desde media mañana.

Situación primaria

Nieve húmeda

Distribución

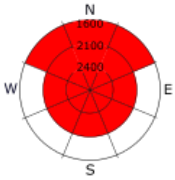

Tamaño

Origen

Tendencia

Estado del manto nivoso

El manto continuará estando muy húmedo desde media mañana y se enfría y rehiela con facilidad a lo largo de la noche. A partir de media mañana podrán caer aludes de nieve húmeda en terreno muy pendiente soleado; serán de tamaño 1 (pequeña, pero suficiente para arrastrarnos), especialmente en torno a puntos rocosos. El humedecimiento y la actividad de algún alud de nieve húmeda se puede alargar hasta el anochecer debido a nubes bajas de evolución diurna enganchadas a las cimas. Hay que evitar el terreno donde la penetración de la bota o el esquí sean profundas, así como laderas en las que observamos caídas de purgas. En la mitad norte del sector, en terreno muy umbrío y elevado, difícilmente se podría desencadenar todavía algún alud de placa al paso de un grupo de personas de hasta tamaño 2 (suficiente para enterrar a una persona) a partir de media mañana.

Distribución del manto nivoso

La nieve es continua a partir de 1.700-1.900 m en las umbrías y está presente por encima de 2.000 en las solanas, con mayor continuidad por encima de 2.400 m. Los grosores alcanzan los 100-120 cm a unos 2.200 m, con frecuentes deflaciones y acumulaciones por encima del nivel del bosque. Debido a la fusión, los grosores disminuyen a razón de 4 cm por día.

Tendencia para las próximas 48-72h

Irá aumentando la probabilidad de aludes de nieve húmeda por efecto del calor hasta el sábado-domingo, en el que podría, primero, llover y, después, nevar de nuevo. Peligro EN LIGERO AUMENTO.

El próximo boletín será emitido el día 2026-04-10

5 MUY FUERTE	4 FUERTE	3 NOTABLE	2 LIMITADO	1 DÉBIL

EAWS EUROPEAN AVALANCHE WARNING SERVICES

ICGC Institut Cartogràfic i Geològic de Catalunya

Servei Meteorològic de Catalunya meteo.cat

Boletín de peligro de aludes Perafita-Puigpedrós Del 09/04/2026 al 10/04/2026

(Válido fuera pistas de esquí y zonas no controladas)

DÉBIL (1). LIMITADO (2) a partir de media mañana.

Situación primaria

Nieve húmeda

Distribución

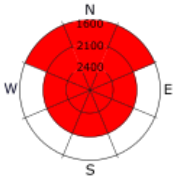

Tamaño

Origen

Tendencia

Situación secundaria

Capas débiles persistentes

Distribución

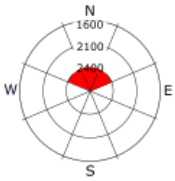

Tamaño

Origen

Tendencia

Estado del manto nivoso

El manto continuará estando muy húmedo desde media mañana y se enfría y rehiela con facilidad a lo largo de la noche. A partir de media mañana podrán caer aludes de nieve húmeda en terreno muy pendiente soleado; serán de tamaño 1 (pequeña, pero suficiente para arrastrarnos), especialmente en torno a puntos rocosos. El humedecimiento y la actividad de algún alud de nieve húmeda se puede alargar hasta el anochecer debido a nubes bajas de evolución diurna enganchadas a las cimas. Hay que evitar el terreno donde la penetración de la bota o el esquí sean profundas, así como laderas en las que observamos caídas de purgas. En terreno muy umbrío y elevado, difícilmente se podría desencadenar todavía algún alud de placa al paso de un grupo de personas de hasta tamaño 2 (suficiente para enterrar a una persona) a partir de media mañana.

Distribución del manto nivoso

Hay nieve en el suelo por encima de 1.900 m en terreno umbrío, y de 2.200 m en solanas. Es esquiable a partir de unos 2.000 m en N. Los espesores, aunque irregulares, rondan los 60-100 cm en umbrías, a 2.300 m; existen deflaciones y acumulaciones por encima del nivel del bosque. Son grosores por encima de los habituales Debido a la fusión, disminuye a unos 6 cm por día en vertientes soleadas.

Tendencia para las próximas 48-72h

Irá aumentando la probabilidad de aludes de nieve húmeda por efecto del calor hasta el sábado-domingo, en el que podría, primero, llover y, después, nevar de nuevo. Peligro EN LIGERO AUMENTO.

El próximo boletín será emitido el día 2026-04-10

5 MUY FUERTE	4 FUERTE	3 NOTABLE	2 LIMITADO	1 DÉBIL

EAWS EUROPEAN AVALANCHE WARNING SERVICES

ICGC Institut Cartogràfic i Geològic de Catalunya

Servei Meteorològic de Catalunya meteo.cat

Boletín de peligro de aludes Vessant Nord Cadí-Moixeró Del 09/04/2026 al 10/04/2026

(Válido fuera pistas de esquí y zonas no controladas)

DÉBIL (1). LIMITADO (2) a partir de media mañana.

Situación primaria

Nieve húmeda

Distribución

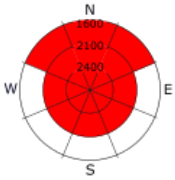

Tamaño

Origen

Tendencia

Situación secundaria

Capas débiles persistentes

Distribución

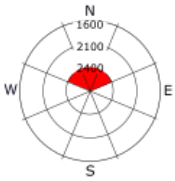

Tamaño

Origen

Tendencia

Estado del manto nivoso

El manto continuará estando muy húmedo desde media mañana y se enfría y rehiela con facilidad a lo largo de la noche. A partir de media mañana podrán caer aludes de nieve húmeda en terreno muy pendiente soleado; serán de tamaño 1 (pequeña, pero suficiente para arrastrarnos), especialmente en torno a puntos rocosos. El humedecimiento y la actividad de algún alud de nieve húmeda se puede alargar hasta el anochecer debido a nubes bajas de evolución diurna enganchadas a las cimas. Hay que evitar el terreno donde la penetración de la bota o el esquí sean profundas, así como laderas en las que observamos caídas de purgas. En terreno muy umbrío y elevado, como las partes altas y en sombra de las canales, difícilmente se podría desencadenar todavía algún alud de placa al paso de un grupo de personas de hasta tamaño 2 (suficiente para enterrar a una persona) a partir de media mañana.

Distribución del manto nivoso

En umbrías hay nieve por encima de unos 1.600 m; en solanas por encima de unos 2.000 m. Los grosores están alrededor de 150-170 cm a 2.200 m, con algunas acumulaciones y deflaciones por encima del nivel del bosque. Estos valores son muy excedentarios para la época del año. Debido a la fusión, van disminuyendo a razón de unos 4 cm por día.

Tendencia para las próximas 48-72h

Irá aumentando la probabilidad de aludes de nieve húmeda por efecto del calor hasta el sábado-domingo, en el que podría, primero, llover y, después, nevar de nuevo. Peligro EN LIGERO AUMENTO.

El próximo boletín será emitido el día 2026-04-10

5 MUY FUERTE	4 FUERTE	3 NOTABLE	2 LIMITADO	1 DÉBIL

EAWS EUROPEAN AVALANCHE WARNING SERVICES

ICGC Institut Cartogràfic i Geològic de Catalunya

Servei Meteorològic de Catalunya

Boletín de peligro de aludes Prepirineu
Del 09/04/2026 al 10/04/2026

(Válido fuera pistas de esquí y zonas no controladas)

DÉBIL (1). LIMITADO (2) a partir de media mañana.

Situación primaria

Nieve húmeda

Distribución

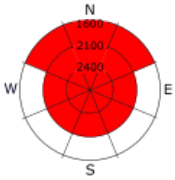

Tamaño

Origen

Tendencia

Estado del manto nivoso

El manto continuará estando muy húmedo desde media mañana y se enfría y rehiela con facilidad a lo largo de la noche. A partir de media mañana podrán caer aludes de nieve húmeda en terreno muy pendiente soleado; serán de tamaño 1 (pequeña, pero suficiente para arrastrarnos), especialmente en torno a puntos rocosos. El humedecimiento y la actividad de algún alud de nieve húmeda se puede alargar hasta el anochecer debido a nubes bajas de evolución diurna enganchadas a las cimas. Hay que evitar el terreno donde la penetración de la bota o el esquí sean profundas, así como laderas en las que observamos caídas de purgas.

Distribución del manto nivoso

El manto es continuo por encima de unos 1.800 m a terreno umbrío y de unos 2.000 m a solanas. Los espesores, aunque irregulares, rondan los 80-100 cm a 2.300 m. Debido a la fusión, van disminuyendo a razón de unos 4 cm por día.

Tendencia para las próximas 48-72h

Irá aumentando la probabilidad de aludes de nieve húmeda por efecto del calor hasta el sábado-domingo, en el que podría, primero, llover y, después, nevar algo de nuevo. Peligro EN LIGERO AUMENTO.

El próximo boletín será emitido el día 2026-04-10

5 MUY FUERTE	4 FUERTE	3 NOTABLE	2 LIMITADO	1 DÉBIL

EAWS EUROPEAN AVALANCHE WARNING SERVICES

ICGC Institut Cartogràfic i Geològic de Catalunya

Servei Meteorològic de Catalunya meteo.cat

Boletín de peligro de aludes Ter-Freser
Del 09/04/2026 al 10/04/2026

(Válido fuera pistas de esquí y zonas no controladas)

DÉBIL (1). LIMITADO (2) a partir de media mañana.

Situación primaria

Nieve húmeda

Distribución

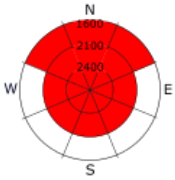

Tamaño

Origen

Tendencia

Estado del manto nivoso

El manto continuará estando muy húmedo desde media mañana y se enfría y rehiela con facilidad a lo largo de la noche. A partir de media mañana podrán caer aludes de nieve húmeda en terreno muy pendiente soleado; serán de tamaño 1 (pequeña, pero suficiente para arrastrarnos), especialmente en torno a puntos rocosos. El humedecimiento y la actividad de algún alud de nieve húmeda se puede alargar hasta el anochecer debido a nubes bajas de evolución diurna enganchadas a las cimas. Hay que evitar el terreno donde la penetración de la bota o el esquí sean profundas, así como laderas en las que observamos caídas de purgas. En terreno muy umbrío y elevado, difícilmente se podría desencadenar todavía algún alud de placa al paso de un grupo de personas de hasta tamaño 2 (suficiente para enterrar a una persona) a partir de media mañana.

Distribución del manto nivoso

El manto es esquiable a umbrías a partir de unos 1.800 m. Los grosores son muy excedentarios para la época del año y en lugares no afectados por el viento oscilan entre 70-100 cm a unos 2.000 m, y más de 150-200 cm por encima de 2.400 m, muy variable por los efectos del viento. Debido a la fusión, van disminuyendo a razón de unos 4 cm por día.

Tendencia para las próximas 48-72h

Irá aumentando la probabilidad de aludes de nieve húmeda por efecto del calor hasta el sábado-domingo, en el que podría, primero, llover y, después, nevar de nuevo. Peligro EN LIGERO AUMENTO.

El próximo boletín será emitido el día 2026-04-10

5 MUY FUERTE	4 FUERTE	3 NOTABLE	2 LIMITADO	1 DÉBIL

EAWS EUROPEAN AVALANCHE WARNING SERVICES