BUTLLETÍ DEL PERILL D'ALLAUS DEL PRINCIPAT D'ANDORRA

Elaborat el 09/04/2026 16:00
Propera actualització 10/04/2026 a les 16h

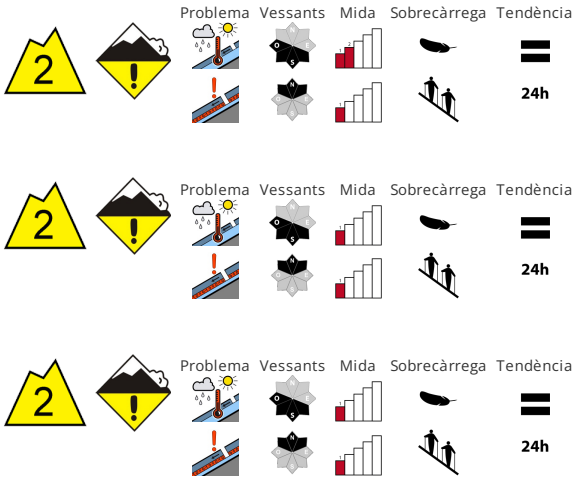

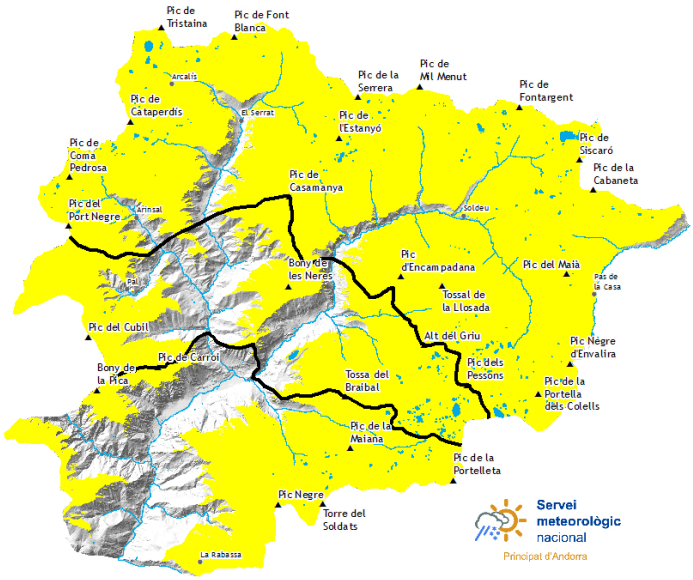

ESTABILITAT DEL MANTELL NIVAL

Després d'una nit serena, al matí predominen en molts sectors condicions d'allaus favorables. Amb l'augment de la temperatura diurna i la radiació solar, la probabilitat de desencadenament d'allaus humides augmentarà progressivament als vessants assolellats. A més, són possibles algunes allaus de lliscament basal. Als vessants obacs molt inclinats a la part superior del mantell de neu hi ha capes febles de cristalls facetats. Les allaus de neu seca poden desencadenar-se a les capes prop de la superfície del mantell de neu principalment per sobrecàrregues fortes. Les allaus en aquests sectors són de manera aïllada de mida mitjana.

QUALITAT DE LA NEU

El temps serà assolellat. La superfície del mantell de neu es regelarà per formar una crosta portant i s'estovarà al llarg del dia. El mantell de neu roman extremadament variable en pocs metres de manera generalitzada. Prop de les carenes els gruixos de neu varien molt per la influència del vent. A causa de la superfície dura del mantell de neu hi ha el perill de relliscar i caure fins i tot en vessants moderadament inclinats. Les excursions de muntanya han de començar i acabar d'hora. Les condicions per les excursions són primaverals.

GRUIXOS DEL MANTELL NIVAL FORA DE PISTA

Zona nord		Gruix neu		
Mantell Nival		1500m	2000m	2500m
N	1600 m	0 cm	150 cm	250 cm
S	1800 m	0 cm	100 cm	180 cm

Zona centre		Gruix neu		
Mantell Nival		1500m	2000m	2500m
N	1600 m	0 cm	120 cm	160 cm
S	1800 m	0 cm	60 cm	120 cm

Zona sud		Gruix neu		
Mantell Nival		1500m	2000m	2500m
N	1600 m	0 cm	120 cm	160 cm
S	1800 m	0 cm	60 cm	120 cm

Govern d'Andorra

Aquest butlletí ha estat elaborat seguint les normes i recomanacions de l'**European Avalanche Warning Services**, del qual el **Servei meteorològic Nacional** n'és membre

Informació detallada per espais naturals protegits

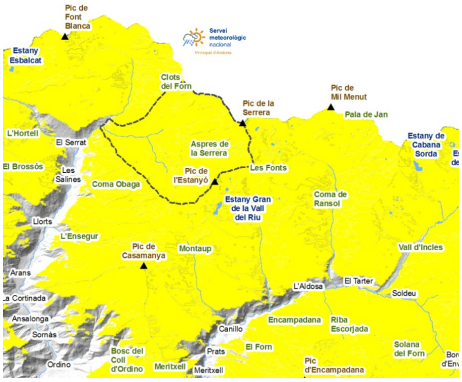

SORTENY

Als vessants sud han tornat a quedar al descobert les estries de la percolació de l´aigua, fet que ens dona indicis de l´estabilitat. Al matí, però, la neu dura ens ha de fer extremar les precaucions per no relliscar. Als vessants nord, identificarem les acumulacions de neu ventada pel seu color. Sempre serà més segur, quant a estabilitat d´allaus, circular per la neu dura.

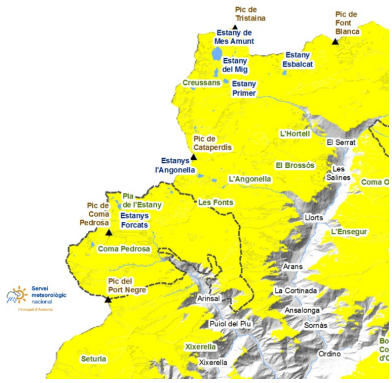

COMAPEDROSA

Encara es poden fer nombroses excursions amb esquí de muntanya, però les parts baixes d´Arinsal no tenen neu. O bé ens haurem d´aproximar esquiant o bé hi haurem d´accedir per Soulcem o l´Angonella. Haurem d´accedir-hi aviat al matí, ja que hem de tenir temps suficient per tornar quan la neu encara no hagi transformat excessivament.

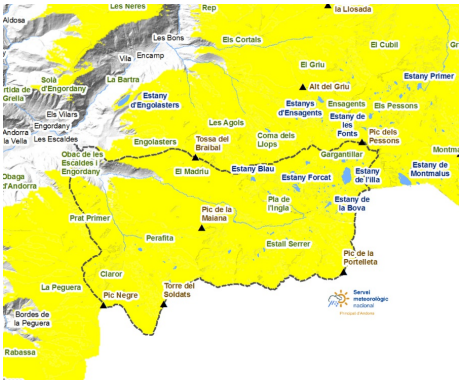

MADRIU-PERAFITA-CLAROR

Les condicions són primaverals, però als vessants nord més inclinats i obacs encara poden trobar alguna placa de neu seca que haurem d´evitar.

BUTLLETÍ DEL PERILL D'ALLAUS DEL PRINCIPAT D'ANDORRA

Servei meteorològic nacional
Principat d'Andorra

Gruixos de neu nova dels darrers dies (de les últimes 24h mesurat a les 06:00h UTC)

	05/04/2026	06/04/2026	07/04/2026	08/04/2026
FEDA (Central)	0 cm	0 cm	0 cm	0 cm
Engolasters - FEDA	0 cm	0 cm	0 cm	0 cm
Bony de les Neres	0 cm	0 cm	0 cm	0 cm
Sorteny	0 cm	0 cm	0 cm	0 cm
Les Fonts d'Arinsal	0 cm	0 cm	0 cm	0 cm
Aixàs	0 cm	0 cm	0 cm	0 cm
Perafita	0 cm	0 cm	0 cm	0 cm
Tossa Espiolets	0 cm	0 cm	0 cm	0 cm
Grau Roig - FEDA	0 cm	0 cm	0 cm	0 cm
Fontverd	0 cm	0 cm	0 cm	0 cm
Coll Ordino	0 cm	0 cm	0 cm	0 cm
Ransol - FEDA	0 cm	0 cm	0 cm	0 cm
Setúria	0 cm	0 cm	0 cm	0 cm
Caborreu	0 cm	0 cm	0 cm	0 cm
La Solana	0 cm	0 cm	0 cm	0 cm
Coll Pa	0 cm	0 cm	0 cm	0 cm
Envalira Antenes	0 cm	0 cm	0 cm	0 cm
Vall del Riu FEDA	0 cm	0 cm	0 cm	0 cm