# BUTLLETÍ DEL PERILL D'ALLAUS DEL PRINCIPAT D'ANDORRA

Servei meteorològic nacional
Principat d'Andorra

Elaborado el 09/04/2026 16:00
Proxima actualización 10/04/2026 a las 16h

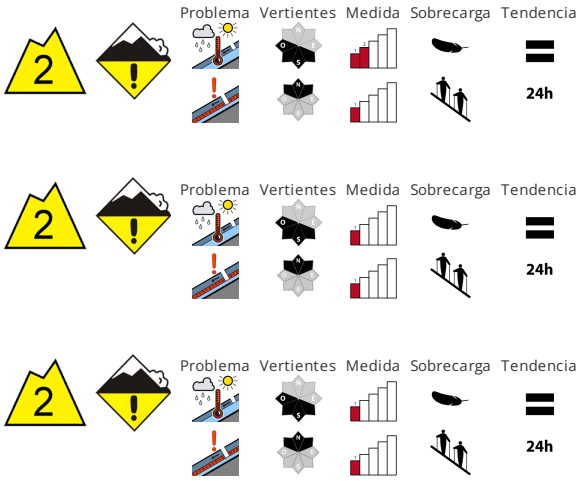


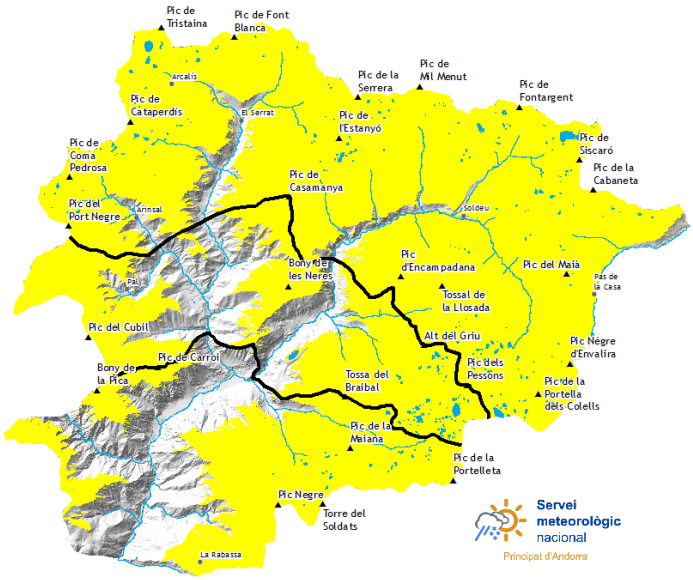


## CALIDAD DE LA NIEVE

Después de una noche serena, por la mañana reinan condiciones favorables. Con el aumento de la temperatura diurna y la radiación solar, la probabilidad de desencadenamiento de aludes de nieve húmeda aumentará progresivamente en las laderas solanas. Además son posibles algunos aludes de deslizamiento basal. En las laderas umbrías muy inclinadas en la parte superior del manto de nieve hay capas débiles de cristales facetados. Los aludes de nieve seca pueden desencadenarse en las capas cercanas a la superficie del manto de nieve principalmente por sobrecargas fuertes. Los aludes en estos sectores son de manera aislada de tamaño mediano.

## ESTABILIDAD DEL MANTO NIVOSO

El tiempo será soleado. La superficie del manto de nieve se volverá a helar para formar una costra portante y se ablandará durante el día. El manto de nieve permanece extremadamente variable en pocos metros en general. Cerca de los cordales los espesores de nieve varían mucho por la influencia del viento. Debido a la superficie dura del manto de nieve hay el peligro de resbalar y caer incluso en laderas moderadamente inclinadas. Las excursiones de montaña deben comenzar y acabar temprano. Las condiciones para las excursiones son primaverales.

## ESPESORES DEL MANTO NIVOSO FUERA DE PISTA

| Zona norte | | Espesor nieve | | | zona centro | | Espesor nieve | | | Zona sur | | Espesor nieve | | |
|---|---|---|---|---|---|---|---|---|---|---|---|---|---|---|
| **Manto Nival** | | 1500m | 2000m | 2500m | **Manto Nival** | | 1500m | 2000m | 2500m | **Manto Nival** | | 1500m | 2000m | 2500m |
| N | 1600 m | 0 cm | 150 cm | 250 cm | N | 1600 m | 0 cm | 120 cm | 160 cm | N | 1600 m | 0 cm | 120 cm | 160 cm |
| S | 1800 m | 0 cm | 100 cm | 180 cm | S | 1800 m | 0 cm | 60 cm | 120 cm | S | 1800 m | 0 cm | 60 cm | 120 cm |

Govern d'Andorra

EAWS EUROPEAN AVALANCHE WARNING SERVICES

Aquest butlletí ha estat elaborat seguint les normes i recomanacions de l'**European Avalanche Warning Services**, del qual el **Servei meteorològic Nacional** n'és membre

# BUTLLETÍ DEL PERILL D'ALLAUS DEL PRINCIPAT D'ANDORRA

Servei meteorològic nacional
Principat d'Andorra

## Información detallada por espacios naturales protegidos

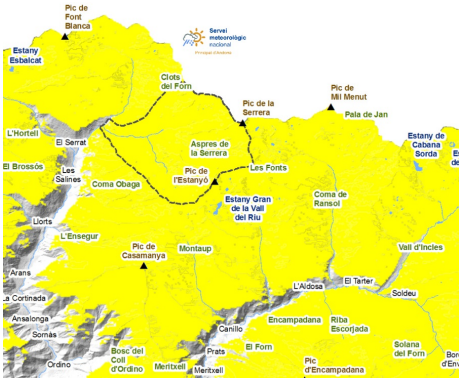


### SORTENY

En las vertientes sur han vuelto a quedar al descubierto las estrías de la percolación del agua, lo que nos da indicios de la estabilidad. Pero por la mañana, la nieve dura debe hacernos extremar las precauciones para no resbalar. En las vertientes norte, identificaremos las acumulaciones de nieve venteada por su color. Siempre será más seguro, en cuanto a estabilidad de aludes, circular por la nieve dura.

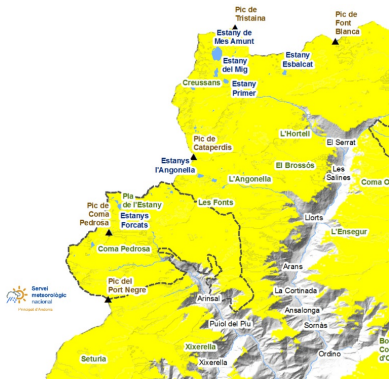


### COMAPEDROSA

Aún se pueden realizar numerosas excursiones en esquí de montaña, pero las partes bajas de Arinsal no tienen nieve. O tendremos que aproximarnos esquiando o tendremos que acceder por Soulcem o Angonella. Deberemos acceder pronto por la mañana, ya que debemos tener tiempo suficiente para volver cuando la nieve todavía no haya transformado excesivamente.

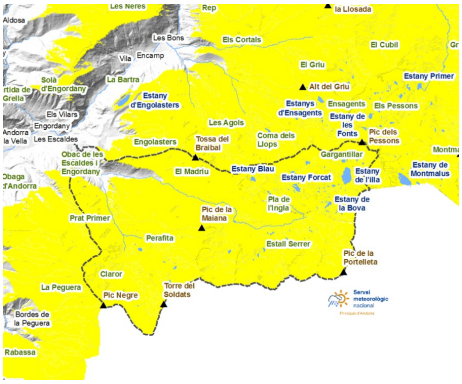


### MADRIU-PERAFITA-CLAROR

Las condiciones son primaverales, pero en las vertientes norte más inclinadas y umbrías todavía pueden encontrar alguna placa de nieve seca que deberemos evitar.

Govern d'Andorra

EAWS
EUROPEAN AVALANCHE WARNING SERVICES

Aquest butlletí ha estat elaborat seguint les normes i recomanacions de l'**European Avalanche Warning Services**, del qual el **Servei meteorològic Nacional** n'és membre

# BUTLLETÍ DEL PERILL D'ALLAUS DEL PRINCIPAT D'ANDORRA

Servei meteorològic nacional
Principat d'Andorra

## Espesores de nieve nueva de los últimos días (de las ultimas 24h mesurado a las 06:00h UTC)

| | 05/04/2026 | 06/04/2026 | 07/04/2026 | 08/04/2026 |
|---|---|---|---|---|
| **FEDA (Central)** | 0 cm | 0 cm | 0 cm | 0 cm |
| **Engolasters - FEDA** | 0 cm | 0 cm | 0 cm | 0 cm |
| **Bony de les Neres** | 0 cm | 0 cm | 0 cm | 0 cm |
| **Sorteny** | 0 cm | 0 cm | 0 cm | 0 cm |
| **Les Fonts d'Arinsal** | 0 cm | 0 cm | 0 cm | 0 cm |
| **Aixàs** | 0 cm | 0 cm | 0 cm | 0 cm |
| **Perafita** | 0 cm | 0 cm | 0 cm | 0 cm |
| **Tossa Espiolets** | 0 cm | 0 cm | 0 cm | 0 cm |
| **Grau Roig - FEDA** | 0 cm | 0 cm | 0 cm | 0 cm |
| **Fontverd** | 0 cm | 0 cm | 0 cm | 0 cm |
| **Coll Ordino** | 0 cm | 0 cm | 0 cm | 0 cm |
| **Ransol - FEDA** | 0 cm | 0 cm | 0 cm | 0 cm |
| **Setúria** | 0 cm | 0 cm | 0 cm | 0 cm |
| **Caborreu** | 0 cm | 0 cm | 0 cm | 0 cm |
| **La Solana** | 0 cm | 0 cm | 0 cm | 0 cm |
| **Coll Pa** | 0 cm | 0 cm | 0 cm | 0 cm |
| **Envalira Antenes** | 0 cm | 0 cm | 0 cm | 0 cm |
| **Vall del Riu FEDA** | 0 cm | 0 cm | 0 cm | 0 cm |