BUTLLETÍ DEL PERILL D'ALLAUS DEL PRINCIPAT D'ANDORRA

Servei meteorològic nacional
Principat d'Andorra

Préparé le 09/04/2026 16:00
Prochaine mise à jour le 10/04/2026 à 16h

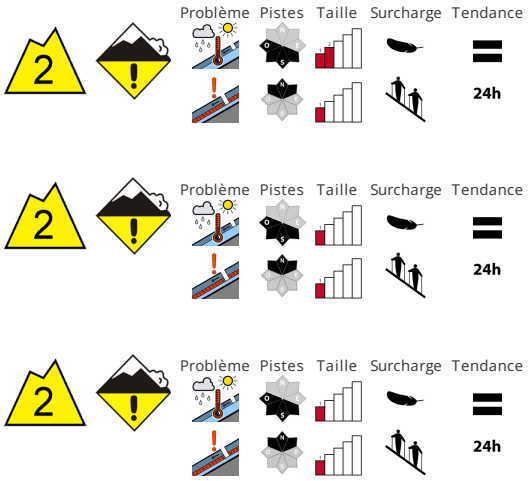

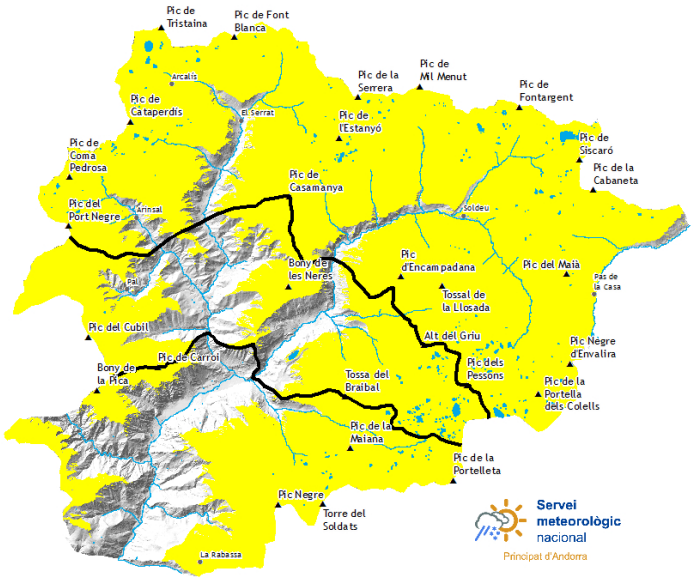

STABILITÉ DU MANTEAU NEIGEUX

Après une nuit claire, il règne le matin des conditions favorables généralisées. Avec le réchauffement diurne et le rayonnement solaire d'avalanches humides augmente progressivement sur les pentes au soleil augmentera. En outre, des avalanches de glissement isolées sont possibles.. Dans la partie supérieure du manteau neigeux des couches fragiles ayant subi une métamorphose constructive à grains anguleux sont présentes ils se rencontrent sur les pentes très raides à l'ombre. Des avalanches sèches peuvent être déclenchées avec en général une surcharge importante dans les couches proches de la surface. Dans ces régions les avalanches sont de manière isolée de taille moyenne.

QUALITÈ DE LA NEIGE

Il fait un temps ensoleillé. La surface de la neige regèle et devient porteuse et se ramollit en cours de journée.. De manière généralisée le manteau neigeux reste très variable à petite échelle.. À proximité des crêtes on trouve suivant l'influence du vent des hauteurs de neiges très différentes. Sur la surface de neige dure il existe également dans des terrains moyennement raides un risque de chute.. Les randonnées devraient être commencées et terminées tôt.. Les conditions de randonnées sont printanières.

EPAISSEUR DE NEIGE HORS PISTE

Zone nord		Epaisseur de neige		
Nival manteau		1500m	2000m	2500m
N	1600 m	0 cm	150 cm	250 cm
S	1800 m	0 cm	100 cm	180 cm

Zone centre		Epaisseur de neige		
Nival manteau		1500m	2000m	2500m
N	1600 m	0 cm	120 cm	160 cm
S	1800 m	0 cm	60 cm	120 cm

Zone sud		Epaisseur de neige		
Nival manteau		1500m	2000m	2500m
N	1600 m	0 cm	120 cm	160 cm
S	1800 m	0 cm	60 cm	120 cm

Govern d'Andorra

EAWS EUROPEAN AVALANCHE WARNING SERVICES

Aquest butlletí ha estat elaborat seguint les normes i recomanacions de l'**European Avalanche Warning Services**, del qual el **Servei meteorològic Nacional** n'és membre

Des informations détaillées par espace naturel protégé

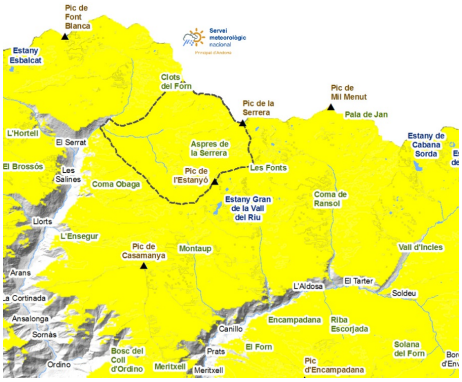

SORTENY

Sur les versants sud, les traînées de percolation d'eau ont été à nouveau exposées, ce qui nous donne des signes de stabilité. Le matin cependant, la neige dure doit nous obliger à prendre d'extrêmes précautions pour ne pas glisser. Sur le versant nord, on identifiera les accumulations de neige soufflée par leur couleur. Il sera toujours plus sûr, en termes de stabilité aux avalanches, de rouler dans de la neige dure. , , , , , , ,

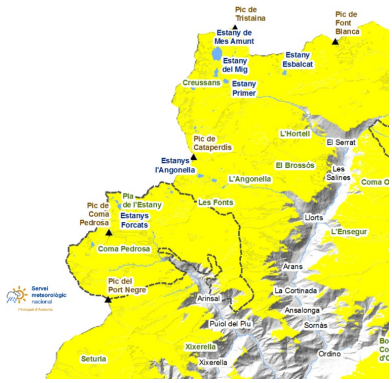

COMAPEDROSA

Vous pouvez encore faire de nombreuses excursions avec des skis de montagne, mais les parties basses d'Arinsal n'ont pas de neige. Soit il faudra l'approcher à ski, soit il faudra y accéder via Soulcem ou l'Angonella. Nous devrons y accéder tôt le matin, car nous devons avoir suffisamment de temps pour revenir lorsque la neige ne se sera pas encore excessivement transformée. , , , , ,

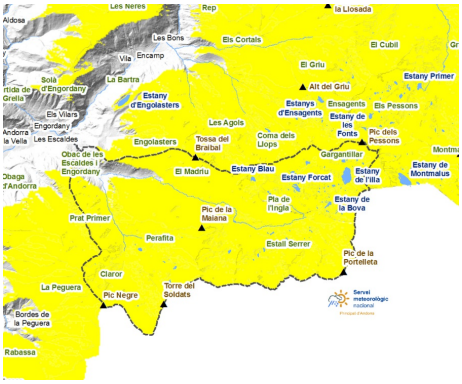

MADRIU-PERAFITA-CLAROR

Les conditions sont printanières, mais sur les versants nord plus raides et plus opaques, on peut encore trouver un peu de neige sèche qu'il faudra éviter. ,

BUTLLETÍ DEL PERILL D'ALLAUS DEL PRINCIPAT D'ANDORRA

Servei meteorològic nacional
Principat d'Andorra

Couche de neige fraiche des derniers jours (De 24 h mesurée à 06:00 h UTC)

	05/04/2026	06/04/2026	07/04/2026	08/04/2026
FEDA (Central)	0 cm	0 cm	0 cm	0 cm
Engolasters - FEDA	0 cm	0 cm	0 cm	0 cm
Bony de les Neres	0 cm	0 cm	0 cm	0 cm
Sorteny	0 cm	0 cm	0 cm	0 cm
Les Fonts d'Arinsal	0 cm	0 cm	0 cm	0 cm
Aixàs	0 cm	0 cm	0 cm	0 cm
Perafita	0 cm	0 cm	0 cm	0 cm
Tossa Espiolets	0 cm	0 cm	0 cm	0 cm
Grau Roig - FEDA	0 cm	0 cm	0 cm	0 cm
Fontverd	0 cm	0 cm	0 cm	0 cm
Coll Ordino	0 cm	0 cm	0 cm	0 cm
Ransol - FEDA	0 cm	0 cm	0 cm	0 cm
Setúria	0 cm	0 cm	0 cm	0 cm
Caborreu	0 cm	0 cm	0 cm	0 cm
La Solana	0 cm	0 cm	0 cm	0 cm
Coll Pa	0 cm	0 cm	0 cm	0 cm
Envalira Antenes	0 cm	0 cm	0 cm	0 cm
Vall del Riu FEDA	0 cm	0 cm	0 cm	0 cm