MINISTERO DELLA DIFESA

meteomont Servizio Nazionale di previsione neve e valanghe

EAWS EUROPEAN AVALANCHE WARNING SERVICES

CARABINIERI

# APPENNINO EMILIANO CENTRALE

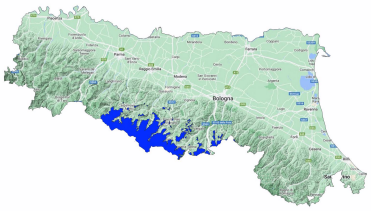

Bollettino Valanghe N. 371/2026 del 08/04/2026 ore 14.00
Validità 48 ore prossima emissione 09/04/2026

**A cura del Servizio METEOMONT dell'ARMA dei CARABINIERI**
**In collaborazione con Servizio Meteorologico dell'Aeronautica militare**

## SITUAZIONE alle 14:00 del 08/04/2026

**SITUAZIONE TIPO: situazione primaverile.**

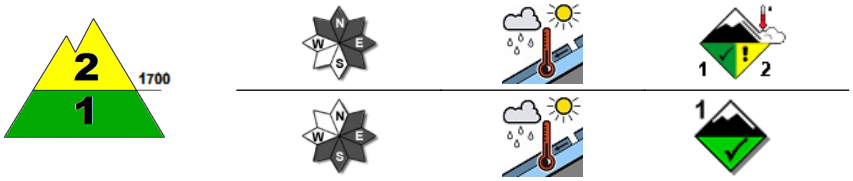


**SITUAZIONE TIPO: situazione primaverile.**

| Quota neve (mslm) | Nord | Sud |
|---|---|---|
| | 1500 | 1700 |

| Altezza Neve (cm) | Neve al suolo | Neve Fresca | Quota (mslm) |
|---|---|---|---|
| | 120 | 000 | 1850 |
| | 33 | 000 | 1550 |

**VALANGHE OSSERVATE: Nessuna valanga.**

## PREVISIONI 09/04/2026

## GRADO DI PERICOLO: MODERATO 2

## SITUAZIONE TIPO: situazione primaverile.




## SITUAZIONE TIPO: situazione primaverile.

**MANTO NEVOSO: La stabilità del manto nevoso è scarsa su alcuni punti (aree) per versanti da nord ovest a sud est compresi al di sopra di 1700 mslm, possibili valanghe di dimensioni medie.**
**La stabilità del manto nevoso è discreta su pochi punti (aree) per versanti da nord est a sud ovest al di sotto di 1700 mslm, possibili valanghe di dimensioni medie.**

## AVVERTENZE

Il rialzo termico diurno richiede un'attenta valutazione temporale dell'escursione che eviti l'attraversamento di pendii ripidi nelle ore più calde della giornata.

## SCALA EUROPEA DEL GRADO DI PERICOLO VALANGHE

5 - MOLTO FORTE | 4 - FORTE | 3 - MARCATO | 2 - MODERATO | 1 - DEBOLE | NO NEVE | NO INFO

## LEGENDA PROBLEMA

NEVE FRESCA | LASTRONI DA VENTO | STRATI DEBOLI PERSISTENTI | NEVE BAGNATA | SLITTAMENTO | CORNICI | NESSUN PROBLEMA VALANGHIVO EVIDENTE | NO_INFO

**Bollettino realizzato su scala sinottica-regionale (standard EAWS). La sua valutazione non può escludere in alcun modo la necessità di una seria e capace valutazione locale del pericolo (singolo pendio) che può essere anche sensibilmente diverso. Le previsioni meteorologiche sono relative all'orario UTC (per l'Italia +1 in inverno e +2 in estate).**

MINISTERO DELLA DIFESA

meteomont
Servizio Nazionale di previsione neve e valanghe

EAWS EUROPEAN AVALANCHE WARNING SERVICES

CARABINIERI

# APPENNINO EMILIANO CENTRALE

## PREVISIONE METEO

| Quota | | 09/04/2026 h6:00 | 09/04/2026 h12:00 | 09/04/2026 h18:00 |
|---|---|---|---|---|
| 1000 | Venti | 02 Nodi da Ovest | 02 Nodi da Nord | 01 nodi da N-Ovest |
| | Temperature | +09 °C | +14 °C | +11 °C |
| | Temp.percepita | 9 °C | 14 °C | 11 °C |
| 2000 | Venti | 05 nodi da N-Ovest | 04 Nodi da Ovest | 09 nodi da N-Ovest |
| | Temperature | +08 °C | +07 °C | +08 °C |
| | Temp.percepita | 6 °C | 6 °C | 5 °C |
| 3000 | Venti | 07 nodi da N-Ovest | 09 nodi da N-Ovest | 12 Nodi da Nord |
| | Temperature | +03 °C | +02 °C | +02 °C |
| | Temp.percepita | -0 °C | -2 °C | -3 °C |
| Zero termico | | 3300-3500 m. | 3200-3400 m. | 3200-3400 m. |
| Fenomeno | | — | — | — |
| Stato del cielo | | | | |

## LEGENDA FENOMENI

— Assenza Fenomeni
Nebbia
Foschia
Pioggia debole
Pioggia moderata
Pioggia forte
Temporali
Nevicata debole
Nevicata moderata
Nevicata forte

## STATO DEL CIELO

Sereno
Poco nuvoloso
Nuvoloso
Molto nuvoloso
Coperto

## Parametri meteonivometrici registrati presso i campi di rilevamento il 08/04/2026.

| Località | Comune | Quota (m.s.l.m.) | Altezza neve (cm) | Neve caduta nelle 24 ore (cm) | Temp. Min (°C) | Temp. Max (°C) | Condizioni del tempo |
|---|---|---|---|---|---|---|---|
| LAGO DELLA NINFA | Sestola (MO) | 1550 | 26 | 0 | +7 | +12 | Assenza di precipitazioni |
| PIANCAVALLARO | Riolunato (MO) | 1840 | 113 | 0 | -2 | +8 | Assenza di precipitazioni |

**(*) Rilievi fuori campo**

**L'INFORMAZIONE E' PREVENZIONE - LEGGI L'ATTUALE GRADO DI PERICOLO VALANGHE!**

**IL CAPO DEL CENTRO NAZIONALE METEOMONT**
**(Ten. Col. RFI Emanuela Gini)**
**FIRMA AUTOGRAFA OMESSA AI SENSI**
**DELL'ART.3 DEL D.LGS N.39/1993**