Bulletin d'estimation du risque d'avalanche
(valable en dehors des pistes balisées et ouvertes)
MASSIF : Chablais

Rédigé le jeudi 9 avril 2026 à 15h

Estimation des risques pour le : VENDREDI 10 AVRIL

FORTE HUMIDIFICATION DU MANTEAU NEIGEUX À MOYENNE ALTITUDE.

3

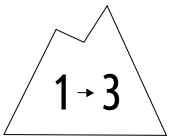

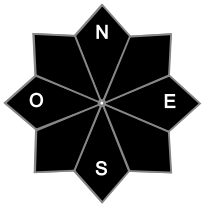

Indice de risque faible évoluant en marqué.

Départs spontanés : Nombreuses avalanches de neige humide, parfois grandes dans les configurations défavorables.

Déclenchements provoqués : Avalanches de neige humide sous les skis.

Indices de risque : 5 très fort - 4 fort - 3 marqué - 2 limité - 1 faible -- En noir : les pentes les plus dangereuses

Stabilité du manteau neigeux

Situation avalancheuse typique : neige humide couche fragile persistante

Départs spontanés :
* **Nombreuses avalanches de neige humide**, de plus en plus nombreuses au fil du réchauffement et de l'ensoleillement. En adrets, l'humidification commence dès le lever du soleil. Globalement **à toutes altitudes et orientations, l'humidification est sensible**, notamment près des rochers et des falaises. Taille 1 à 2.
* Ces avalanches superficielles de neige humide peuvent réussir à déclencher, en cascade, une couche fragile enfouie sous 30/40 cm.
* Des **avalanches de fond** sont possibles à toute heure du jour et de la nuit, sur les pentes herbeuses ou les dalles rocheuses. Lorsque ces plaques de fond cèdent, elles peuvent solliciter une **couche fragile persistante enfouie sous 1m/1m20 de neige**. Ces couches fragiles sont présentes entre **1800 et 2500m**. Taille 2 à 3 (moyenne à grande)

Déclenchements provoqués :
* Au passage d'un skieur, de **la neige peut couler sous les skis**. Ces avalanches sont sensibles au soleil. La neige poussée par le skieur peut réussir à déclencher une plaque de 30/40 cm d'épaisseur. Taille 1 à 2 (petite à moyenne).
* Attention au déclenchement en cascade pouvant solliciter des couches fragiles enfouies profondément.

Autres :
* Avec les fortes chaleurs, attentions aux chutes de pierre et aux corniches qui cèdent.

Qualité de la neige

Enneigement :
L'enneigement est correct au-dessus de 2000m. En dessous, il commence à être déficitaire.
On peut chausser les skis au-dessus de 1700/1800 m en sud et 1400/1500 m en nord. Des traces de neige sont présentes sous ces altitudes, mais l'enneigement est loin d'être continu.

Qualité de la neige ce vendredi :
En dessous de 2000 m en nord à toutes altitudes en sud, manteau neigeux printanier. Humidification rapide et profonde au soleil.
En matinée, croute de regel (du au regel nocturne plutôt correcte) portante sur de la vielle neige dense, s'humidifiant un peu au soleil.

Aperçu météo pour le vendredi 10 avril

	nuit	matin	après-midi	soir

Encore une belle journée, toujours placée sous le signe de la chaleur.

Pluie-Neige				
Iso 0 °C	2 800 m	2 700 m	3 100 m	3 000 m
Vent 2000 m	↘ 10 km/h	↘ 15 km/h	→ 15 km/h	↗ 25 km/h
Vent 2500 m	↓ 20 km/h	↘ 25 km/h	↗ 20 km/h	→ 30 km/h

Épaisseur de neige hors-piste

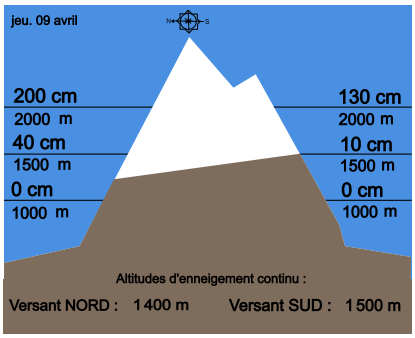

Précipitations à 1800 m

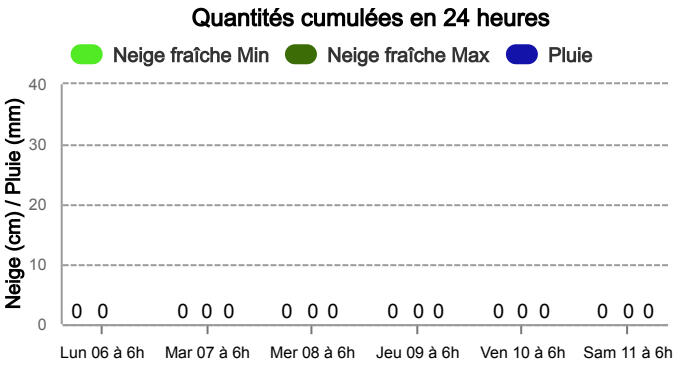

Tendance du samedi 11 avril

3 **Indice de risque marqué**

Samedi : Quelques cumulus l'après-midi, avec un ciel se voilant au fur et a mesure de la journée. Isotherme 0°C vers 3000m. Un peu de vent en haute-montagne.
⇒ le manteau neigeux continue de s'humidifier en profondeur. Encore des avalanches de neige humide et des départs en plaque de fond.

Pour consulter la vigilance en cours, veuillez vous rendre sur le site https://vigilance.meteofrance.fr/fr

Météo-France - 73 avenue de Paris, 94165 Saint-Mandé cedex - Contact : contact@meteo.fr

Rédigé par Météo-France avec la contribution des observateurs du réseau nivo-météorologiques. Partenariat : ANMSM (Maires de Stations de Montagne), DSF (Domaines Skiables de France), ADSP (Directeurs de Pistes et de la Sécurité des Stations de Sports d'Hiver) et autres acteurs de la montagne.

Bulletin neige & avalanches par téléphone au
0 892 68 10 20 Service 0,35 € / min + prix appel

RÉPUBLIQUE FRANÇAISE
Liberté Égalité Fraternité

METEO FRANCE
À VOS CÔTÉS, DANS UN CLIMAT QUI CHANGE

Bulletin d'estimation du risque d'avalanche
(valable en dehors des pistes balisées et ouvertes)

MASSIF : Chablais

Rédigé le jeudi 9 avril 2026 à 15h

Conditions nivo-météo des 7 derniers jours

	ven. 03/04				sam. 04/04				dim. 05/04				lun. 06/04				mar. 07/04				mer. 08/04				jeu. 09/04			
	03h	09h	15h	21h	03h	09h	15h	21h	03h	09h	15h	21h	03h	09h	15h	21h	03h	09h	15h	21h	03h	09h	15h	21h	03h	09h	15h	21h
Météo																												
Vent (km/h)	40	20	15	15	20	15	5	10	25	30	50	40	40	30	30	20	15	10	5	10	20	25	10	5	10	15	10	15
à 2500m																												
Vent (km/h)	20	15	10	5	10	10	0	5	15	20	35	25	25	20	15	10	10	10	5	5	20	25	5	5	5	10	5	5
à 2000m																												

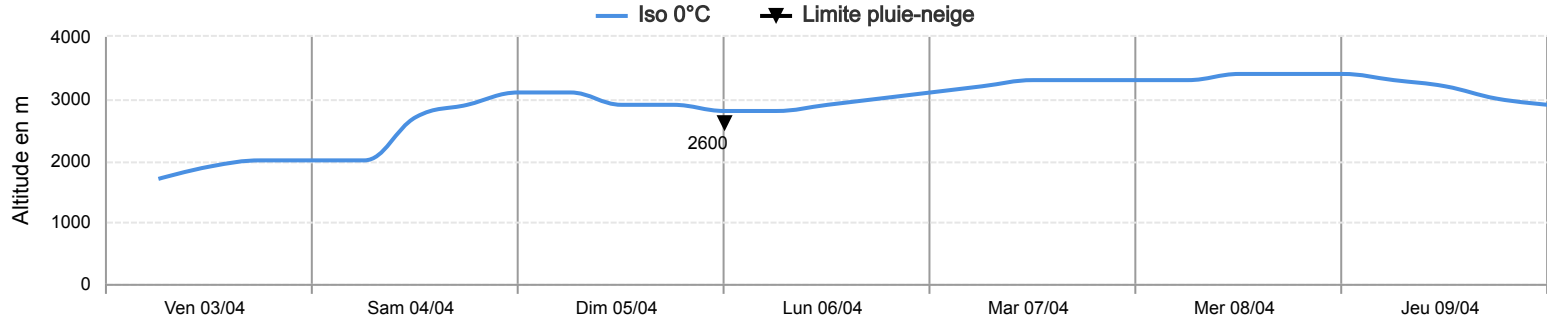

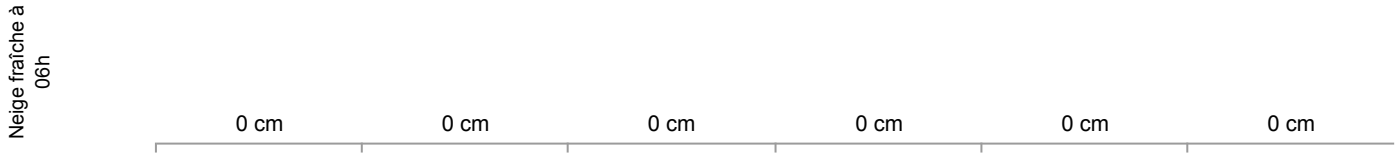

Risque d'avalanche	ven. 03/04	sam. 04/04	dim. 05/04	lun. 06/04	mar. 07/04	mer. 08/04	jeu. 09/04
	2	2	2	2	2	2	3

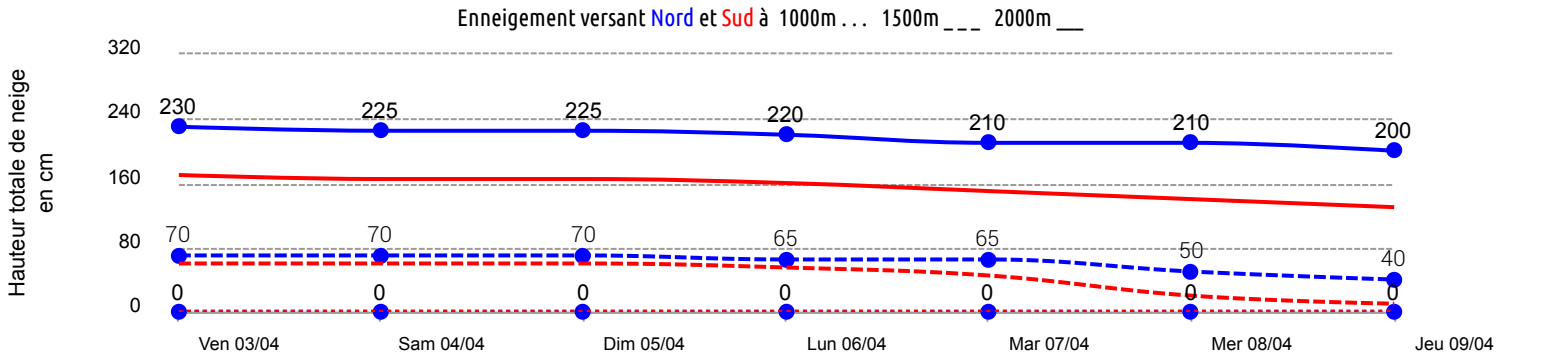

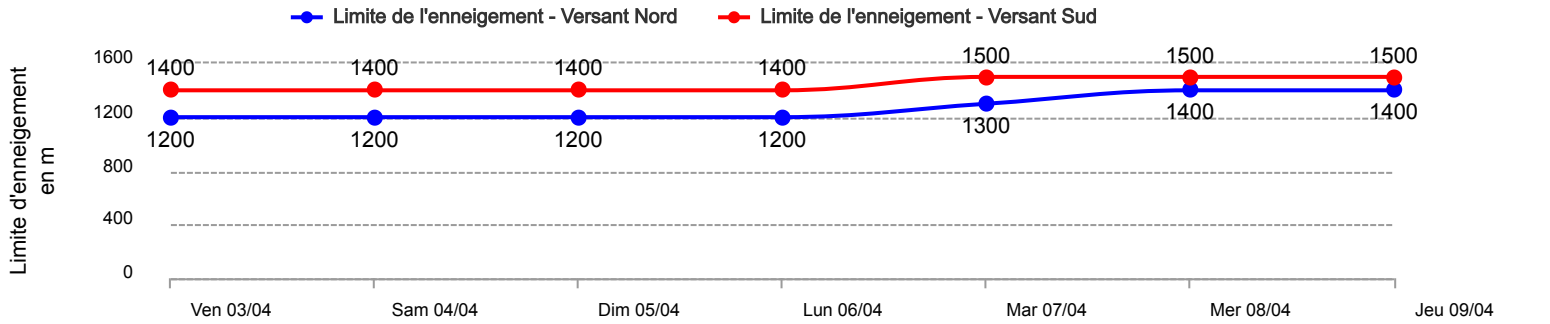

Pour consulter la vigilance en cours, veuillez vous rendre sur le site https://vigilance.meteofrance.fr/fr

Météo-France - 73 avenue de Paris, 94165 Saint-Mandé cedex - Contact : contact@meteo.fr

Rédigé par Météo-France avec la contribution des observateurs du réseau nivo-météorologiques. Partenariat : ANMSM (Maires de Stations de Montagne), DSF (Domaines Skiables de France), ADSP (Directeurs de Pistes et de la Sécurité des Stations de Sports d'Hiver) et autres acteurs de la montagne.

Bulletin neige & avalanches par téléphone au
0 892 68 10 20 Service 0,35 € / min + prix appel