RÉPUBLIQUE FRANÇAISE
Liberté Égalité Fraternité

METEO FRANCE
À VOS CÔTÉS, DANS UN CLIMAT QUI CHANGE

Bulletin d'estimation du risque d'avalanche
(valable en dehors des pistes balisées et ouvertes)

MASSIF : Aure Louron

Rédigé le jeudi 9 avril 2026 à 16h

Estimation des risques pour le : VENDREDI 10 AVRIL

PEU D'EVOLUTION : NEIGE DE RPINTEMPS MAJORITAIRE, QUELQUES STRUCUTRES DE PLAQUES EN NORD D'ALTITUDE.

2

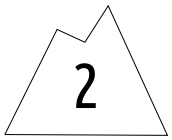

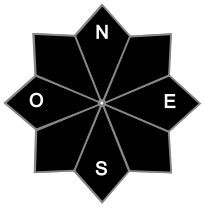

Indice de risque limité.

Départs spontanés : en neige humide, quelques avalanches de fond possibles en sud d'altitude.

Déclenchements provoqués : possibles par faible sollicitation de la neige humide et des quelques structures de plaques encore présentes.

Indices de risque : 5 très fort - 4 fort - 3 marqué - 2 limité - 1 faible -- En noir : les pentes les plus dangereuses

Stabilité du manteau neigeux

Situation avalancheuse typique : neige humide couche fragile persistante

Déclenchements provoqués :
- **au-dessus de 2600 à 2700m** dans les **pentes raides autour du secteur nord**, des **structures de plaques persistent**, formées la semaine dernière lors des chutes de neige ventées. Ces structures, encore **assez compactes et peu humidifiées si ce n'est en surface**, reposent souvent sur une **couche fragile persistante**. Cette couche fragile est **sensible à des sollicitations faibles à parfois moyennes**, notamment **aux abords des combes chargées et des ruptures de pente**; un seul skieur ou randonneur peut donc localement et facilement déclencher une a**valanche de taille petite à moyenne**, parfois **grande par effet de cascade** entraînant la neige mobilisable, plus ou moins humide, en contrebas. ***Observables***: *travail du vent encore assez visible même si la surface neigeuse devient plus uniforme avec l'humidification en cours.*
- **partout ailleurs**, la **neige de printemps domine** : peu probables de déclencher la moindre coulée au petit matin après un bon regel nocturne. Puis, au fil des heures de la journée, **au soleil et dans la douceur ambiante**, il devient **de plus en plus facile pour un skieur ou randonneur** de déclencher des **coulées ou petites avalanches de neige humide**. Une **avalanche de taille moyenne** peut être déclenchée **l'après-midi dans les pentes sud à sud-ouest raides** encore bien enneigées sur le **haut du massif**.

Départs spontanés :
- activité avalancheuse **inexistante ou très rare au petit matin** suite au **bon regel nocturne** du manteau neigeux en place.
- **départs ponctuels de neige humide** en **secteurs raides près des rochers et des zones déneigées**, en **est à sud en matinée** puis en **sud à ouest l'après-midi**. Avalanches **généralement de petite taille**, **quelques avalanches de taille moyenne** possibles **au-dessus de 2200/2300m** en partant d'une accumulation encore en place, **rares** avalanches de **grande taille** (3) **au-dessus de 2500m** avec le départ d'une plaque de fond entraînant la neige humide et lourde mobilisable en contrebas (plutôt l'après-midi).

Autres : neige **dure et regelée** propice aux **glissades en début de matinée, persistante à l'ombre au-dessus de 2700m**. **Ponts de neige** et **corniches** encore en place devenant **fragiles au soleil.**

Qualité de la neige

Enneigement : encore bon pour la saison grâce à une fonte lente, débutant vers 1600m en nord, 1800m en sud.
État de la neige : poursuite de l'humidification.
- conditions de neige de printemps majoritaires : après un regel nocturne efficace, la neige dure et glissante ramollit vite au soleil et dans la douceur ambiante, devenant lourde et très humide. Effets du soleil et de la douceur un peu plus lent dans les pentes nord raides.
- au-dessus de 2700m dans les pentes raides (supérieures à 35°), neige encore froide et sèche, plus ou moins travaillée par le vent et par endroit durcie et regelée en surface. Humidification lente et gagnant peu en profondeur dans le manteau neigeux compacté par le vent dans ces secteurs.

Aperçu météo pour le vendredi 10 avril

	nuit	matin	après-midi	soir
Temps sec et encore bien doux. Le vent de sud-ouest se lève en fin de journée et nuit suivante.				
Pluie-Neige				
Iso 0 °C	3 300 m	3 400 m	3 400 m	3 500 m
Vent 1500 m	5 km/h	5 km/h	10 km/h	15 km/h
Vent 3000 m	20 km/h	30 km/h	35 km/h	40 km/h

Pour consulter la vigilance en cours, veuillez vous rendre sur le site https://vigilance.meteofrance.fr/fr

Météo-France - 73 avenue de Paris, 94165 Saint-Mandé cedex - Contact : contact@meteo.fr

Rédigé par Météo-France avec la contribution des observateurs du réseau nivo-météorologiques. Partenariat : ANMSM (Maires de Stations de Montagne), DSF (Domaines Skiables de France), ADSP (Directeurs de Pistes et de la Sécurité des Stations de Sports d'Hiver) et autres acteurs de la montagne.

Bulletin neige & avalanches par téléphone au
0 892 68 10 20 Service 0,35 € / min + prix appel

Bulletin d'estimation du risque d'avalanche

(valable en dehors des pistes balisées et ouvertes)

MASSIF : Aure Louron

Rédigé le jeudi 9 avril 2026 à 16h

Épaisseur de neige hors-piste

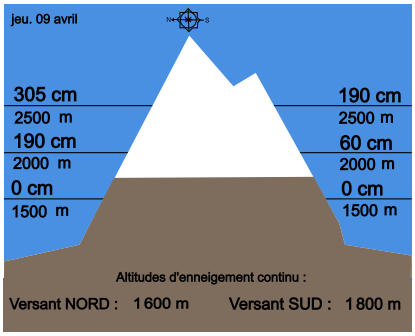

Précipitations à 1800 m

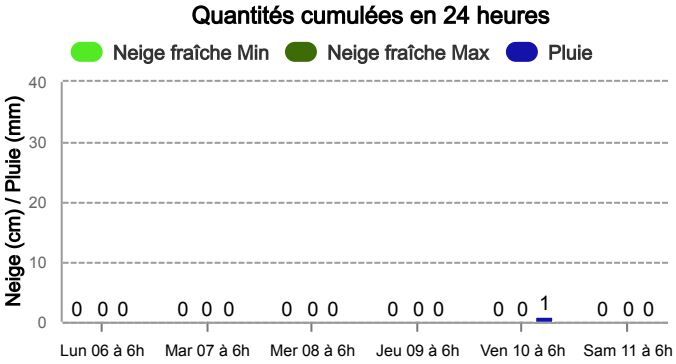

Tendance du samedi 11 avril

Indice de risque limité

Plus de nuages, rares gouttes de pluie l'après-midi : maintien d'un risque limité en journée de samedi.
Par contre, augmentation rapide du risque en cours de nuit de samedi à dimanche avec les nouvelles chutes de neige plus ou moins ventées, attendues jusqu'à basse altitude.

Pour consulter la vigilance en cours, veuillez vous rendre sur le site https://vigilance.meteofrance.fr/fr

Météo-France - 73 avenue de Paris, 94165 Saint-Mandé cedex - Contact : contact@meteo.fr

Rédigé par Météo-France avec la contribution des observateurs du réseau nivo-météorologiques. Partenariat : ANMSM (Maires de Stations de Montagne), DSF (Domaines Skiables de France), ADSP (Directeurs de Pistes et de la Sécurité des Stations de Sports d'Hiver) et autres acteurs de la montagne.

Bulletin neige & avalanches par téléphone au

0 892 68 10 20 Service 0,35 € / min + prix appel

RÉPUBLIQUE FRANÇAISE
Liberté Égalité Fraternité

METEO FRANCE
À VOS CÔTÉS, DANS UN CLIMAT QUI CHANGE

Bulletin d'estimation du risque d'avalanche

(valable en dehors des pistes balisées et ouvertes)

MASSIF : Aure Louron

Rédigé le jeudi 9 avril 2026 à 16h

Conditions nivo-météo des 7 derniers jours

	ven. 03/04				sam. 04/04				dim. 05/04				lun. 06/04				mar. 07/04				mer. 08/04				jeu. 09/04			
	03h	09h	15h	21h	03h	09h	15h	21h	03h	09h	15h	21h	03h	09h	15h	21h	03h	09h	15h	21h	03h	09h	15h	21h	03h	09h	15h	21h
Météo																												
Vent (km/h)	75	55	25	20	15	25	25	30	30	20	20	20	15	25	35	40	45	40	30	20	30	20	20	25	20	20	15	10
à 3000m																												
Vent (km/h)	35	10	5	10	10	15	10	5	10	15	10	10	10	10	10	15	25	20	20	20	10	15	10	5	5	5	5	2
à 1500m																												

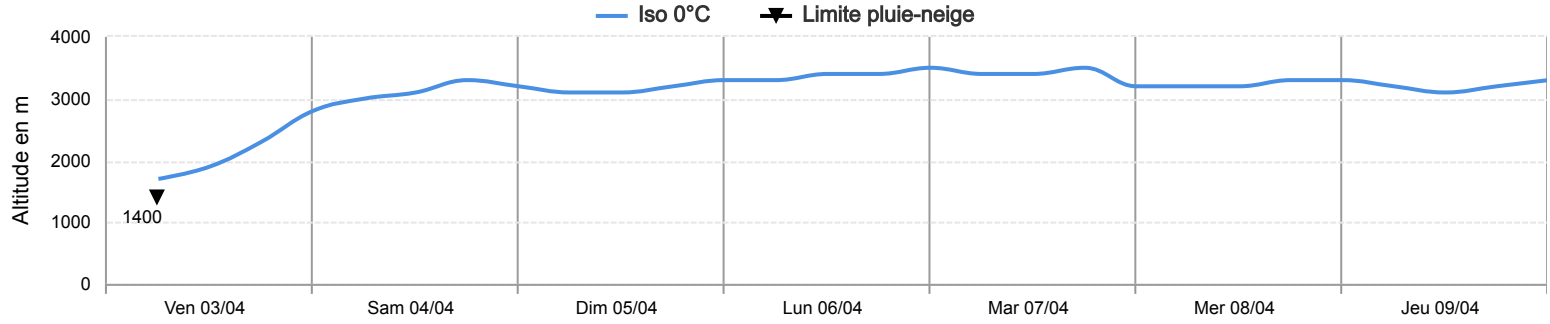

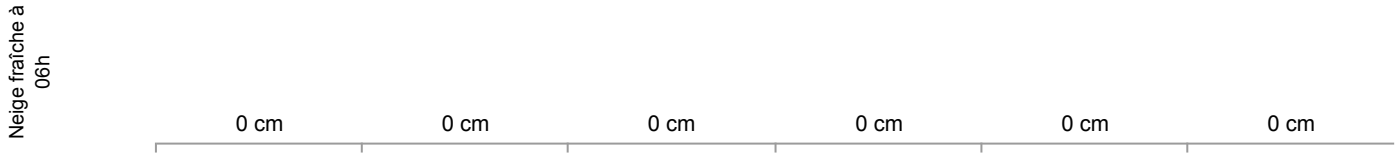

Risque d'avalanche	ven. 03/04	sam. 04/04	dim. 05/04	lun. 06/04	mar. 07/04	mer. 08/04	jeu. 09/04
	4	3	2	2	2	2	2

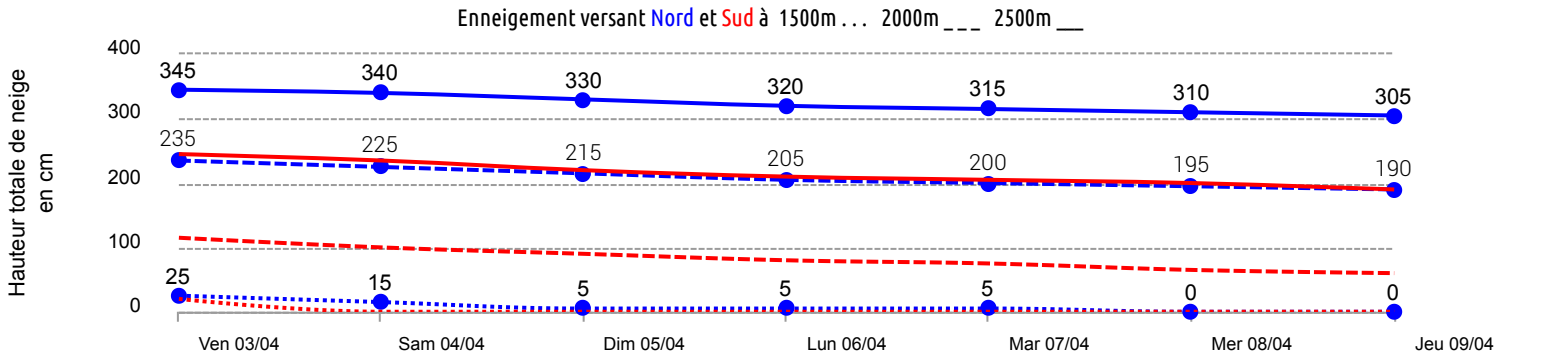

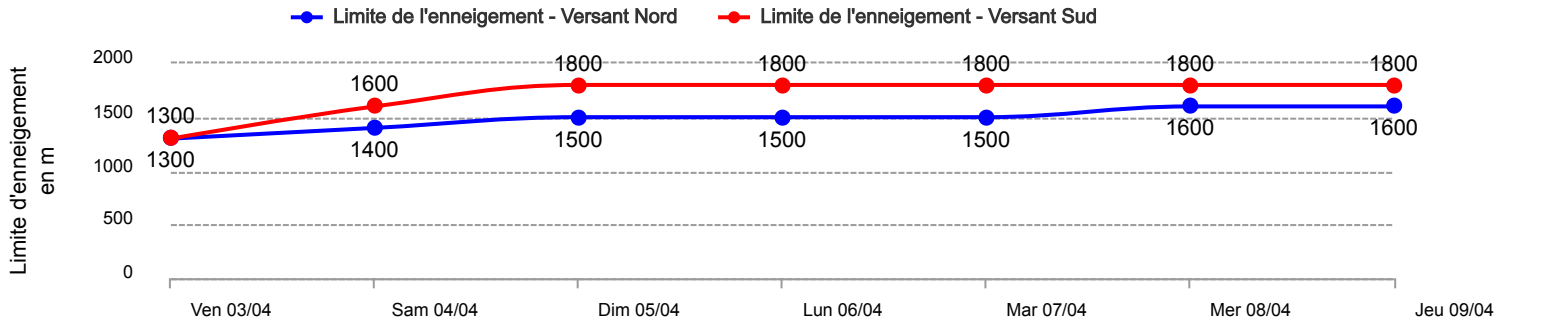

Pour consulter la vigilance en cours, veuillez vous rendre sur le site https://vigilance.meteofrance.fr/fr

Météo-France - 73 avenue de Paris, 94165 Saint-Mandé cedex - Contact : contact@meteo.fr

Rédigé par Météo-France avec la contribution des observateurs du réseau nivo-météorologiques. Partenariat : ANMSM (Maires de Stations de Montagne), DSF (Domaines Skiables de France), ADSP (Directeurs de Pistes et de la Sécurité des Stations de Sports d'Hiver) et autres acteurs de la montagne.

Bulletin neige & avalanches par téléphone au
0 892 68 10 20 Service 0,35 € / min + prix appel