Bulletin d'estimation du risque d'avalanche

(valable en dehors des pistes balisées et ouvertes)

MASSIF : Beaufortain

Rédigé le jeudi 9 avril 2026 à 16h

Estimation des risques pour le : VENDREDI 10 AVRIL

FORTE HUMIDIFICATION DU MANTEAU NEIGEUX EN COURS DE JOURNÉE. CONDITIONS PRESQUE ESTIVALES.

2

1 → 2

N O E S

Indice de risque faible évoluant en limité.

Départs spontanés : quelques départs en neige humide au fil du réchauffement de la journée.

Déclenchements provoqués : petites coulées sous les skis en versants ensoleillés.

Indices de risque : 5 très fort - 4 fort - 3 marqué - 2 limité - 1 faible -- En noir : les pentes les plus dangereuses

Stabilité du manteau neigeux

Situation avalancheuse typique : neige humide — avalanches de fond

Départs spontanés : regel nocturne correct après une nuit claire et sans vent. Les premières heures du matin sont calmes puis **reprise, au fil de la course du soleil, des départs en neige humide dans les versants ensoleillés**. D'abord en Nord-Est (raide)/Est puis Sud et enfin **surtout en Ouest et Nord-Ouest en fin de journée.** Avalanches de petite taille (taille 1) en générale. Taille moyenne (taille 2) possible quand la topographie s'y prête ou lors d'un déclenchement en cascade d'une plaque d'aspect humide (cassure linéaire pouvant, dans le pire des cas générer une grande avalanche).
Par ailleurs, des plaques de fond sont à craindre, à toute heure, surtout en Nord sous 2300 m. Aussi, chutes de corniches possibles.

Déclenchements provoqués : avalanche de neige humide (pourrie) **sous les skis en coupant une pente trop ramollie par le Soleil**. Sinon, au-dessus de 2500 m en Nord dans une pente très raide, une petite plaque peut déstabiliser le skieur qui la déclenche.

Qualité de la neige

Enneigement : encore un peu au-dessus de la moyenne, mais plus pour longtemps avec une fonte accélérée de 5 à 10 cm par jour avec la chaleur en cours.

Limite skiable : vers 1200/1300 m en Nord, 1500/1600 m en Sud.

Qualité de la neige : en Nord au-dessus de 2500 m, poudre tassée agréable à l'abri des vents, sinon dans les nombreux secteurs ventés très hétérogènes carton à dure dans les pentes et croupes/crêtes pelées.
Partout ailleurs, regel nocturne correct avec une croûte portante au lever du jour, ramollissant très rapidement dans les versants Est, plus tardivement ailleurs en suivant la course du soleil. Le créneau en neige de printemps agréable à descendre risque d'être court avec une neige devenant vite pourrie. L'après midi, neige pourrie dans un grand nombre de pentes.

Aperçu météo pour le vendredi 10 avril

Ciel finement voilé et très doux.

	nuit	matin	après-midi	soir
Pluie-Neige				
Iso 0 °C	2 800 m	2 800 m	2 900 m	3 000 m
Vent 2000 m	↘ 10 km/h	↘ 15 km/h	→ 25 km/h	↑ 10 km/h
Vent 3000 m	↓ 15 km/h	↓ 20 km/h	→ 30 km/h	↗ 20 km/h

Épaisseur de neige hors-piste

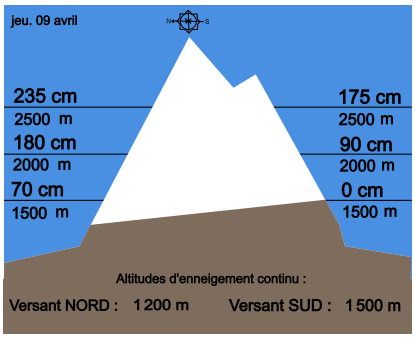

Précipitations à 1800 m

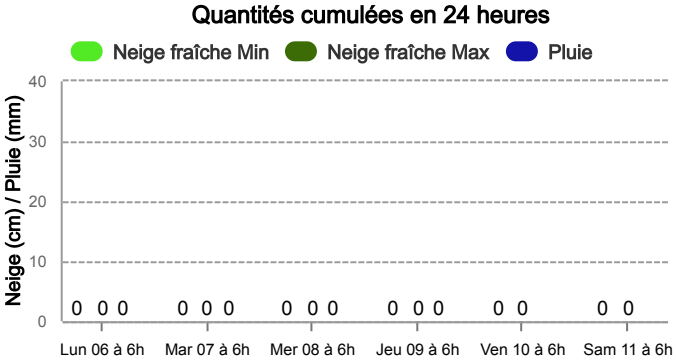

Tendance du samedi 11 avril

2

Indice de risque limité

Excessivement doux, les problématiques en neige humide continuent.
On surveillera l'évolution de l'humidification du manteau neigeux.
Risque stationnaire.

Pour consulter la vigilance en cours, veuillez vous rendre sur le site https://vigilance.meteofrance.fr/fr

Météo-France - 73 avenue de Paris, 94165 Saint-Mandé cedex - Contact : contact@meteo.fr

Rédigé par Météo-France avec la contribution des observateurs du réseau nivo-météorologiques. Partenariat : ANMSM (Maires de Stations de Montagne), DSF (Domaines Skiables de France), ADSP (Directeurs de Pistes et de la Sécurité des Stations de Sports d'Hiver) et autres acteurs de la montagne.

Bulletin neige & avalanches par téléphone au **0 892 68 10 20** Service 0,35 € / min + prix appel

RÉPUBLIQUE FRANÇAISE
Liberté Égalité Fraternité

METEO FRANCE
À VOS CÔTÉS, DANS UN CLIMAT QUI CHANGE

Bulletin d'estimation du risque d'avalanche

(valable en dehors des pistes balisées et ouvertes)

MASSIF : Beaufortain

Rédigé le jeudi 9 avril 2026 à 16h

Conditions nivo-météo des 7 derniers jours

	ven. 03/04				sam. 04/04				dim. 05/04				lun. 06/04				mar. 07/04				mer. 08/04				jeu. 09/04			
	03h	09h	15h	21h	03h	09h	15h	21h	03h	09h	15h	21h	03h	09h	15h	21h	03h	09h	15h	21h	03h	09h	15h	21h	03h	09h	15h	21h
Météo																												
Vent (km/h)	30	30	25	25	20	20	15	15	15	20	20	20	30	20	15	15	10	5	5	15	15	10	5	5	10	20	30	15
à 3000m																												
Vent (km/h)	20	20	20	15	10	10	10	10	10	15	15	15	15	10	10	10	5	0	5	5	10	5	0	0	5	15	25	10
à 2000m																												

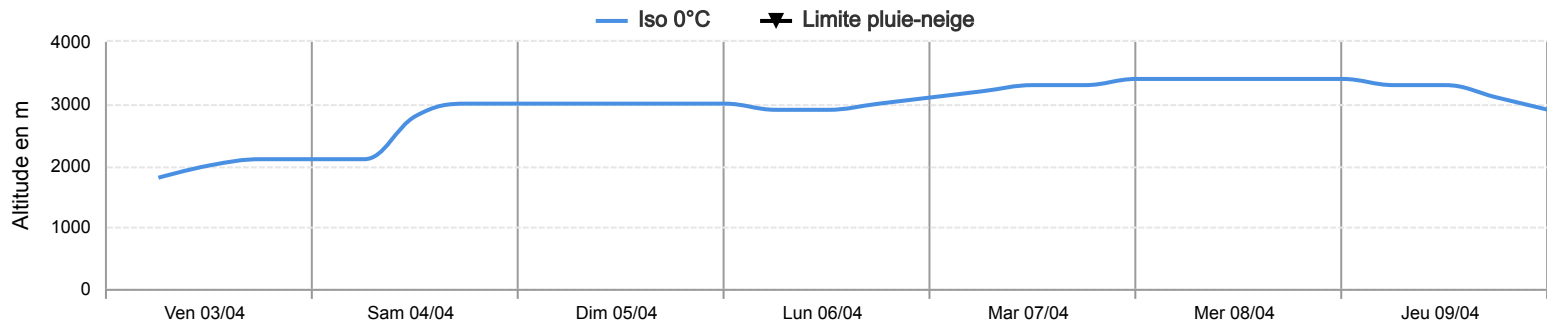

Neige fraîche à 06h

ven. 03/04	sam. 04/04	dim. 05/04	lun. 06/04	mar. 07/04	mer. 08/04	jeu. 09/04
0 cm	0 cm	0 cm	0 cm	0 cm	0 cm	

Risque d'avalanche	ven. 03/04	sam. 04/04	dim. 05/04	lun. 06/04	mar. 07/04	mer. 08/04	jeu. 09/04
	2	2	2	2	2	2	2

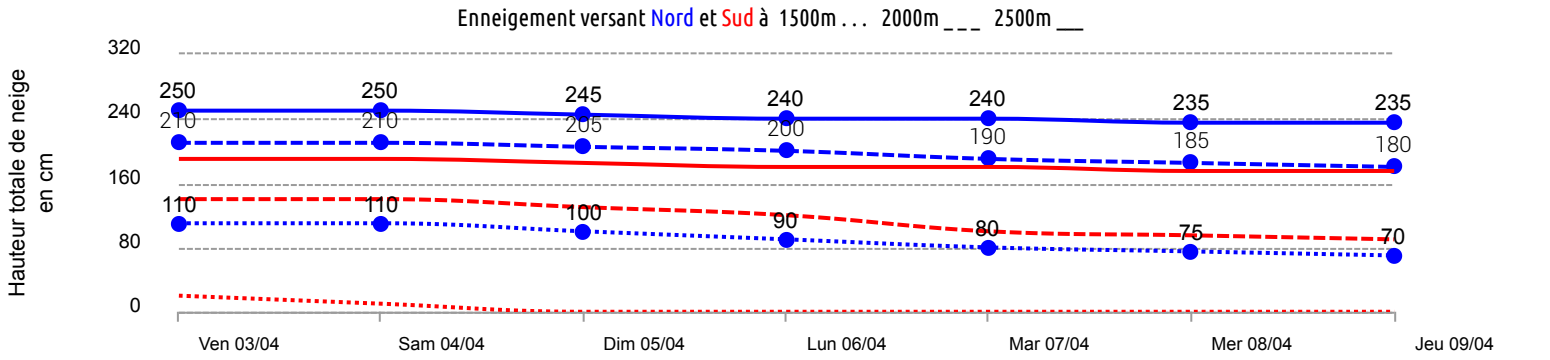

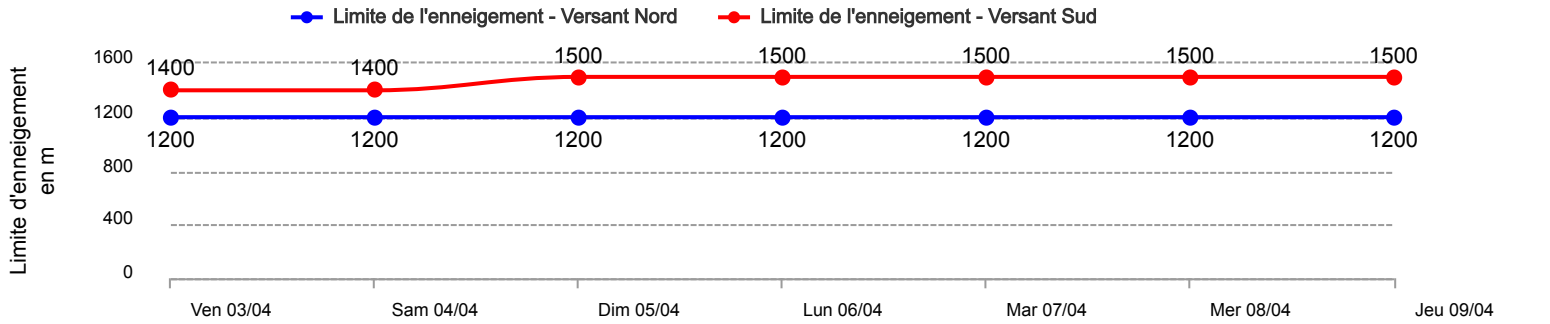

Pour consulter la vigilance en cours, veuillez vous rendre sur le site https://vigilance.meteofrance.fr/fr

Météo-France - 73 avenue de Paris, 94165 Saint-Mandé cedex - Contact : contact@meteo.fr

Bulletin neige & avalanches par téléphone au

0 892 68 10 20 Service 0,35 € / min + prix appel

Rédigé par Météo-France avec la contribution des observateurs du réseau nivo-météorologiques. Partenariat : ANMSM (Maires de Stations de Montagne), DSF (Domaines Skiables de France), ADSP (Directeurs de Pistes et de la Sécurité des Stations de Sports d'Hiver) et autres acteurs de la montagne.