RÉPUBLIQUE FRANÇAISE
Liberté Égalité Fraternité

METEO FRANCE
À VOS CÔTÉS, DANS UN CLIMAT QUI CHANGE

Bulletin d'estimation du risque d'avalanche
(valable en dehors des pistes balisées et ouvertes)

MASSIF : Mercantour

Rédigé le jeudi 9 avril 2026 à 16h

Estimation des risques pour le : VENDREDI 10 AVRIL

CONDITIONS PRINTANIÈRES. DÉPARTS EN NEIGE HUMIDE PARFOIS TRÈS VOLUMINEUX

3

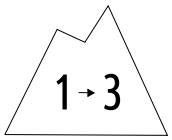

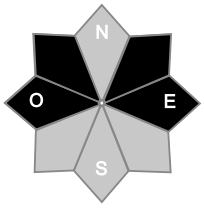

Indice de risque faible évoluant en marqué.

Départs spontanés : en neige humide, parfois linéaires et de grande taille

Déclenchements provoqués : départs ponctuels en neige humide ou avalanches de plaque dans la niege d'aspect humifiée, facile à déclencher

Indices de risque : 5 très fort - 4 fort - 3 marqué - 2 limité - 1 faible -- En noir : les pentes les plus dangereuses

Stabilité du manteau neigeux

Situation avalancheuse typique : neige humide couche fragile persistante

Départs spontanés : - départs généralement ponctuels en neige humide, de taille petite à moyenne. Peu probables en tout début de journée après un bon regel nocturne, puis augmentation suivant la course du soleil. En pentes raides, toutes orientations et altitude, plutôt près des rochers.
- départs linéaires, cassures pouvant être larges et épaisses, engendrant des avalanches de taille moyenne à grande. En seconde partie de journée plus particulièrement au-dessus de 2200/2400 m, dans les orientations est à nord-est et ouest à nord-ouest bien réchauffées. En effet l'humidification gagne en profondeur et peut atteindre désormais pour la 1ere fois les couches fragiles enfouies à la base du manteau neigeux.

Déclenchements provoqués : le manteau neigeux est bien stable le matin. Les déclenchements d'avalanches concernent ensuite les pentes raides ensoleillées.
- avalanches de plaque dans la neige d'aspect humidifiée pouvant être déclenchées par un seul skieur évoluant tardivement. Orientations privilégiées est / nord / ouest d'altitude. Taille moyenne, voire grande.
- départs ponctuels en neige humide / pourrie sous les skis. Taille petite à moyenne.

Qualité de la neige

Enneigement encore légèrement excédentaire pour la saison.
Hauteurs de neige observées : 122 cm à la nivose de Millefonts à 2430 m, 72 cm à Isola 2000 à 1900 m.

Enneigement skiable généralement à partir de 1700 m en terrain favorable et 2200 m en adrets peu pentus.

État de la neige en surface : manteau neigeux printanier avec un bon regel nocturne, s'humidifiant rapidement en journée. Neige restée sèche seulement en orientations raides et plein nord de haute altitude, mais généralement fortement durcie par le vent.

Aperçu météo pour le vendredi 10 avril

	nuit	matin	après-midi	soir
	Toujours chaud et sec. Soleil voilé. Vent de nord à ouest, faible à modéré.			
Pluie-Neige				
Iso 0 °C	3 400 m	3 300 m	3 400 m	3 500 m
Vent 2000 m	↘ 20 km/h	↗ 15 km/h	↘ 20 km/h	↘ 10 km/h
Vent 3000 m	↘ 30 km/h	→ 25 km/h	→ 30 km/h	→ 20 km/h

Épaisseur de neige hors-piste

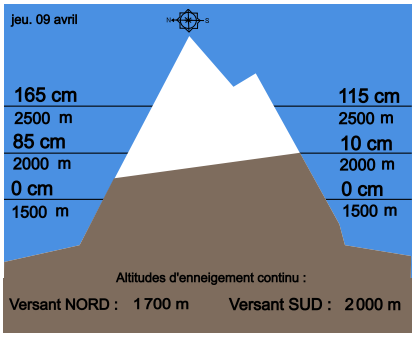

Précipitations à 1800 m

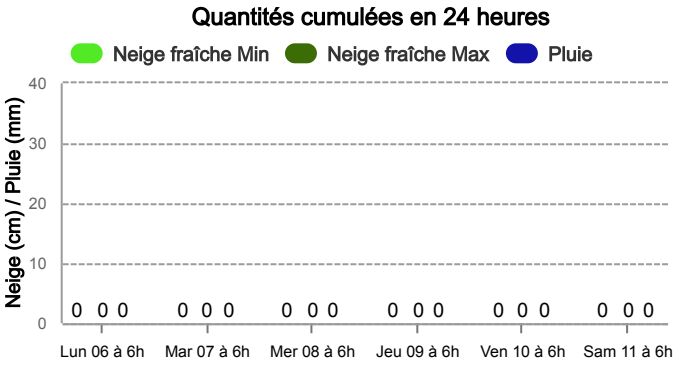

Tendance du samedi 11 avril

3

Indice de risque marqué

Poursuite de conditions printanières et de l'humidification en profondeur du manteau neigeux. Grandes avalanches possibles. Risque restant marqué.

Pour consulter la vigilance en cours, veuillez vous rendre sur le site https://vigilance.meteofrance.fr/fr

Météo-France - 73 avenue de Paris, 94165 Saint-Mandé cedex - Contact : contact@meteo.fr

Rédigé par Météo-France avec la contribution des observateurs du réseau nivo-météorologiques. Partenariat : ANMSM (Maires de Stations de Montagne), DSF (Domaines Skiables de France), ADSP (Directeurs de Pistes et de la Sécurité des Stations de Sports d'Hiver) et autres acteurs de la montagne.

Bulletin neige & avalanches par téléphone au
0 892 68 10 20 Service 0,35 € / min + prix appel

RÉPUBLIQUE FRANÇAISE
Liberté Égalité Fraternité

METEO FRANCE
À VOS CÔTÉS, DANS UN CLIMAT QUI CHANGE

Bulletin d'estimation du risque d'avalanche

(valable en dehors des pistes balisées et ouvertes)

MASSIF : Mercantour

Rédigé le jeudi 9 avril 2026 à 16h

Conditions nivo-météo des 7 derniers jours

	ven. 03/04				sam. 04/04				dim. 05/04				lun. 06/04				mar. 07/04				mer. 08/04				jeu. 09/04			
	03h	09h	15h	21h	03h	09h	15h	21h	03h	09h	15h	21h	03h	09h	15h	21h	03h	09h	15h	21h	03h	09h	15h	21h	03h	09h	15h	21h
Météo																												
Vent (km/h)	25	25	40	35	15	10	20	10	20	25	30	35	30	20	20	15	20	20	25	10	10	15	15	10	15	20	25	25
à 3000m																												
Vent (km/h)	30	20	25	20	15	10	15	10	10	10	20	10	15	10	15	10	10	10	20	10	10	10	20	10	10	10	15	20
à 2000m																												

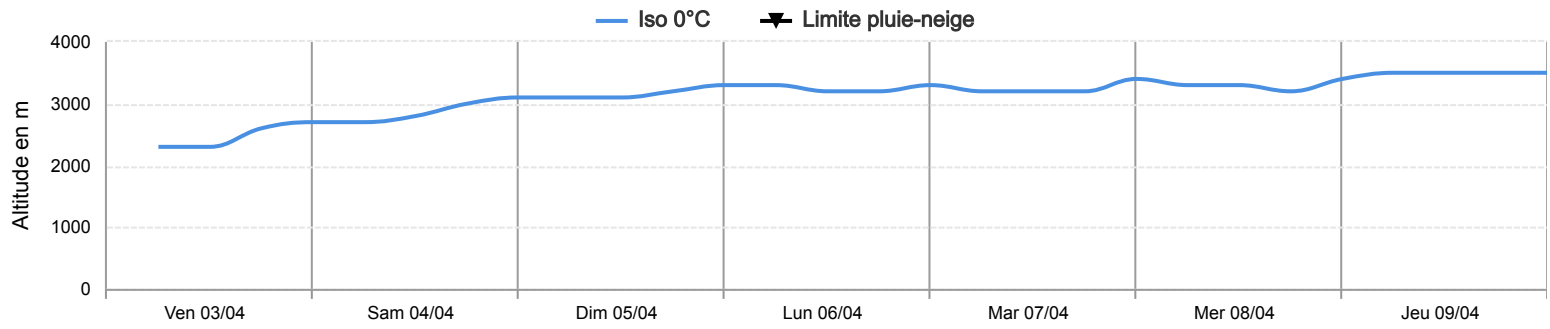

Neige fraîche à 06h

0 cm	0 cm	0 cm	0 cm	0 cm	0 cm

Risque d'avalanche	ven. 03/04	sam. 04/04	dim. 05/04	lun. 06/04	mar. 07/04	mer. 08/04	jeu. 09/04
	1	2	2	2	2	2	3

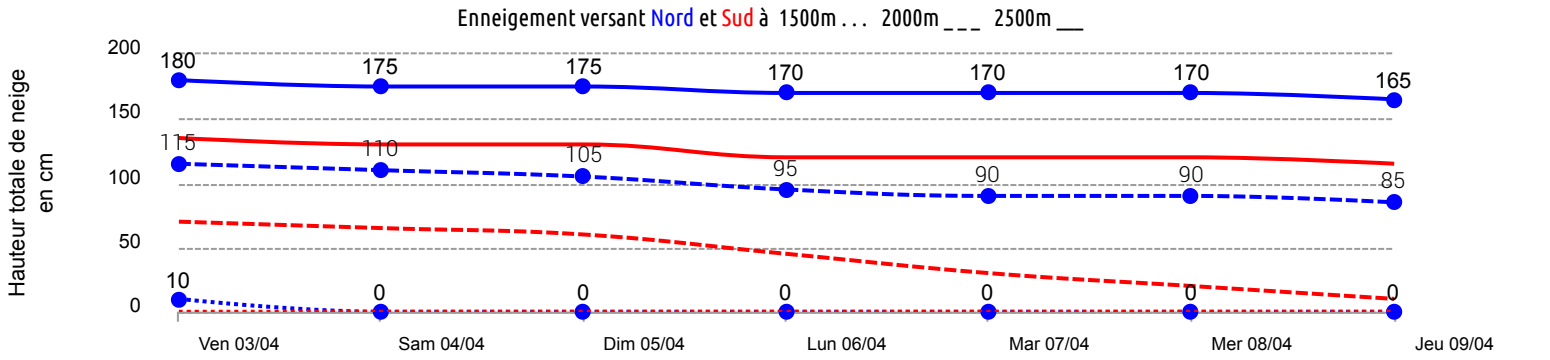

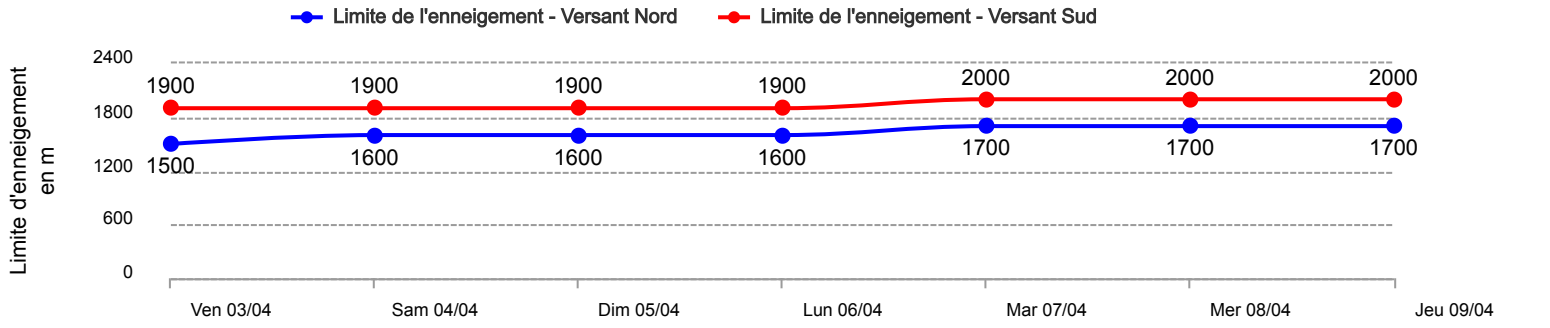

Pour consulter la vigilance en cours, veuillez vous rendre sur le site https://vigilance.meteofrance.fr/fr

Météo-France - 73 avenue de Paris, 94165 Saint-Mandé cedex - Contact : contact@meteo.fr

Rédigé par Météo-France avec la contribution des observateurs du réseau nivo-météorologiques. Partenariat : ANMSM (Maires de Stations de Montagne), DSF (Domaines Skiables de France), ADSP (Directeurs de Pistes et de la Sécurité des Stations de Sports d'Hiver) et autres acteurs de la montagne.

Bulletin neige & avalanches par téléphone au
0 892 68 10 20 Service 0,35 € / min + prix appel