Bulletin d'estimation du risque d'avalanche
(valable en dehors des pistes balisées et ouvertes)

MASSIF : Pays-Basque

Rédigé le jeudi 9 avril 2026 à 16h

Estimation des risques pour le : VENDREDI 10 AVRIL

PEU D'EVOLUTION : NEIGE DE PRINTEMPS.

2

1 → 2

N O E S

Indice de risque faible évoluant en limité.

Départs spontanés : en neige humide, rare avalanche de fond possible.

Déclenchements provoqués : en neige humide.

Indices de risque : 5 très fort - 4 fort - 3 marqué - 2 limité - 1 faible -- En noir : les pentes les plus dangereuses

Stabilité du manteau neigeux

Situation avalancheuse typique : neige humide — avalanches de fond

Départs spontanés : **en neige humide**.
- activité avalancheuse **inexistante ou très rare au petit matin** suite à un **regel efficace** du manteau neigeux en place.
- **départs ponctuels de neige humide** en secteurs **raides près des rochers et des zones déneigées**, en **est à sud en matinée, sud à ouest l'après-midi**. Avalanches **généralement de petite taille**, **avalanche de fond de taille moyenne possible** en partant d'une **accumulation au plus haut du massif** et **entraînant la neige humide et lourde mobilisable en contrebas** (plutôt l'après-midi).

Déclenchements provoqués :
- **peu probables au petit matin** après un **bon regel nocturne**.
- au fil des heures de la journée, **au soleil et dans la douceur ambiante**, il devient **de plus en plus facile** pour un skieur ou randonneur de **déclencher des coulées ou petites avalanches de neige humide**. Une avalanche de **taille moyenne** peut **localement** être déclenchée dans les **pentes sud à sud-ouest raides sous le pic d'Anie** durant l'après-midi.

Autres : neige **dure et regelée** propice aux **glissades en tout début de matinée**. **Ponts de neige** et **corniches** encore en place devenant **fragiles au soleil.**

Qualité de la neige

Enneigement : encore bon pour la saison grâce à une fonte lente. Débutant vers 1600m en nord, 1800m en sud.
État de la neige : neige de printemps, poursuite de l'humidification en profondeur. Dure et regelée au petit matin, ramollissant vite au soleil dans la douceur ambiante, devenant lourde et très humide. Effets du soleil et de la douceur un peu plus lent dans les pentes nord raides sous le pic d'Anie et sous le pic d'Orhy.

Aperçu météo pour le vendredi 10 avril

Temps sec et encore bien doux. Le vent de sud à sud-ouest se lève en fin de journée et nuit suivante.

	nuit	matin	après-midi	soir
Pluie-Neige				
Iso 0 °C	3 300 m	3 400 m	3 400 m	3 400 m
Vent 1000 m	10 km/h	10 km/h	5 km/h	15 km/h
Vent 2000 m	25 km/h	30 km/h	35 km/h	45 km/h

Épaisseur de neige hors-piste

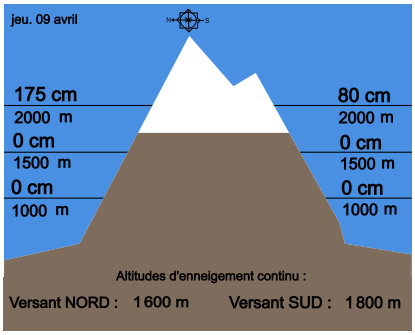

Précipitations à 1800 m

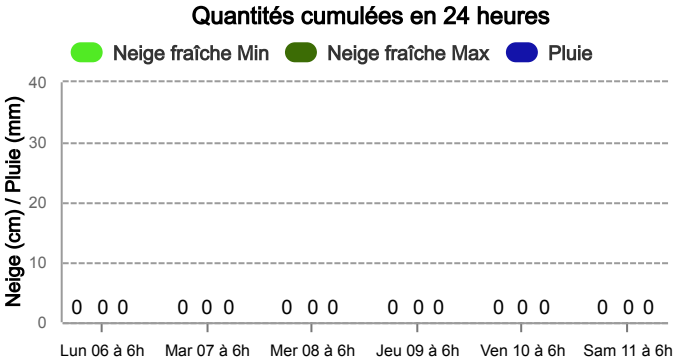

Tendance du samedi 11 avril

2

Indice de risque limité

Plus de nuages, quelques gouttes de pluie l'après-midi : maintien d'un risque faible à limité en journée.
Par contre, augmentation du risque en cours de nuit de samedi à dimanche avec les nouvelles chutes de neige attendues à basse altitude.

Pour consulter la vigilance en cours, veuillez vous rendre sur le site https://vigilance.meteofrance.fr/fr

Météo-France - 73 avenue de Paris, 94165 Saint-Mandé cedex - Contact : contact@meteo.fr

Rédigé par Météo-France avec la contribution des observateurs du réseau nivo-météorologiques. Partenariat : ANMSM (Maires de Stations de Montagne), DSF (Domaines Skiables de France), ADSP (Directeurs de Pistes et de la Sécurité des Stations de Sports d'Hiver) et autres acteurs de la montagne.

Bulletin neige & avalanches par téléphone au **0 892 68 10 20** Service 0,35 € / min + prix appel

RÉPUBLIQUE FRANÇAISE
Liberté Égalité Fraternité

METEO FRANCE
À VOS CÔTÉS, DANS UN CLIMAT QUI CHANGE

Bulletin d'estimation du risque d'avalanche

(valable en dehors des pistes balisées et ouvertes)

MASSIF : Pays-Basque

Rédigé le jeudi 9 avril 2026 à 16h

Conditions nivo-météo des 7 derniers jours

	ven. 03/04				sam. 04/04				dim. 05/04				lun. 06/04				mar. 07/04				mer. 08/04				jeu. 09/04			
	03h	09h	15h	21h	03h	09h	15h	21h	03h	09h	15h	21h	03h	09h	15h	21h	03h	09h	15h	21h	03h	09h	15h	21h	03h	09h	15h	21h
Météo																												
Vent (km/h)	55	35	20	15	10	10	15	20	25	30	30	30	25	25	40	55	60	50	20	30	15	10	10	10	10	15	25	30
à 2000m																												
Vent (km/h)	30	20	10	10	5	5	5	10	10	10	2	10	10	10	10	15	25	25	10	10	5	5	2	2	5	5	10	10
à 1000m																												

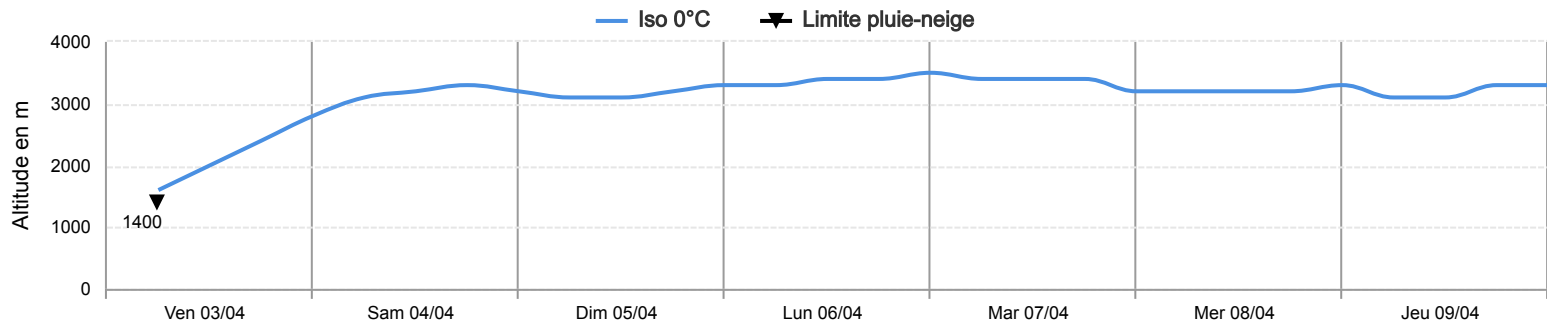

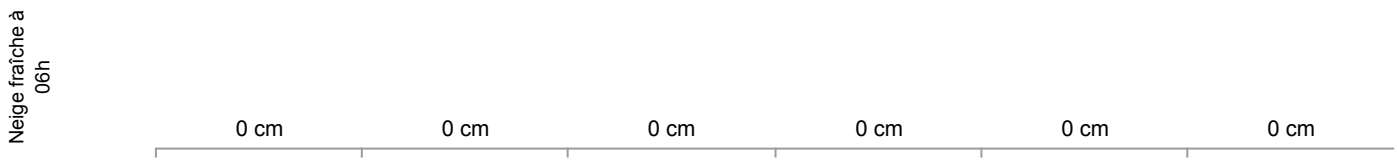

Risque d'avalanche	ven. 03/04	sam. 04/04	dim. 05/04	lun. 06/04	mar. 07/04	mer. 08/04	jeu. 09/04
	3	2	2	2	2	2	2

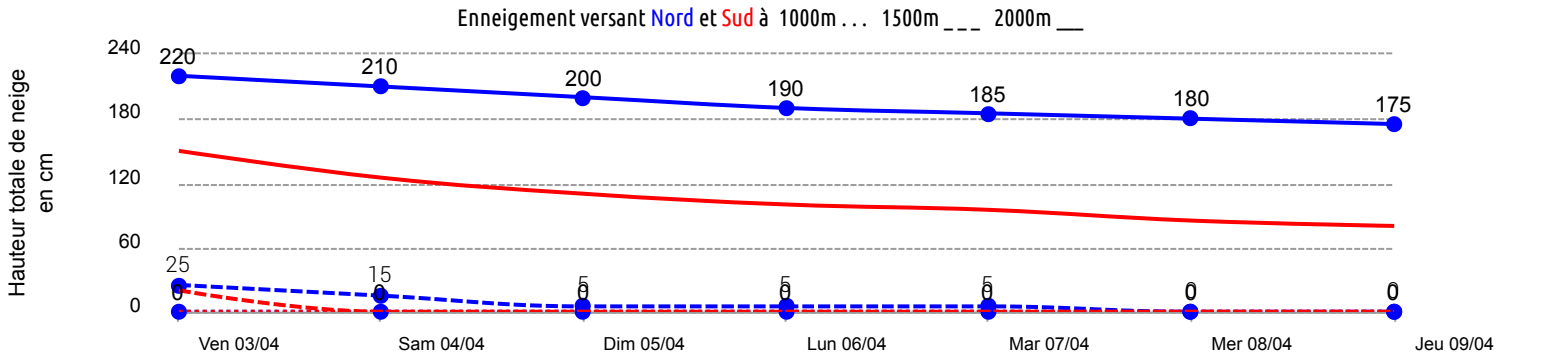

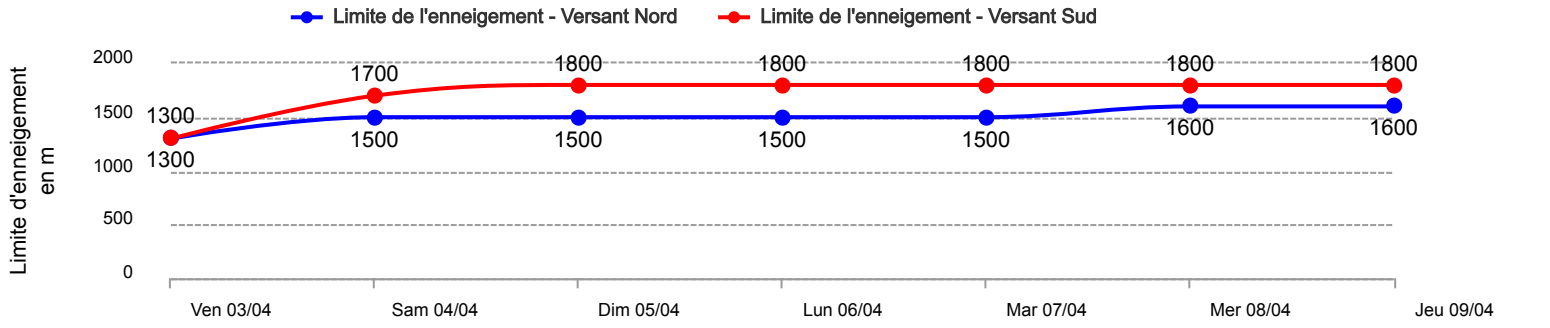

Pour consulter la vigilance en cours, veuillez vous rendre sur le site https://vigilance.meteofrance.fr/fr

Météo-France - 73 avenue de Paris, 94165 Saint-Mandé cedex - Contact : contact@meteo.fr

Rédigé par Météo-France avec la contribution des observateurs du réseau nivo-météorologiques. Partenariat : ANMSM (Maires de Stations de Montagne), DSF (Domaines Skiables de France), ADSP (Directeurs de Pistes et de la Sécurité des Stations de Sports d'Hiver) et autres acteurs de la montagne.

Bulletin neige & avalanches par téléphone au
0 892 68 10 20 Service 0,35 € / min + prix appel