RÉPUBLIQUE FRANÇAISE
*Liberté Égalité Fraternité*

METEO FRANCE
À VOS CÔTÉS, DANS UN CLIMAT QUI CHANGE

# Bulletin d'estimation du risque d'avalanche
## (valable en dehors des pistes balisées et ouvertes)

# MASSIF : Ubaye

Rédigé le jeudi 9 avril 2026 à 16h

## Estimation des risques pour le : VENDREDI 10 AVRIL

**CONDITIONS PRINTANIÈRES. DÉPARTS EN NEIGE HUMIDE PARFOIS TRÈS VOLUMINEUX**

3

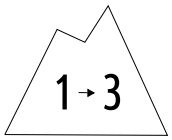


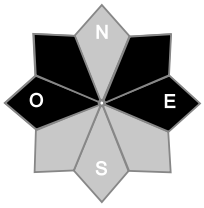


Indice de risque faible évoluant en marqué.

**Départs spontanés :** en neige humide, parfois linéaires et de grande taille

**Déclenchements provoqués :** départs ponctuels en neige humide ou avalanches de plaque dans la niege d'aspect humifiée, facile à déclencher

Indices de risque : 5 très fort - 4 fort - 3 marqué - 2 limité - 1 faible -- En noir : les pentes les plus dangereuses

## Stabilité du manteau neigeux

**Situation avalancheuse typique :** neige humide couche fragile persistante

**Départs spontanés :** - départs généralement ponctuels en neige humide, de taille petite à moyenne. Peu probables en tout début de journée après un bon regel nocturne, puis augmentation suivant la course du soleil. En pentes raides, toutes orientations et altitude, plutôt près des rochers.
- départs linéaires, cassures pouvant être larges et épaisses, engendrant des avalanches de taille moyenne à grande. En seconde partie de journée plus particulièrement au-dessus de 2200/2400 m, dans les orientations est à nord-est et ouest à nord-ouest bien réchauffées. En effet l'humidification gagne en profondeur et peut atteindre désormais pour la 1ere fois les couches fragiles enfouies à la base du manteau neigeux.

**Déclenchements provoqués :** le manteau neigeux est bien stable le matin. Les déclenchements d'avalanches concernent ensuite les pentes raides ensoleillées.
- avalanches de plaque dans la neige d'aspect humidifiée pouvant être déclenchées par un seul skieur évoluant tardivement. Orientations privilégiées est / nord / ouest d'altitude. Taille moyenne, voire grande.
- départs ponctuels en neige humide / pourrie sous les skis. Taille petite à moyenne.

## Qualité de la neige

**Enneigement** proche des normales pour la saison.

**Enneigement skiable** généralement à partir de 1800 m en terrain favorable et 2200/2300 m en adrets peu pentus.

**État de la neige en surface** : manteau neigeux printanier avec un bon regel nocturne, s'humidifiant rapidement en journée. Neige restée sèche seulement en orientations raides et plein nord de haute altitude, mais généralement fortement durcie par le vent.

## Aperçu météo pour le vendredi 10 avril

| | nuit | matin | après-midi | soir |
|---|---|---|---|---|
| | | | | |
| | Toujours chaud et sec. Soleil voilé. Vent de nord à ouest, faible à modéré. | | | |
| **Pluie-Neige** | | | | |
| **Iso 0 °C** | 3 400 m | 3 300 m | 3 400 m | 3 400 m |
| **Vent 2000 m** | ↓ 15 km/h | ↘ 15 km/h | ↘ 25 km/h | ↘ 10 km/h |
| **Vent 3000 m** | ↓ 40 km/h | ↓ 30 km/h | → 30 km/h | ↘ 20 km/h |

## Épaisseur de neige hors-piste

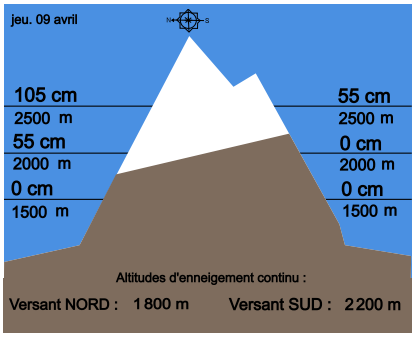


## Précipitations à 1800 m

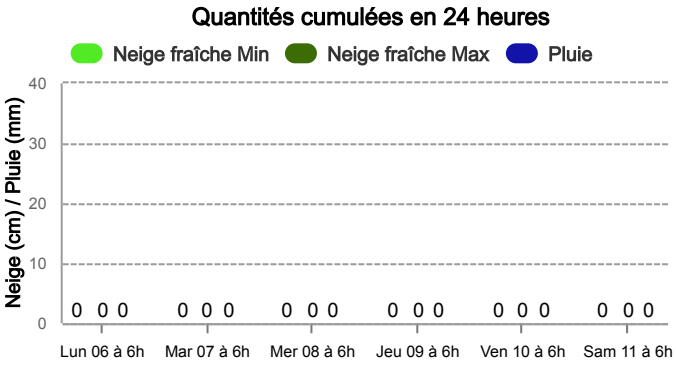


## Tendance du samedi 11 avril

3

**Indice de risque marqué**

Poursuite de conditions printanières et de l'humidification en profondeur du manteau neigeux. Grandes avalanches possibles. Risque restant marqué.

Pour consulter la vigilance en cours, veuillez vous rendre sur le site https://vigilance.meteofrance.fr/fr

Météo-France - 73 avenue de Paris, 94165 Saint-Mandé cedex - Contact : contact@meteo.fr

Rédigé par Météo-France avec la contribution des observateurs du réseau nivo-météorologiques. Partenariat : ANMSM (Maires de Stations de Montagne), DSF (Domaines Skiables de France), ADSP (Directeurs de Pistes et de la Sécurité des Stations de Sports d'Hiver) et autres acteurs de la montagne.

Bulletin neige & avalanches par téléphone au
**0 892 68 10 20** Service 0,35 € / min + prix appel

RÉPUBLIQUE FRANÇAISE
*Liberté Égalité Fraternité*

METEO FRANCE
À VOS CÔTÉS, DANS UN CLIMAT QUI CHANGE

# Bulletin d'estimation du risque d'avalanche

## (valable en dehors des pistes balisées et ouvertes)

# MASSIF : Ubaye

Rédigé le jeudi 9 avril 2026 à 16h

## Conditions nivo-météo des 7 derniers jours

| | ven. 03/04 | | | | sam. 04/04 | | | | dim. 05/04 | | | | lun. 06/04 | | | | mar. 07/04 | | | | mer. 08/04 | | | | jeu. 09/04 | | | |
|---|---|---|---|---|---|---|---|---|---|---|---|---|---|---|---|---|---|---|---|---|---|---|---|---|---|---|---|---|
| | 03h | 09h | 15h | 21h | 03h | 09h | 15h | 21h | 03h | 09h | 15h | 21h | 03h | 09h | 15h | 21h | 03h | 09h | 15h | 21h | 03h | 09h | 15h | 21h | 03h | 09h | 15h | 21h |
| Météo | | | | | | | | | | | | | | | | | | | | | | | | | | | | |
| Vent (km/h) | 20 | 30 | 30 | 30 | 20 | 10 | 15 | 10 | 15 | 20 | 30 | 35 | 30 | 20 | 20 | 15 | 10 | 10 | 15 | 10 | 10 | 15 | 10 | 10 | 15 | 20 | 25 | 35 |
| à 3000m | | | | | | | | | | | | | | | | | | | | | | | | | | | | |
| Vent (km/h) | 10 | 15 | 15 | 10 | 10 | 5 | 15 | 5 | 5 | 10 | 20 | 15 | 10 | 10 | 20 | 5 | 5 | 5 | 20 | 5 | 5 | 5 | 15 | 5 | 5 | 5 | 15 | 10 |
| à 2000m | | | | | | | | | | | | | | | | | | | | | | | | | | | | |

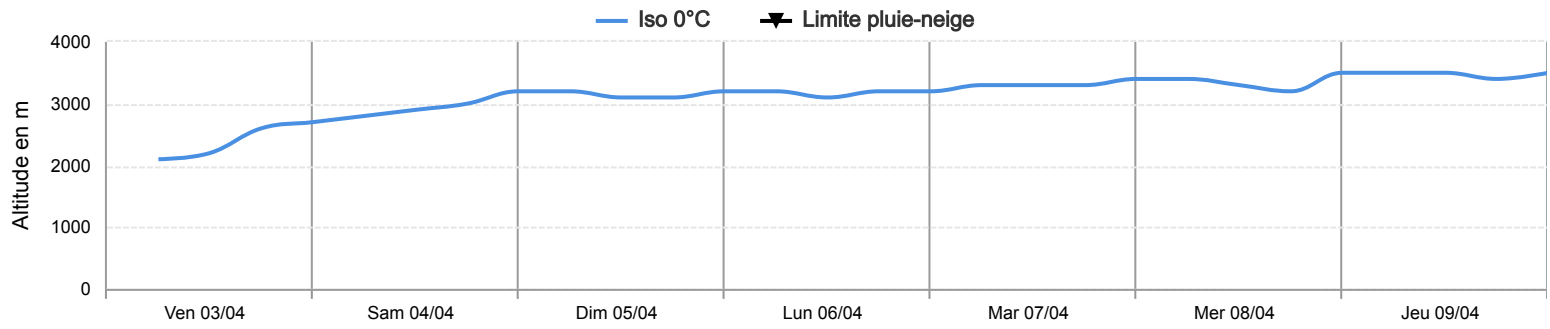


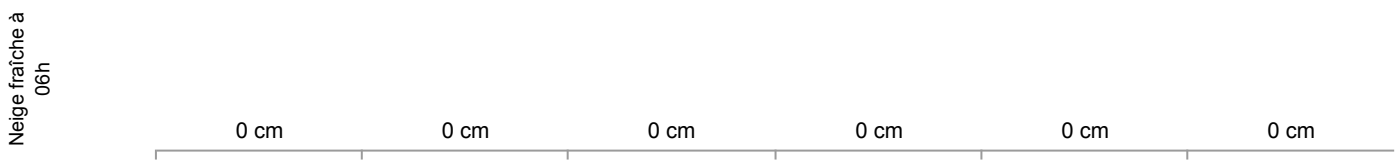


| Risque d'avalanche | ven. 03/04 | sam. 04/04 | dim. 05/04 | lun. 06/04 | mar. 07/04 | mer. 08/04 | jeu. 09/04 |
|---|---|---|---|---|---|---|---|
| | 1 | 2 | 2 | 2 | 2 | 2 | 3 |

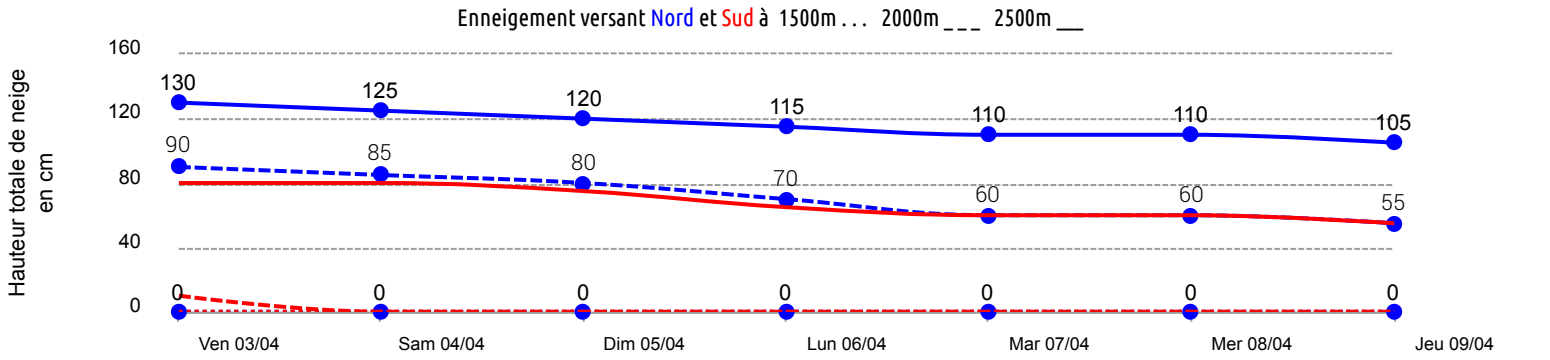


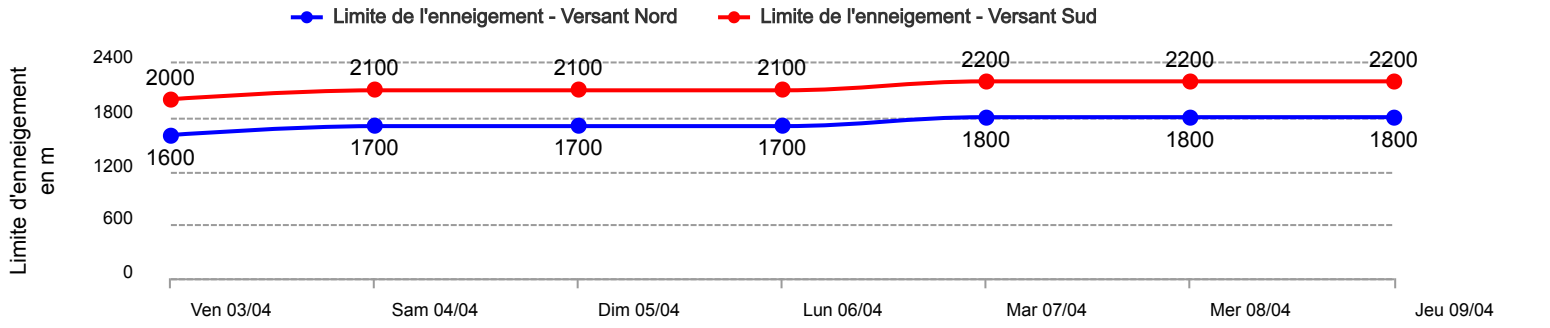


Pour consulter la vigilance en cours, veuillez vous rendre sur le site https://vigilance.meteofrance.fr/fr


**Météo-France - 73 avenue de Paris, 94165 Saint-Mandé cedex - Contact : contact@meteo.fr**



Rédigé par Météo-France avec la contribution des observateurs du réseau nivo-météorologiques. Partenariat : ANMSM (Maires de Stations de Montagne), DSF (Domaines Skiables de France), ADSP (Directeurs de Pistes et de la Sécurité des Stations de Sports d'Hiver) et autres acteurs de la montagne.



Bulletin neige & avalanches par téléphone au
0 892 68 10 20 Service 0,35 € / min + prix appel